Dokumentation zur Modifikation der Lebensweltlich orientierten Räume (LOR)

Inhalt und Bearbeitung

Senatsverwaltung für Stadtentwicklung und Wohnen Berlin, Referat I A
Fehrbelliner Platz 4, 10707 Berlin
Ansprechpartner: Tobias Schäfer, I A 18 | Tel.: 030 90139-5838| tobias.schaefer@sensw.berlin.de
Henning Roser
Katrin Ziesing
Thorsten Tonndorf

mit

Amt für Statistik Berlin-Brandenburg, Referat 41B – Kommunalstatistik
Alt-Friedrichsfelde 60, 10315 Berlin
Ansprechpartner: Frank Gödicke | Tel.: 030 9021 3903 | einwohner@statistik-bbb.de
Andrea Weinert
Katja Niemann-Arendt

In Zusammenarbeit mit

RegioKontext GmbH
Kantstr. 92, 10627 Berlin
Ansprechpartner: Hendrik Schlichting | Tel.: 030 5034 8444 | buero@regiokontext.de
Julia Grünky
Simon Wieland
Arnt von Bodelschwingh

Dr. Paul Hebes – Wissensbasierte Planung
Blankenburger Chaussee 83C, 13125 Berlin
Ansprechpartner: Dr. Paul Hebes | Tel.: 030 9190 2603 | paul.hebes@wissensbasiert.de

Oktober 2020

Inhaltsverzeichnis

1 Einführung: Rolle der LOR 5

2 Anlass der Modifikation 6

3 Ziele und Kriterien des Prozesses 6

4 Verfahren 8

4.1 Akteure 8

4.2 Vorgehen 8

4.3 Datenbereitstellung 10

5 LOR-Systematik vor der Modifikation 11

5.1 Prognoseräume (PGR) 13

5.2 Bezirksregionen (BZR) 14

5.3 Planungsräume (PLR) 15

6 LOR-Systematik nach der Modifikation 16

6.1 Gesamtstädtischer Überblick 16

6.1.1 Prognoseräume nach der Modifikation 16
6.1.2 Bezirksregionen nach der Modifikation 17
6.1.3 Planungsräume nach der Modifikation 18

6.2 Neue LOR-Nummerierung 22

6.3 LOR-Systematik in den Bezirken 23

6.3.1 Bezirk Mitte 23
6.3.2 Bezirk Friedrichshain-Kreuzberg 28
6.3.3 Bezirk Pankow 33
6.3.4 Bezirk Charlottenburg-Wilmersdorf 38
6.3.5 Bezirk Spandau 43
6.3.6 Bezirk Steglitz-Zehlendorf 48
6.3.7 Bezirk Tempelhof-Schöneberg 53
6.3.8 Bezirk Neukölln 58
6.3.9 Bezirk Treptow-Köpenick 63
6.3.10 Bezirk Marzahn-Hellersdorf 68
6.3.11 Bezirk Lichtenberg 73
6.3.12 Bezirk Reinickendorf 78

Anhang 83

Danksagung 83
Tabellarische Übersicht der neuen LOR-Systematik ab 2021 84
Übersicht zu Planungsräumen – vor und nach der Modifikation 107

Abbildungsverzeichnis

Abbildung 1: Anlass für die Modifikation der LOR 6
Abbildung 2: Ziele und Kriterien der Modifikation 6
Abbildung 3: Beteiligte Akteure bei der Modifikation und Abstimmung 8
Abbildung 4: Projektphasen und -schritte 9
Abbildung 5: LOR-Systematik 2019 - vor der Modifikation 12
Abbildung 6: Veränderung der Verteilung innerhalb der EW-Größenklassen, PGR 17
Abbildung 7: Veränderung der Verteilung innerhalb der EW-Größenklassen, BZR 18
Abbildung 8: Veränderung der Verteilung innerhalb der EW-Größenklassen, PLR 19
Abbildung 9: LOR-Systematik ab 2021 - nach der Modifikation 21
Abbildung 10: Neue Nummerierungssystematik der LOR ab 2021 22
Abbildung 11: LOR in Mitte ab 2021 24
Abbildung 12: LOR in Friedrichshain-Kreuzberg ab 2021 29
Abbildung 13: LOR in Pankow ab 2021 34
Abbildung 14: LOR in Charlottenburg-Wilmersdorf ab 2021 39
Abbildung 15: LOR in Spandau ab 2021 44
Abbildung 16: LOR in Steglitz-Zehlendorf ab 2021 49
Abbildung 17: LOR in Tempelhof-Schöneberg ab 2021 54
Abbildung 18: LOR in Neukölln ab 2021 59
Abbildung 19: LOR in Treptow-Köpenick ab 2021 64
Abbildung 20: LOR in Marzahn-Hellersdorf ab 2021 69
Abbildung 21: LOR in Lichtenberg ab 2021 74
Abbildung 22: LOR in Reinickendorf ab 2021 79

Tabellenverzeichnis

Tabelle 1: Übersicht über die LOR-Systematik vor der Modifikation 11
Tabelle 2: Übersicht über die Prognoseräume nach Berliner Bezirken, vor der Modifikation 13
Tabelle 3: Übersicht über die Bezirksregionen nach Berliner Bezirken, vor der Modifikation 14
Tabelle 4: Übersicht über die Planungsräume nach Berliner Bezirken, vor der Modifikation 15
Tabelle 5: Gesamtstadt - Übersicht zu LOR-Ebenen vor und nach der Modifikation 16
Tabelle 6: Übersicht über die Prognoseräume nach Berliner Bezirken, nach der Modifikation 17
Tabelle 7: Übersicht über die Bezirksregionen nach Berliner Bezirken, nach der Modifikation 18
Tabelle 8: Übersicht über die Planungsräume nach Berliner Bezirken, nach der Modifikation 20
Tabelle 9: Mitte - Übersicht zu Prognoseräumen vor und nach der Modifikation 25
Tabelle 10: Mitte - Übersicht zu Bezirksregionen vor und nach der Modifikation 26
Tabelle 11: Mitte - Übersicht zu Planungsräumen vor und nach der Modifikation 27
Tabelle 12: Friedrichshain-Kreuzberg - Übersicht zu Prognoseräumen vor und nach der Modifikation 30
Tabelle 13: Friedrichshain-Kreuzberg - Übersicht zu Bezirksregionen vor und nach der Modifikation 31
Tabelle 14: Friedrichshain-Kreuzberg - Übersicht zu Planungsräumen vor und nach der Modifikation 32
Tabelle 15: Pankow - Übersicht zu Prognoseräumen vor und nach der Modifikation 35
Tabelle 16: Pankow - Übersicht zu Bezirksregionen vor und nach der Modifikation 36
Tabelle 17: Pankow - Übersicht zu Planungsräumen vor und nach der Modifikation 37
Tabelle 18: Charlottenburg-Wilmersdorf – Übersicht zu Prognoseräumen vor und nach der Modifikation 40
Tabelle 19: Charlottenburg-Wilmersdorf - Übersicht zu Bezirksregionen vor und nach der Modifikation . 41
Tabelle 20: Charlottenburg-Wilmersdorf - Übersicht zu Planungsräumen vor und nach der Modifikation 42
Tabelle 21: Spandau - Übersicht zu Prognoseräumen vor und nach der Modifikation 45
Tabelle 22: Spandau - Übersicht zu Bezirksregionen vor und nach der Modifikation 46
Tabelle 23: Spandau - Übersicht zu Planungsräumen vor und nach der Modifikation 47
Tabelle 24: Steglitz-Zehlendorf - Übersicht zu Prognoseräumen vor und nach der Modifikation 50
Tabelle 25: Steglitz-Zehlendorf - Übersicht zu Bezirksregionen vor und nach der Modifikation 51
Tabelle 26: Steglitz-Zehlendorf - Übersicht zu Planungsräumen vor und nach der Modifikation 52
Tabelle 27: Tempelhof-Schöneberg - Übersicht zu Prognoseräumen vor und nach der Modifikation 55
Tabelle 28: Tempelhof-Schöneberg - Übersicht zu Bezirksregionen vor und nach der Modifikation 56
Tabelle 29: Tempelhof-Schöneberg - Übersicht zu Planungsräumen vor und nach der Modifikation 57
Tabelle 30: Neukölln - Übersicht zu Prognoseräumen vor und nach der Modifikation 60
Tabelle 31: Neukölln - Übersicht zu Bezirksregionen vor und nach der Modifikation 61
Tabelle 32: Neukölln - Übersicht zu Planungsräumen vor und nach der Modifikation 62
Tabelle 33: Treptow-Köpenick - Übersicht zu Prognoseräumen vor und nach der Modifikation 65
Tabelle 34: Treptow-Köpenick - Übersicht zu Bezirksregionen vor und nach der Modifikation 66
Tabelle 35: Treptow-Köpenick - Übersicht zu Planungsräumen vor und nach der Modifikation 67
Tabelle 36: Marzahn-Hellersdorf - Übersicht zu Prognoseräumen vor und nach der Modifikation 70
Tabelle 37: Marzahn-Hellersdorf - Übersicht zu Bezirksregionen vor und nach der Modifikation 71
Tabelle 38: Marzahn-Hellersdorf - Übersicht zu Planungsräumen vor und nach der Modifikation 71
Tabelle 39: Lichtenberg - Übersicht zu Prognoseräumen vor und nach der Modifikation 75
Tabelle 40: Lichtenberg - Übersicht zu Bezirksregionen vor und nach der Modifikation 76
Tabelle 41: Lichtenberg - Übersicht zu Planungsräumen vor und nach der Modifikation 77
Tabelle 42: Reinickendorf - Übersicht zu Prognoseräumen vor und nach der Modifikation 80
Tabelle 43: Reinickendorf - Übersicht zu Bezirksregionen vor und nach der Modifikation 81
Tabelle 44: Reinickendorf - Übersicht zu Planungsräumen vor und nach der Modifikation 82

1 Einführung: Rolle der LOR

Die „lebensweltlich orientierten Räume“ (LOR) bilden seit dem Senatsbeschluss Nr. 3798/2006 vom 01.08.2006 die „räumliche Grundlage für Planung, Prognose und Beobachtung demografischer und sozialer Entwicklungen in Berlin“.[1] Dies betrifft insbesondere die Umsetzung von (sozial-)raumbezogenen Planungen sowie die damit verbundene Bereitstellung kleinräumiger soziostruktureller Daten der amtlichen Statistik durch das Amt für Statistik Berlin-Brandenburg (AfS) bzw. von Fachdaten durch die zuständigen Senatsfachverwaltungen. In einem aufwändigen Prozess sind die LOR in den Jahren 2004 bis 2006 mit zahlreichen Akteuren abgestimmt worden. Die Systematik der LOR besteht saus

- **Planungsräumen (PLR) als unterste Ebene, ursprünglich 447 Räume,**
- **Bezirksregionen (BZR) als mittlere Ebene, ursprünglich 134 Räume,**
- **Prognoseräumen (PGR) als obere Ebene, ursprünglich 60 Räume.**

Diese räumlichen Ebenen sind hierarchisch gegliedert. In der Regel besteht jeder Prognoseraum aus mehreren Bezirksregionen und diese wiederum aus mehreren Planungsräumen.

Die LOR sind eingebettet in den Kontext des Berliner **Regionalen Bezugsystems** des Amts für Statistik Berlin-Brandenburg (AfS). Die Anknüpfungsfähigkeit an Adress- und Blockdaten erlaubt Analysen auf unterschiedlichen Aggregatsebenen.

Die Systematik der LOR mit hierarchisch gegliederten Raumeinheiten ermöglicht eine **effiziente und flexible Verwendung für vielfältige Aufgaben der öffentlichen Verwaltung auf Senats- und Bezirksebene**, aber auch für sonstige Belange. Beispielhafte Anwendungsfelder sind die Bevölkerungsprognose für das Land Berlin und die Bezirke, fachliche Entwicklungsplanungen z. B. für Einrichtungen der sozialen Infrastruktur, Monitoring Soziale Stadtentwicklung (MSS), Bezirksregionenprofile (BZRP), Wohnungsmarktanalysen, Umweltgerechtigkeitsanalysen etc. Dies unterstreichen die breite Nutzung und die fachliche Bedeutung der Daten auf LOR-Basis.

Bei der Definition und Abgrenzung der Räume standen homogene Binnenstrukturen im Vordergrund. Das betrifft zum einen **bauliche Einheitlichkeit**, etwa mit Blick auf die Siedlungstypen. Zum anderen berücksichtigen die LOR auch **soziale Homogenität** (ähnliche sozioökonomische Strukturen). Dadurch erlangen Datenanalysen und etwaig sichtbare Dynamiken eine höhere Aussagekraft auch mit Blick auf Ursache-Wirkungsbeziehungen.

Die LOR sind nach 13 Jahren eine weit verbreitete und akzeptierte Systematik amtlicher Statistik und fachlicher Planungen. Seit 2006 waren die LOR-Zuschnitte unverändert und bieten eine zuverlässige räumliche Auswertungssystematik.

[1] Senatsverwaltung für Stadtentwicklung und Wohnen, http://www.stadtentwicklung.berlin.de/planen/basisdaten_stadtentwicklung/lor/index.shtml, letzter Zugriff: 11.05.20

2 Anlass der Modifikation

Aufgrund der **dynamischen (Einwohner-)Entwicklung** Berlins in den letzten Jahren, dem auch **für die Zukunft zu erwartenden Bevölkerungswachstum** und der **geplanten städtebaulichen Entwicklung neuer Quartiere** ist eine Anpassung der LOR erforderlich. Ziel ist es, stadträumliche Einheiten mit jeweils möglichst homogenen soziodemografischen Strukturen zu bestimmen und damit eine verbesserte Eignung des LOR-Systems für Zwecke der raumbezogenen und sozialraumorientierten Planung sowie der amtlichen Statistik zu erreichen.

Um raumbezogene, aussagekräftige **Zeitreihenvergleiche** auch zukünftig erstellen zu können, müssen die Effekte neuer (Wohn-)Gebiete räumlich abgrenzbar integriert werden. Auch durch die Veränderung von Rahmenbedingungen (z. B. Bereitstellung von Arbeitsmarktdaten nur noch für Raumeinheiten mit mindestens 1.000 Personen) war eine systematische Überprüfung und teilweise Anpassung der räumlichen Abgrenzungen der LOR erforderlich.

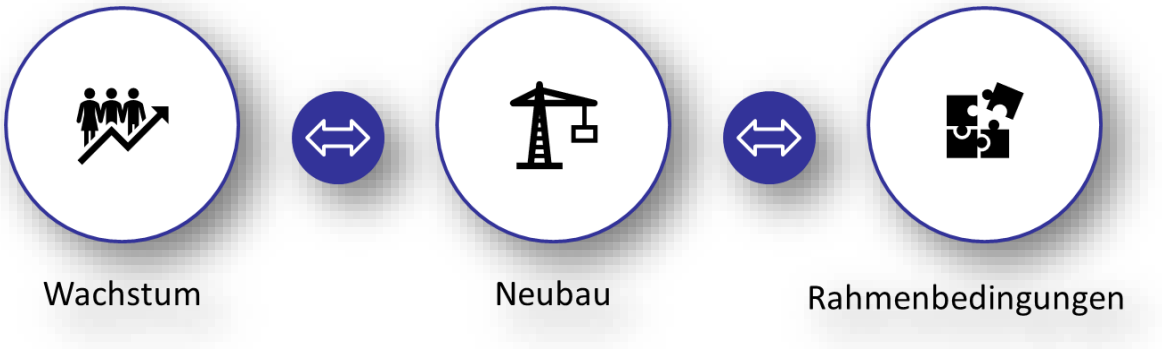

Abbildung 1: Anlass für die Modifikation der LOR

Quelle: eigene Darstellung

3 Ziele und Kriterien des Prozesses

Die Überarbeitung der LOR soll die Aussagekraft der Daten und fachlichen Analysen (wieder) erhöhen und den Anwenderinnen und Anwendern der Systematik die inhaltliche Arbeit mit den LOR erleichtern. Das gut funktionierende System der in 2006 aufgestellten LOR-Räume wurde dafür auf der bestehenden Grundlage modifiziert. Um die verschiedenen bestehenden Monitoring- und Indikatorensysteme für einen möglichst großen Zeitraum erhalten zu können, wurde eine moderate Modifikation angestrebt. Es galt die arbeitsleitende Prämisse: „so viel wie nötig, so wenig wie möglich“. Für die Modifikation spielten sowohl quantitative Erwägungen als auch qualitative Aspekte der Sozialraumorientierung eine Rolle.

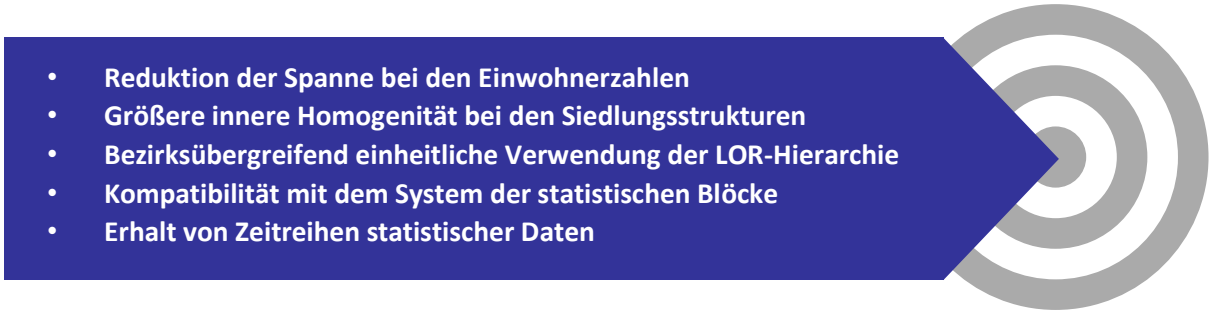

Abbildung 2: Ziele und Kriterien der Modifikation

Quelle: eigene Darstellung

Entsprechend wurden die folgenden übergeordneten Ziele verfolgt und Kriterien angewandt:

- **Reduktion der Spanne bei den Einwohnerzahlen**

  Sie soll die Vergleichbarkeit der LOR, vor allem der Planungsräume, innerhalb der Ebenen erhöhen, sowohl bei bezirklichen als auch gesamtstädtischen Analysen. Die Beschränkung auf eine kleinere EW-Spanne soll die Homogenität und Aussagekraft von Monitorings erhöhen. Mit steigender EW-Zahl steigt auch die Wahrscheinlichkeit, dass sich unterschiedliche (gegenläufige) sozioökonomische Entwicklungen nivellieren und nicht mehr abbilden lassen.

  Entsprechend den Vorgaben der Bundesagentur für Arbeit für die Bereitstellung kleinräumiger Daten (bspw. Zahlen zur Arbeitslosigkeit und Beschäftigung) und für eine sichere Datenaufbereitung innerhalb verschiedener Monitoring- und Generierungsverfahren ist eine Mindestgröße der Räume von 1.000 Einwohnerinnen und Einwohnern (EW) erforderlich. Die Schwankungen in der EW-Entwicklung in kleinen Räumen in den letzten Jahren führten zur Setzung eines unteren Richtwerts von 2.500 Einwohnerinnen und Einwohnern. Zur Angleichung der Bevölkerungsgröße der Planungsräume wurde für die Planungsräume als oberer Richtwert 10.000 EW gewählt.

  Für Bezirksregionen und Prognoseräume wurden keine Orientierungswerte für EW-Zahlen festgelegt. Die Bezirke wurden bei Änderungswünschen aber gebeten, sich an bestehenden (gesamtstädtischen) Mittelwerten zu orientieren, um dem Ziel der Homogenität der LOR zu entsprechen.

- **Größere innere Homogenität bei den Siedlungsstrukturen**

  Insbesondere durch größere Neubauvorhaben kann es kleinräumig zur Ausdifferenzierung der Bevölkerung kommen, etwa in sozialer, aber auch ökonomischer Hinsicht. Entsprechend sollten geänderte, bestehende und sich absehbar verändernde Siedlungsstrukturen berücksichtigt werden, bspw. durch Abgrenzung neuer Planungsräume für ausgewählte „neue Stadtquartiere“. Auch Barrieren bzw. Begrenzungen (z. B. Bahntrassen und Hauptstraßen) und homogene Binnenstrukturen (z. B. einheitliche sozioökonomische Strukturen) wurden beachtet.

- **Bezirksübergreifend einheitliche Verwendung der LOR-Hierarchie**

  Eine homogene Systematik erhöht die Anwendungsfreundlichkeit und Transparenz. Eine einheitliche Hierarchie und konsistente Namensgebung, mit selbstsprechenden Bezeichnungen, unterstützt die Orientierung in der LOR-Systematik und dessen Nutzung für einen breiten Akteurskreis. Das Kapitel „Neue LOR-Nummerierung“ beschreibt die Änderungen.

- **Kompatibilität mit dem System der statistischen Blöcke des Regionalen Bezugsystems des AfS**

  Amtliche Daten müssen von der Blockebene auf die LOR übertragbar sein. Aus diesem Grund dürfen die LOR statistische Blöcke nicht schneiden. In wenigen Fällen wurden in Abstimmung mit dem Geoservice des AfS statistische Blöcke neu geschnitten, um beispielweise eine Abgrenzung von großen Wohnungsneubauvorhaben zu ermöglichen.

- **Erhalt von Zeitreihen statistischer Daten**

  Bei der Modifikation der LOR war eine vorausschauende Perspektive stets arbeitsleitend. Für die durchgeführte Modifikation war es von hoher Bedeutung, dass diese robust, also von langer (Einsatz-)Dauer ist. Damit verbunden ist das Ziel der Zeitreihenfähigkeit. Die notwendigen Neuzuschnitte von LOR waren so zu gestalten, dass für möglichst viele der LOR Daten zurückgerechnet werden können. Konkret wurde das Ziel der Zeitreihen-Erhaltung durch den Erhalt

einer hohen Anzahl bisheriger Strukturen und die Vermeidung von Block-Neuzuschnitten verfolgt. In der Regel wurden dazu die LOR geteilt oder zusammengelegt, um die ursprünglichen Abgrenzungen in der Systematik möglichst zu erhalten. Durch das geringfügige Antasten von statistischen Blöcken können Daten von dieser feinen räumlichen Ebene auch auf neue LOR-Abgrenzungen aggregiert werden.

4 Verfahren

4.1 Akteure

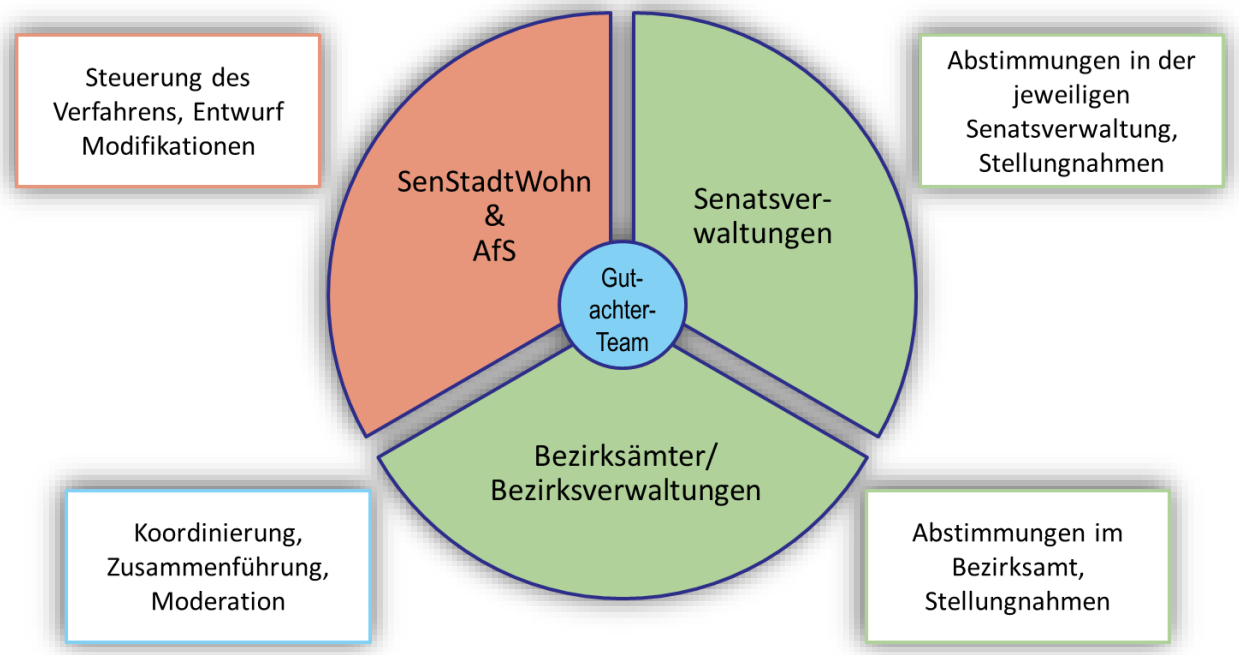

Abbildung 3: Beteiligte Akteure bei der Modifikation und Abstimmung

Quelle: eigene Darstellung

Als gemeinsames Projekt des Amts für Statistik Berlin-Brandenburg (AfS) und der Senatsverwaltung für Stadtentwicklung und Wohnen (SenStadtWohn), Referat I A Stadtentwicklungsplanung, wurde die Modifikation der LOR durchgeführt. Die Modifikation wurde durch ein externes Gutachter-/Projektteam begleitet. Die SenStadtWohn und das AfS haben sowohl den ersten Entwurf zur Modifikation erarbeitet als auch die Steuerung des Verfahrens federführend übernommen. Das Gutachterteam übernahm die Koordinierung aller Akteure, deren Beteiligung und das Zusammenführen der einzelnen Entwurfs-Versionen und Stellungnahmen (siehe Abbildung 3).

4.2 Vorgehen

Um die Modifikation erfolgreich durchzuführen, wurde eine berlinweite Beteiligung der beiden Verwaltungsebenen durchgeführt. Sowohl die Senatsverwaltungen des Landes Berlin als auch die Bezirksverwaltungen/Bezirksämter wurden als wichtige Akteure und Anwender der LOR einbezogen. Deren Expertise und Fachwissen zu sozialräumlichen Aspekten war wesentlich für den erfolgreichen Prozess. Beide Ebenen wurden gebeten, den durch SenStadtWohn/AfS erarbeiteten Entwurf der Modifikationen kritisch zu prüfen, in der eigenen Verwaltung abzustimmen und Stellungnahmen abzugeben, ob und wenn ja, welche Änderungen am Entwurf nötig seien.

Abbildung 4 zeigt den engen, iterativen Prozess, in dem sich alle beteiligten auf die neue LOR-Systematik ab 2021 geeinigt haben. Zunächst haben das AfS und die SenStadtWohn in einem intensiven Überarbeitungsprozess im Jahr 2019 untersucht, welche LOR modifiziert werden sollten, um die übergeordneten Ziele (siehe Abbildung 2) erreichen zu können. Dafür wurden zum **Prozessbeginn** ein Kriterienkatalog erarbeitet und entsprechend alle 448 bisherigen Planungsräume (PLR) entsprechend der quantitativen und qualitativen Kriterien (siehe Abbildung 4) überprüft. Im Ergebnis stand eine erste Anpassungsempfehlung für die Planungsräume.

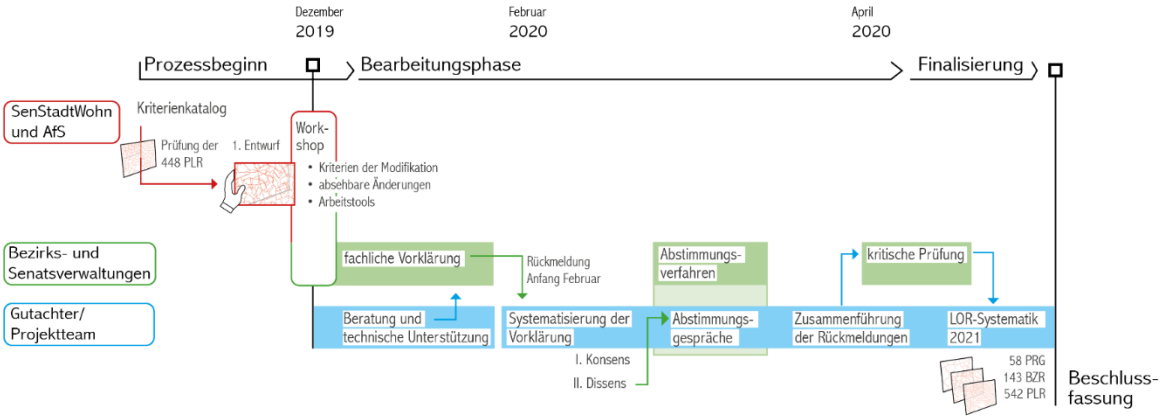

Abbildung 4: Projektphasen und -schritte
Quelle: eigene Darstellung

Um den Entwurf abzustimmen, galt es, in den zu beteiligenden Verwaltungen die fachlich zuständigen Ansprechpersonen zu identifizieren. In einem Schreiben im Oktober 2019 wurden daher die Senatsfach- und Bezirksverwaltungen schriftlich gebeten, Kontaktpersonen für die Modifikation zu benennen. In diesem Zuge wurden auch das Verfahren und die Ziele des Verfahrens knapp dargestellt. Im November wurden die Benannten zu einem Auftaktworkshop im Dezember 2019 eingeladen.

In dem Workshop, an dem über 30 der Eingeladenen teilnahmen, wurden das Projekt selbst sowie das geplante Abstimmungsverfahren erläutert. Zudem wurden die Kriterien der Modifikation und beispielhaft die daraus resultierenden absehbaren Änderungen vorgestellt und diskutiert. Zusätzlich wurden den Anwesenden die zu Prozessbeginn erarbeiteten und nun zur Verfügung gestellten Tools präsentiert, anhand derer die vorgeschlagenen Änderungen nachvollzogen und eigene Änderungsvorschläge angezeigt werden können. Die beiden Angebote umfassten den Einsatz der verwaltungsinternen Version des FIS-Broker[2] und eine interaktive Anwendung mit Tableau.[3] Beide Tools wurden von den Verwaltungen im weiteren Prozess intensiv genutzt.

Im Nachgang zum Workshop wurde die eigentliche **Bearbeitungsphase** initiiert. Die beteiligten Verwaltungen erhielten im Dezember 2019 die Unterlagen zum ersten Entwurf mit den LOR-Anpassungsempfehlungen. Die Ansprechpersonen wurden gebeten, bis Februar 2020 den Entwurf intern zu prüfen und mögliche Änderungsvorschläge an das Projektteam zurückzumelden. Änderungshinweise betrafen z. B. alternative Zuschnitte von PLR oder die vorgeschlagenen Namen der LOR. Während die Senatsverwaltungen mehrheitlich übergreifende Hinweise, ohne konkreten Raumbezug, gaben, hatten alle der zwölf Bezirke Stellungnahmen abgegeben, die bspw. spezifische Änderungen von LOR-Grenzen gegenüber dem ersten Entwurf vorsahen.

[2] https://www.stadtentwicklung.berlin.de/geoinformation/fis-broker/
[3] https://www.tableau.com/de-de

Während der ersten Bearbeitungsphase standen die SenStadtWohn, das AfS und das Projektteam den Bezirken beratend zur Seite, etwa um Änderungsvorschläge zu erläutern oder auch um technische Unterstützung bei Änderungsvorschlägen zu leisten. Es gab einen intensiven, meist bilateralen, Austausch zwischen den bezirklichen Verantwortlichen und dem Projektteam. Die auftretenden Fragen wurden gebündelt und in einer ersten Zwischeninfo, im Stil von FAQ, Ende Januar 2020 versandt. Auf diese Weise wurden alle Beteiligten über offene Punkte und Fragen sowie dazugehörige Antworten informiert. In dem Zusammenhang wurde auch klargestellt, dass die Modifikation der LOR zwar hauptsächlich auf die Ebene der Planungsräume abzielte, Bezirksregionen und – in Einzelfällen und nach Rücksprache – auch Prognoseräume jedoch ebenfalls modifiziert werden konnten.

Nach einer Sichtung aller sukzessiv eingetroffener Rückmeldungen gab es Ende Februar 2020 ein zweites Infoschreiben an die Bezirke, in den die weiteren Schritte erläutert und neu aufgetretene Fragen beantwortet wurden. Parallel hat das Projektteam die eingegangenen Hinweise systematisiert. Mit allen Bezirken wurde ein intensiver Austausch gesucht, um offene Punkte zu klären. Durch eine sehr konstruktive Zusammenarbeit aller Beteiligter, gerade auch während der erschwerten Arbeitsbedingungen aufgrund der Corona-Pandemie, konnten Lösungen für alle Änderungswünsche gefunden werden. Durch zahlreiche telefonische Abstimmungsgespräche und schriftlichen Austausch wurden letztlich alle offenen Punkte abgestimmt.

Auf Basis aller vorliegenden Hinweise und Änderungswünsche wurde ein neuer gesamtstädtischer Entwurf durch das Projektteam erstellt. Dieser wurde Anfang April 2020 an die Senatsfach- und Bezirksverwaltungen versandt. Die Bezirke wurden gebeten, diesen neuen Stand bis Ende April 2020 erneut zu prüfen, um sicherzustellen, dass die Hinweise bzw. die entstandenen Modifikationen richtig in den neuen Stand überführt wurden. Bis Anfang Mai 2020 lagen aus allen Bezirken Rückmeldungen vor. Nur noch in sehr wenigen Fällen wurden kleinere Korrekturen erbeten und/oder Nachmeldungen zu Namensänderungen einzelner LOR übermittelt.

In der Phase der **Finalisierung** wurde eine endgültige Fassung der Modifikationen erstellt. Die entsprechenden Resultate finden sich im Kapitel LOR-Systematik nach der Modifikation. Den Bezirken wurde ein drittes Infoschreiben Ende Mai 2020 übermittelt, in dem zum einen für den erfolgreichen Prozess gedankt wurde und zum anderen auf die Vereinheitlichung der LOR-Nummerierung eingegangen wurde. Zudem wurde auf die bevorstehende Senatsvorlage hingewiesen. Während bereits mehrere Bezirke einen Beschluss des jeweiligen Bezirksamts herbeigeführt hatten, stand der Senatsbeschluss aus.

Durch den **Senatsbeschluss** am 06.10.2020 und der Beteiligung des Rats der Bürgermeister (24.09.2020) erhielt die Modifikation die notwendige Legitimation, um zum 01.01.2021 eingeführt zu werden.

4.3 Datenbereitstellung

Die abgestimmte **Änderung der LOR wird zum 01.01.2021 gültig** und löst die bestehenden LOR vom 01.08.2006 ab. Zukünftige Daten werden vom Land Berlin auf dieser Basis veröffentlicht.

Das AfS strebt an, ausgewählte Daten zum Stichtag 31.12.2020 bzw. das Jahr 2020 für die alten und neuen Abgrenzungen zu veröffentlichen. In zukünftigen Jahren werden die Daten nur noch auf Grundlage der modifizierten LOR veröffentlicht.

Die **Vergleichbarkeit der Daten nach bisheriger und modifizierter LOR-Grundlage** sollte für einen Übergangszeitraum abgesichert werden. Dazu ist von Seiten des AfS eine **Rückrechnung von ausgewählten Daten,** z. B. aus der Einwohnerstatistik aus den vorherigen Jahren, geplant, die im Datenpool und im Statistischen Informationssystem Berlin-Brandenburg (*StatIS*-BBB) veröffentlicht werden soll. Ebenso wird den Fachverwaltungen auf der Senats- und Bezirksebene, die raumbezogene Fachdaten

in der LOR-Systematik verarbeiten und nutzen, eine Rückrechnung von eigenen Daten aus den letzten Jahren auf die neuen LOR-Geometrien empfohlen.

In der Analyse von Daten auf LOR-Ebene ist teils eine Differenzierung zwischen bewohnten und unbewohnten Räumen sinnvoll. Für entsprechende statistische Auswertungen mit einem Flächenbezug und für kartografische Darstellungen wird SenStadtWohn geeignete Arbeitshilfen bereitstellen (z. B. planungsraumbezogene Angaben zur Flächennutzung auf Basis des Umweltatlas, grafische Darstellung unbewohnter Bereiche als „Decker“).

5 LOR-Systematik vor der Modifikation

Die LOR-Systematik ist ein hierarchisch gegliedertes System. Das heißt, einem Prognoseraum werden mehrere Bezirksregionen und einer Bezirksregion mehrere Planungsräume zugeordnet. Gesamtstädtisch kam es zu wenigen Ausnahmen. In einigen Bezirken wurde einzelnen Bezirksregionen nur je ein Planungsraum zugeordnet (etwa in Pankow, Charlottenburg-Wilmersdorf und in Lichtenberg). Im Bezirk Tempelhof-Schönberg waren bis zur Modifikation der LOR die Ebene der Prognoseräume und der Bezirksregionen deckungs- und namensgleich.

Mit einer Änderung zum 01.01.2019 im Bezirk Treptow-Köpenick/Allende-Viertel erfuhr die im Jahr 2006 eigeführte Systematik der Lebensweltich orientierten Räume ihre erste kleine Änderung. Die seit 2019 geltende Gliederung dient nachfolgend und im Rest dieser Dokumentation als „Ausgangslage“, die auch als „LOR-Systematik 2019“ beschrieben wird. Die LOR-Systematik nach der Modifikation wird folglich als „LOR-Systematik 2021“ bezeichnet, da sie ab dann zum Einsatz kommen soll.

Tabelle 1 zeigt, wie sich die LOR-Systematik mit der Einführung im Jahr 2006 bzw. mit Stand 2019 darstellt. Es gab bisher 60 Prognoseräume (PGR), 138 Bezirksregionen (BZR) und 448 Planungsräume (PLR). Mit der Einführung im Jahr 2006 waren es 447 PLR.

Abbildung 5 zeigt auf der Karte, wie sich die Gliederung in Berlin mit Stand 2019 darstellt. Die nachfolgenden Kapitel beschreiben jeweils knapp die drei Ebenen der LOR.

Tabelle 1: Übersicht über die LOR-Systematik vor der Modifikation

Merkmal	LOR-Systematik 2006	LOR-Systematik 2019
Anzahl der PGR	60	60
Anzahl der BZR	138	138
Anzahl der PLR	447	448

Quelle: eigene Zusammenstellung

statistik Berlin | Senatsverwaltung für Stadtentwicklung | berlin

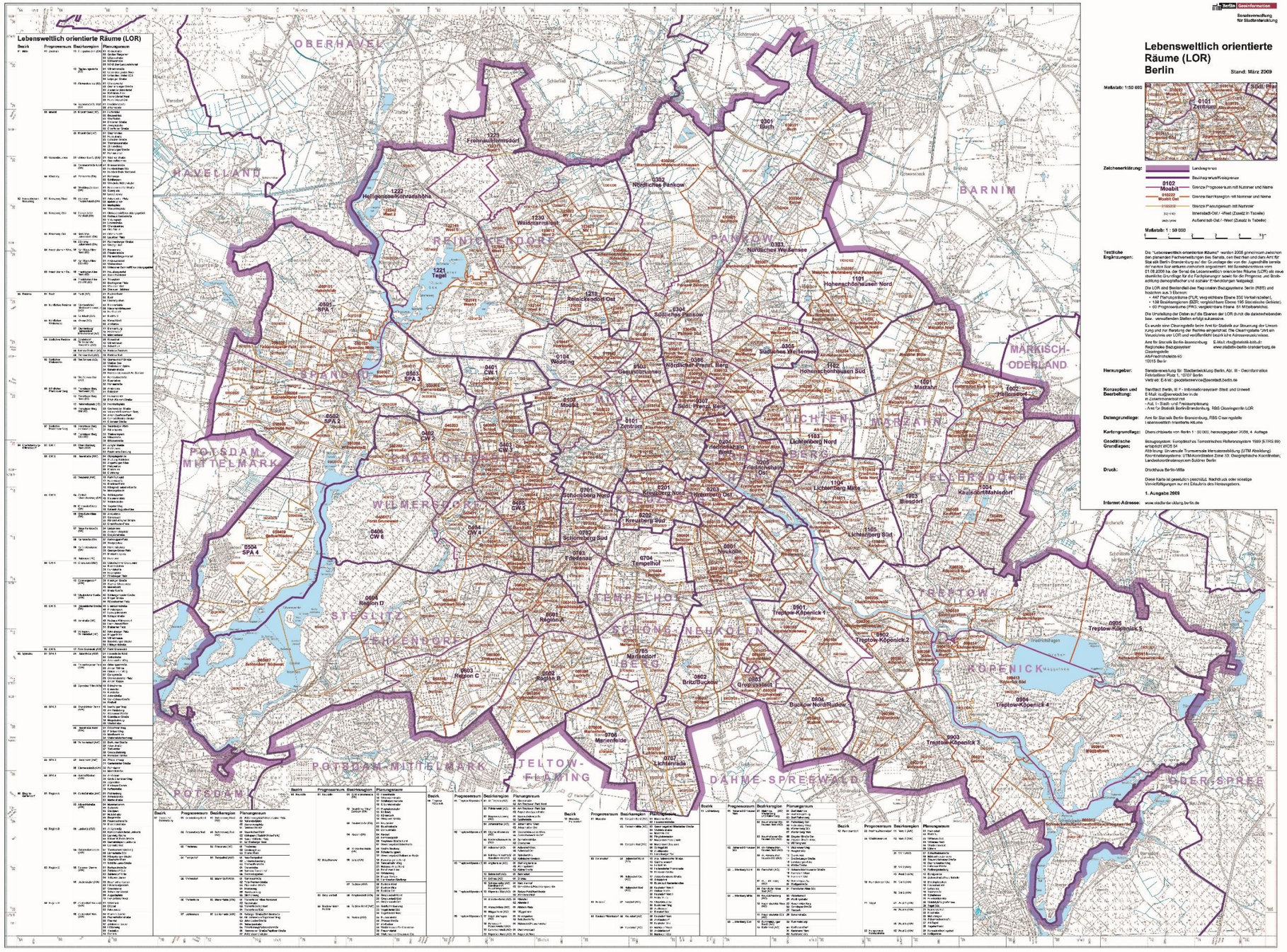
Lebensweltlich orientierte Räume (LOR)
Berlin
Stand: März 2009
Maßstab: 1:50 000
Zeichenerklärung:
Textliche Ergänzungen:
Herausgeber:
Konzeption und Bearbeitung:
Datengrundlage:
Kartengrundlage:
Geodätische Grundlagen:
Druck:
Internet-Adresse:
1. Ausgabe 2009
OBERHAVEL
HAVELLAND
BARNIM
MÄRKISCH-ODERLAND
POTSDAM-MITTELMARK
TELTOW-FLÄMING
DAHME-SPREEWALD
ODER-SPREE
POTSDAM
REINICKENDORF
PANKOW
SPANDAU
MITTE
CHARLOTTENBURG-WILMERSDORF
MARZAHN-HELLERSDORF
LICHTENBERG
TEMPELHOF-SCHÖNEBERG
STEGLITZ-ZEHLENDORF
NEUKÖLLN
TREPTOW-KÖPENICK
Frohnau/Hermsdorf
Hellersdorf-Nord/Marzahn-Nord
Weißensee
Prenzlauer Berg
Hohenschönhausen Nord
Hohenschönhausen Süd
Marzahn
Hellersdorf
Lichtenberg Nord
Lichtenberg Mitte
Lichtenberg Süd
Biesdorf
Kaulsdorf/Mahlsdorf
Treptow-Köpenick 1
Treptow-Köpenick 2
Treptow-Köpenick 3
Treptow-Köpenick 4
Treptow-Köpenick 5
Britz/Buckow
Buckow Nord/Rudow
Grünau/Müggelheim
Altglienicke
Adlershof
Bohnsdorf
Schöneweide
Alt-Treptow
Plänterwald
Baumschulenweg
Johannisthal/Adlershof
Müggelheim
Köpenick
Friedrichshagen
Rahnsdorf/Müggelsee
Grünau
Mahlsdorf
Gesundbrunnen
Mitte
Moabit
Hansaviertel
Tiergarten
Wedding
Prenzlauer Berg
Friedrichshain
Kreuzberg
Charlottenburg
Wilmersdorf
Spandau
Steglitz
Zehlendorf
Schöneberg
Tempelhof
Neukölln
Tempelhof
Marienfelde
Lichtenrade
Lankwitz
Lichterfelde
Nikolassee
Wannsee
Zehlendorf-Süd
Steglitz
Lichterfelde-Ost
Lichterfelde-West
Dahlem
Grunewald
Charlottenburg-Nord
Charlottenburg
Westend
Wilmersdorf
Schmargendorf
Spandau
Hakenfelde
Siemensstadt
Gatow/Kladow
Staaken
Wilhelmstadt
Haselhorst
Moabit
Tiergarten
Mitte
Wedding
Prenzlauer Berg
Friedrichshain
Kreuzberg
Neukölln
Tempelhof
Schöneberg
Steglitz
Zehlendorf
Charlottenburg
Wilmersdorf
Spandau
Reinickendorf
Pankow
Weißensee
Hohenschönhausen
Lichtenberg
Marzahn
Hellersdorf
Treptow
Köpenick

5.1 Prognoseräume (PGR)

Berlin besaß vor der Modifikation 60 Prognoseräume (PGR) mit durchschnittlich etwa 63.000 Einwohnerinnen und Einwohnern (siehe Tabelle 2). Sie stellen nach den zwölf Bezirken die nächst kleinere Planungseinheit dar und sind die „oberste“ Ebene der Lebensweltlich orientierten Räume. Sie werden primär als Grundlage für die teilräumliche Bevölkerungsprognose genutzt.

Die Anzahl der Prognoseräume betrug je Bezirk zwischen vier und sieben Prognoseräumen. Die Anzahl der Prognoseräume ist unabhängig von der Einwohnerzahl in den Bezirken. So wies neben dem einwohnerstärksten Bezirk Pankow (409.335 EW) nur Tempelhof-Schöneberg (350.984 EW) sieben Prognoseräume auf. Der ebenfalls in Bezug auf die Einwohnerzahl große Bezirk Mitte wies bisher beispielsweise nur vier Prognoseräume auf.

Die Einwohnerspanne der Prognoseräume ist groß und reicht von unter 100 (PGR 0406, CW6, Bezirk Charlottenburg-Wilmersdorf) bis über 166.000 (PGR 0801, Neukölln, Bezirk Neukölln).

Tabelle 2: Übersicht über die Prognoseräume nach Berliner Bezirken, vor der Modifikation

Bezirk	LOR-Systematik 2019				
	EW 31.12.2019	Anzahl PGR	EW-Durchschnitt PGR	EW-Minimum PGR	EW-Maximum PGR
01 Mitte	385.748	4	96.437	78.278	117.450
02 Friedrichshain-Kreuzberg	290.386	5	58.077	40.530	85.819
03 Pankow	409.335	7	58.476	17.094	104.046
04 Charlottenburg-Wilmersdorf	343.592	6	57.265	68	146.437
05 Spandau	245.197	4	61.299	19.945	105.978
06 Steglitz-Zehlendorf	310.092	4	77.523	70.163	84.718
07 Tempelhof-Schöneberg	350.984	7	50.141	32.337	65.094
08 Neukölln	329.902	4	82.476	37.507	166.157
09 Treptow-Köpenick	273.220	5	54.644	37.570	66.931
10 Marzahn-Hellersdorf	270.116	4	67.529	28.063	111.021
11 Lichtenberg	294.201	5	58.840	32.248	75.832
12 Reinickendorf	266.408	5	53.282	24.104	97.734
Berlin	**3.769.181**	**60**	**62.820**	**68**	**166.157**

Quelle: eigene Zusammenstellung; Daten: AfS

5.2 Bezirksregionen (BZR)

In den zwölf Berliner Bezirken gab es entsprechend der LOR-Systematik aus dem Jahr 2019 138 Bezirksregionen (BZR, siehe Tabelle 3). Sie dienen zahlreichen bezirklichen Analysen als räumliche Bezugsebene (etwa in den Bezirksregionen-Profilen).

Zwischen den Bezirken variierten die Anzahl und auch die Einwohnerzahl in den Bezirksregionen deutlich. Die Bezirke Pankow (16 BZR), Charlottenburg-Wilmersdorf (17 BZR) und Treptow-Köpenick (20 BZR) wiesen die größte Anzahl an Bezirksregionen auf. Die geringste Anzahl hatten die Bezirke Friedrichshain-Kreuzberg (8), Steglitz-Zehlendorf (8), und Tempelhof-Schöneberg (7).

Durchschnittlich lebten am 31.12.2019 über 27.000 Einwohnerinnen und Einwohner in einer Bezirksregion. Die EW-reichste BZR ist die BZR 020202 (Tempelhofer Vorstadt, Bezirk Friedrichshain-Kreuzberg). Die wenigsten Einwohnerinnen und Einwohner lebten in der BZR 040617 (Forst Grunewald, Bezirk Charlottenburg-Wilmersdorf).

Tabelle 3: Übersicht über die Bezirksregionen nach Berliner Bezirken, vor der Modifikation

Bezirk	LOR-Systematik 2019				
	EW 31.12.2019	Anzahl BZR	EW-Durchschnitt BZR	EW-Minimum BZR	EW-Maximum BZR
01 Mitte	385.748	10	38.575	12.742	57.883
02 Friedrichshain-Kreuzberg	290.386	8	36.298	21.989	65.647
03 Pankow	409.335	16	25.583	15.504	38.528
04 Charlottenburg-Wilmersdorf	343.592	17	20.211	68	35.299
05 Spandau	245.197	9	27.244	12.831	42.031
06 Steglitz-Zehlendorf	310.092	8	38.762	22.221	53.582
07 Tempelhof-Schöneberg	350.984	7	50.141	32.337	65.094
08 Neukölln	329.902	10	32.990	9.653	43.926
09 Treptow-Köpenick	273.220	20	13.661	4.424	27.925
10 Marzahn-Hellersdorf	270.116	9	30.013	19.408	48.008
11 Lichtenberg	294.201	13	22.631	4.254	34.074
12 Reinickendorf	266.408	11	24.219	9.274	40.379
Berlin	**3.769.181**	**138**	**27.313**	**68**	**65.647**

Quelle: eigene Zusammenstellung; Daten: AfS

5.3 Planungsräume (PLR)

Die LOR Systematik 2019 enthielt 448 Planungsräume (PLR, siehe Tabelle 4). Die Planungsräume dienen vor allem gesamtstädtischen Monitorings, etwa zur Entwicklung des Wohnungsmarkts, zur Umweltgerechtigkeit und zur sozialen Stadtentwicklung.

Die Anzahl PLR je Bezirk variierte zwischen 26, im Bezirk Friedrichshain-Kreuzberg und 57 im Bezirk Charlottenburg-Wilmersdorf. Berlinweit betrachtet lebten am 31.12.2019 rund 8.400 Einwohnerinnen und Einwohner in einem Planungsraum. Im Minimum waren es neun im PLR 04020314 (Messegelände, Bezirk Charlottenburg-Wilmersdorf). Im PLR 03040614 (Pankow-Zentrum, Bezirk Pankow) fand sich der Höchstwert von knapp über 37.000 Einwohnerinnen und Einwohner.

Tabelle 4: Übersicht über die Planungsräume nach Berliner Bezirken, vor der Modifikation

Bezirk	LOR-Systematik 2019				
	EW 31.12.2018	Anzahl PLR	EW-Durchschnitt PLR	EW-Minimum PLR	EW-Maximum PLR
01 Mitte	385.748	41	9.408	188	26.956
02 Friedrichshain-Kreuzberg	290.386	26	11.169	1.160	21.899
03 Pankow	409.335	40	10.233	229	37.024
04 Charlottenburg-Wilmersdorf	343.592	57	6.028	9	15.756
05 Spandau	245.197	39	6.287	457	18.244
06 Steglitz-Zehlendorf	310.092	41	7.563	3.148	13.784
07 Tempelhof-Schöneberg	350.984	34	10.323	2.254	24.771
08 Neukölln	329.902	40	8.248	478	27.602
09 Treptow-Köpenick	273.220	35	7.806	68	17.021
10 Marzahn-Hellersdorf	270.116	33	8.185	1.308	18.471
11 Lichtenberg	294.201	32	9.194	644	29.596
12 Reinickendorf	266.408	30	8.880	269	18.100
Berlin	**3.769.181**	**448**	**8.413**	**9**	**37.024**

Quelle: eigene Zusammenstellung; Daten: AfS

6 LOR-Systematik nach der Modifikation

6.1 Gesamtstädtischer Überblick

Durch die Modifikation der Lebensweltlich orientierten Räume gab es zahlreiche Änderungen, vor allem auf der Ebene der Planungsräume (PLR). Durch das:

- **Zusammenlegen von PLR mit wenigen Einwohnerinnen und Einwohnern mit angrenzenden PLR**
- **Teilen sehr einwohnerreicher PLR in zwei oder mehr PLR**
- **Hinzufügen neuer PLR zur Abgrenzung neuer Stadtquartiere**

waren 162 Planungsräume der LOR-Systematik 2019 von Änderungen betroffen. Im Ergebnis wuchs die Zahl der PLR von 448 auf 542 an (siehe Tabelle 5). Die durchschnittliche Einwohnerzahl sank entsprechend von über 8.400 auf unter 7.000.

Mehrere Bezirke haben auch auf der Ebene der Bezirksregionen Anpassungen vorgenommen, um die Homogenität der LOR zu erhöhen. Während etwa der Bezirk Charlottenburg-Wilmersdorf die Anzahl reduzierte, erhöhte der Bezirk Tempelhof-Schöneberg im Zuge der Modifikationen die Anzahl, um die im Bezirk bislang nicht bestehende Differenzierung zwischen Bezirksregionen und Prognoseräumen umzusetzen. Berlinweit gibt es mit der LOR-Systematik ab 2021 143 BZR, statt bisher 138. Die mittlere Einwohnerzahl sank leicht, um circa 1.000 Personen auf nun etwas über 26.000.

Nur wenige Bezirke haben die Prognoseräume verändert. Im Ergebnis sank die Zahl der PGR in der Systematik ab 2021 um zwei auf nun 58. Die durchschnittliche Einwohnerzahl stieg daher auf knapp 65.000 EW.

Tabelle 5: Gesamtstadt - Übersicht zu LOR-Ebenen vor und nach der Modifikation

Merkmal	LOR-Systematik 2019	LOR-Systematik ab 2021
Anzahl der PGR	60	58
Durchschnittliche Einwohnerzahl PGR	62.820	64.986
Anzahl der BZR	138	143
Durchschnittliche Einwohnerzahl BZR	27.313	26.358
Anzahl der PLR	448	542
Durchschnittliche Einwohnerzahl PLR	8.413	6.967

Quelle: eigene Zusammenstellung; Daten: AfS

6.1.1 Prognoseräume nach der Modifikation

Die neue Verteilung der Prognoseräume nach Größenklasse zeigt Abbildung 6. Durch die nur leichten Änderungen ergeben sich für die LOR-Systematik ab 2021 kaum Veränderungen. Vor allem der EW-schwächste PGR (PGR 0310, Buch, Bezirk Pankow) ist nun aber mit über 17.000 EW deutlich „größer“ als zuvor der kleinste PGR (siehe Kapitel Prognoseräume (PGR)). Der größte Prognoseraum ist auch

weiterhin mit über 166.000 Einwohnerinnen und Einwohnern der PGR 0810, Neukölln im Bezirk Neukölln.[4]

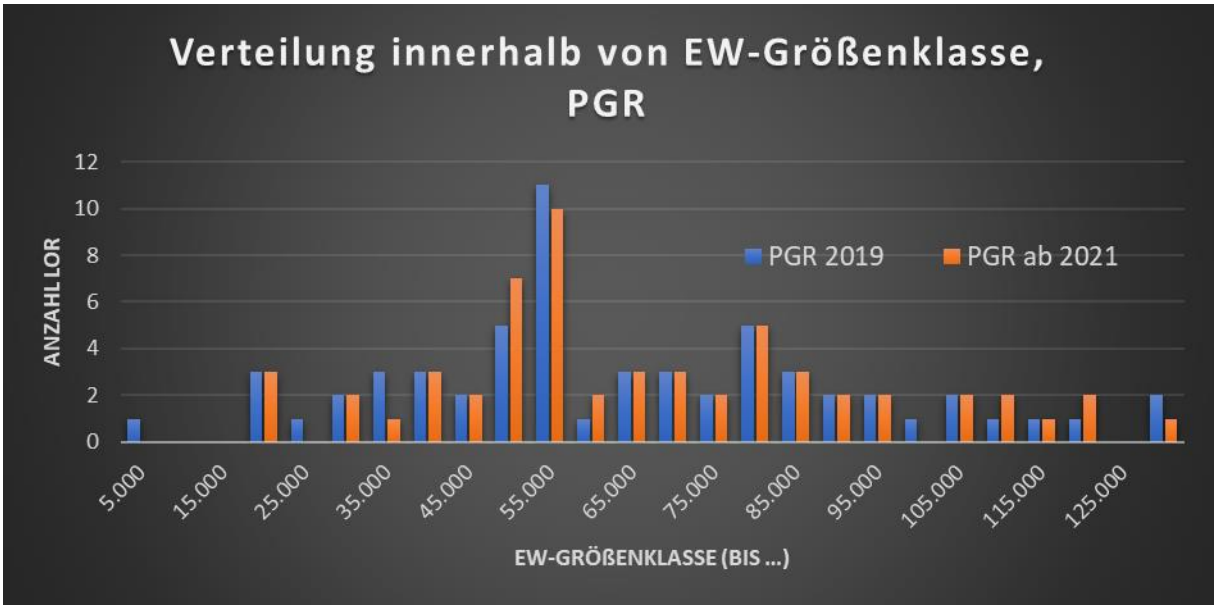

Abbildung 6: Veränderung der Verteilung innerhalb der EW-Größenklassen, PGR

Quelle: eigene Darstellung, Daten: AfS

Tabelle 6 fasst ausgewählte Merkmale der Prognoseräume für alle Bezirke nach der Modifikation zusammen. Vier bis sieben PGR weist jeder der zwölf Bezirke auf. Berlinweit liegt der EW-Durchschnitt bei ca. 65.000 Personen.

Tabelle 6: Übersicht über die Prognoseräume nach Berliner Bezirken, nach der Modifikation

Bezirk	LOR-Systematik ab 2021				
	EW 31.12.2019	Anzahl PGR	EW-Durchschnitt PGR	EW-Minimum PGR	EW-Maximum PGR
01 Mitte	385.748	4	96.437	78.278	117.450
02 Friedrichshain-Kreuzberg	290.386	5	58.077	40.530	85.819
03 Pankow	409.335	7	58.476	17.094	104.046
04 Charlottenburg-Wilmersdorf	343.592	5	68.718	19579	119.359
05 Spandau	245.197	4	61.299	19.945	106.631
06 Steglitz-Zehlendorf	310.092	4	77.523	70.163	84.718
07 Tempelhof-Schöneberg	350.984	6	58.497	46.428	84.292
08 Neukölln	329.902	4	82.476	37.507	166.157
09 Treptow-Köpenick	273.220	5	54.644	37.570	66.931
10 Marzahn-Hellersdorf	270.116	4	67.529	28.063	111.021
11 Lichtenberg	294.201	5	58.840	32.248	75.832
12 Reinickendorf	266.408	5	53.282	48.081	57.794
Berlin	**3.769.181**	**58**	**64.986**	**17.094**	**166.157**

Quelle: eigene Zusammenstellung; Daten: AfS

6.1.2 Bezirksregionen nach der Modifikation

Mit der Modifikation der Bezirksregionen wurden durch Teilung und Zusammenlegung die Anzahl je Bezirk und die Größe im Hinblick auf die Einwohnerzahl berlinweit angeglichen. Dies veranschaulicht

[4] Die Nummerierung der LOR wurde im Zuge der Modifikationen angepasst. Die neue Nummerierungssystematik wird im Kapitel Neue LOR-Nummerierung vorgestellt.

Abbildung 7. Mehr BZR als zuvor konzentrieren sich im Bereich der mittleren Einwohnerzahl von 26.400 (siehe Tabelle 5). Die geringste EW-Zahl in einer BZR der LOR-Systematik ab 2021 weist nun die BZR 115012, Rummelsburger Bucht im Bezirk Lichtenberg mit rund 4.300 Einwohnern und Einwohnerinnen auf. Die höchste EW-Zahl (65.600) entfällt weiterhin auf die BZR 022002, Tempelhofer Vorstadt im Bezirk Friedrichshain-Kreuzberg.

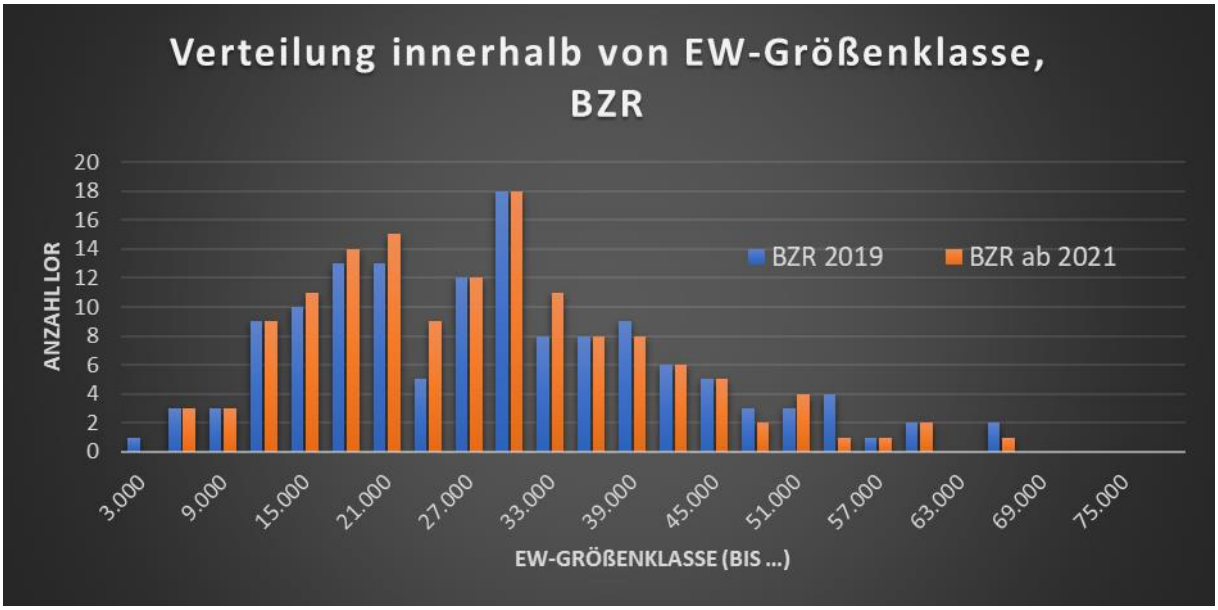

Abbildung 7: Veränderung der Verteilung innerhalb der EW-Größenklassen, BZR

Quelle: eigene Darstellung, Daten: AfS

Tabelle 7 fasst ausgewählte Merkmale der Bezirksregionen für alle Bezirke nach der Modifikation zusammen. Die Bezirke besitzen zwischen acht und 20 BZR. Berlinweit liegt der EW-Durchschnitt bei ca. 26.000 Personen.

Tabelle 7: Übersicht über die Bezirksregionen nach Berliner Bezirken, nach der Modifikation

Bezirk	LOR-Systematik ab 2021				
	EW 31.12.2019	Anzahl BZR	EW-Durch-schnitt BZR	EW-Minimum BZR	EW-Maximum BZR
01 Mitte	385.748	10	38.575	12.742	57.883
02 Friedrichshain-Kreuzberg	290.386	8	36.298	20.791	65.647
03 Pankow	409.335	16	25.583	15.504	38.528
04 Charlottenburg-Wilmersdorf	343.592	11	31.236	13212	50.242
05 Spandau	245.197	9	27.244	12.831	42.031
06 Steglitz-Zehlendorf	310.092	8	38.762	22.221	53.582
07 Tempelhof-Schöneberg	350.984	15	23.399	14.506	32.108
08 Neukölln	329.902	12	27.492	9.653	43.926
09 Treptow-Köpenick	273.220	20	13.661	4.424	27.914
10 Marzahn-Hellersdorf	270.116	9	30.013	19.408	48.008
11 Lichtenberg	294.201	13	22.631	4.254	34.074
12 Reinickendorf	266.408	12	22.201	9.274	33.421
Berlin	**3.769.181**	**143**	**26.358**	**4.254**	**65.647**

Quelle: eigene Zusammenstellung; Daten: AfS

6.1.3 Planungsräume nach der Modifikation

Die deutlichen Modifikationen der PLR zeigen sich auch in der Verteilung innerhalb der EW-Größenklassen. Abbildung 8 verdeutlicht, dass das übergeordnete Ziel, die Reduktion der Einwohnerspanne,

erreicht wurde. Mit der LOR-Systematik ab 2021 gibt es nun deutlich weniger „Ausreißer“, die sehr hohe EW-Zahlen aufweisen. Insgesamt bündelt sich ein Großteil der PLR nun um den EW-Durchschnitt von 7.000 Personen. Die Vergleichbarkeit der PLR für zukünftige Analysen wurde damit deutlich gesteigert.

Zunächst gibt es weiterhin mehrere PLR mit weniger als 1.000 Einwohnerinnen und Einwohnern, etwa PLR 03400831 (Pankower Tor, Bezirk Pankow) und PLR 06200419 (Landweg, Bezirk Steglitz-Zehlendorf). Dies sind Fälle, in denen städtebauliche Entwicklungen (neue Stadtquartiere) absehbar sind. Es war gerade Ziel der Modifikationen, diese Gebiete bereits jetzt abzugrenzen, um zeitnahe erneute Modifikationen zu vermeiden und der LOR-Systematik die nötige Stabilität zu verleihen.

Die meisten Einwohner und Einwohnerinnen weist in der LOR-Systematik ab2021 der neu entstandene PLR 11400929, Weitlingkiez im Bezirk Lichtenberg, auf. Mit knapp über 16.000 EW ist er einer von nur zwei PLR, die über dem avisierten Maximum liegen. Die sozialräumliche Homogenität hat den Ausschlag gegeben, das quantitative Kriterium hintan zu stellen. Der nun größte PLR besitzt damit jedoch noch immer deutlich weniger Einwohnerinnen und Einwohnern als der vormals größte PLR vor der Modifikation (siehe Planungsräume (PLR)).

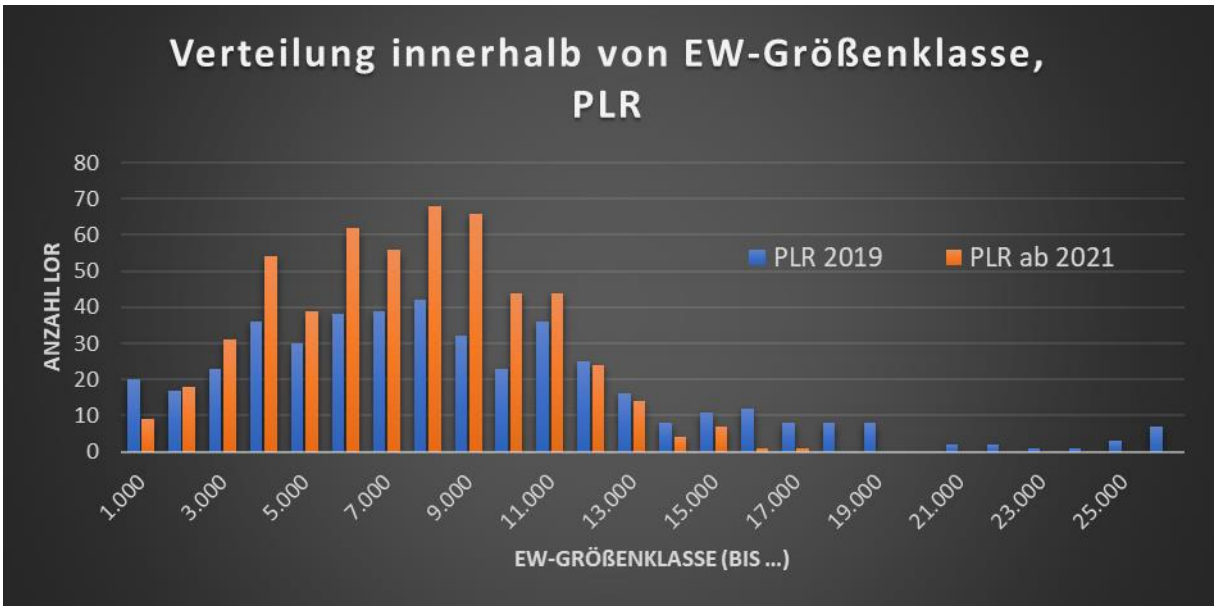

Abbildung 8: Veränderung der Verteilung innerhalb der EW-Größenklassen, PLR
Quelle: eigene Darstellung; Daten: AfS

Tabelle 8 fasst ausgewählte Merkmale der Planungsräume für alle Bezirke nach der Modifikation zusammen. Die Bezirke besitzen zwischen 36 und 60 PLR. Berlinweit liegt der EW-Durchschnitt bei ca. 7.000 Personen.

Tabelle 8: Übersicht über die Planungsräume nach Berliner Bezirken, nach der Modifikation

Bezirk	LOR-Systematik ab 2021				
	EW 31.12.2018	Anzahl PLR	EW-Durch-schnitt PLR	EW-Minimum PLR	EW-Maximum PLR
01 Mitte	385.748	49	7.872	1.755	14.657
02 Friedrichshain-Kreuzberg	290.386	36	8.066	1.160	15.140
03 Pankow	409.335	60	6.938	42	12.868
04 Charlottenburg-Wilmersdorf	343.592	53	6.483	106	12.434
05 Spandau	245.197	45	5.449	27	11.954
06 Steglitz-Zehlendorf	310.092	44	7.048	21	13.784
07 Tempelhof-Schöneberg	350.984	48	7.312	443	12.248
08 Neukölln	329.902	46	7.172	1.247	12.546
09 Treptow-Köpenick	273.220	43	6.354	1.567	14.553
10 Marzahn-Hellersdorf	270.116	41	6.588	1.308	14.605
11 Lichtenberg	294.201	41	7.176	1.870	16.172
12 Reinickendorf	266.408	36	7.400	360	14.827
Berlin	**3.769.181**	**542**	**6.967**	**21**	**16.172**

Quelle: eigene Zusammenstellung; Daten: AfS

Abbildung 9 zeigt berlinweit die vollständige LOR-Systematik ab 2021. Details zu den zwölf Bezirken und jeweils zu den drei LOR-Ebenen können den nachfolgenden Kapiteln entnommen werden. Eine vollständige Liste mit Namen und LOR-Nummerierung findet sich im Anhang.

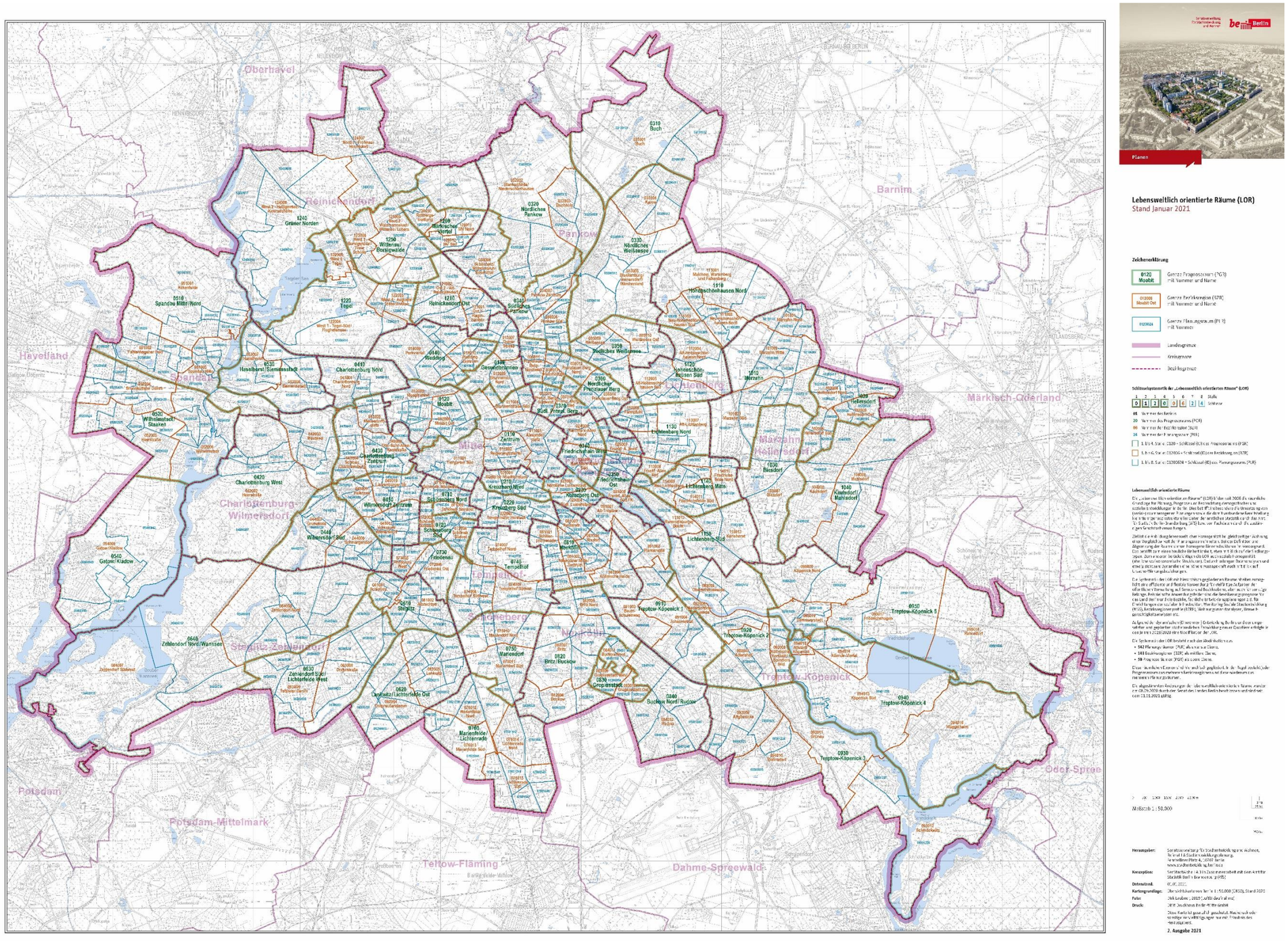

Lebensweltlich orientierte Räume (LOR)
Stand Januar 2021

Zeichenerklärung

0120 Moabit — Grenze Prognosraum (PGR) mit Nummer und Name

012008 Moabit Ost — Grenze Bereich (BR) mit Nummer und Name

0120624 — Grenze Planungsraum (PLR) mit Nummer

Landesgrenze

Kreisgrenze

Bezirksgrenze

Schlüsselsystematik der „Lebensweltlich orientierten Räume" (LOR)

1	2	3	4	5	6	7	8	Stelle
0	1	2	0	0	6	2	4	Schlüssel

01 Nummer des Bereichs
20 Nummer des Prognosraumes (PGR)
06 Nummer des Bereichs (BR)
24 Nummer des Planungsraumes (PLR)

L.B.R.P.: Stelle 1-8: 0120 - Schlüssel (ID) des Prognosraumes (PGR)

L.B.R.B.: Stelle 1-8: 012006 - Schlüssel (ID) des Bereiches (BR)

L.B.R.B.: Stelle 1-8: 0120624 - Schlüssel (ID) des Planungsraumes (PLR)

Lebensweltlich orientierte Räume

Die „Lebensweltlich orientierten Räume" (LOR) bilden seit 2006 die räumliche Grundlage für Planung, Programmsteuerung, Berichterstattung, sozialraumorientierte sozialen Entwicklungen in der Stadt. Über Stadtteilgrenzen hinweg sind die Bereiche und Planungsräume so angelegt, dass die dort lebenden Menschen in einer für sie überschaubaren Nachbarschaft leben können und eine Zuordnung zu einem Ortsteil oder Bezirk nicht erforderlich ist. Die LOR sollen zudem die Grundlage für die Verwaltung, Planung und Berichterstattung der Bezirke bilden. Die Bezirke haben jedoch die Möglichkeit, eigene Sozialraumorientierungen zu definieren.

Zielsetzung ist eine bezirksübergreifend einheitliche Grundstruktur gleichzeitiger Abbildung einer Vergleichbarkeit der Stadtteile. Für eine aussagekräftige Analyse, Bewertung und Abgrenzung der Bereiche wurde homogene Bevölkerungsstrukturen zusammengeführt. Das bedeutet eine möglichst hohe Homogenität innerhalb der Bereiche und eine Heterogenität zwischen den Bereichen. Zudem wurde bei der Abgrenzung der LOR auch auf die Homogenität der Bebauungsstruktur und der städtebaulichen Struktur geachtet. Entsprechend wurde versucht, eine Abgrenzung der Bereiche an einer homogenen Bebauungsstruktur und an städtebaulichen Gegebenheiten vorzunehmen.

Das Systemmodell der LOR mit drei Ebenen wurde gegenüber dem Vorjahr mit einer Verfeinerung der Differenzierung der Planungsräume (PLR) vorgenommen. Die Bezirksgrenzen sind unverändert geblieben. Die Bezirksgrenzen sind unverändert geblieben. Die Bezirksgrenzen sind unverändert geblieben

6.2 Neue LOR-Nummerierung

In einem weiteren Schritt erhielten die neu abgegrenzten LOR eine neue Nummerierung. In den einzelnen Bezirken war die Systematik der Nummerierung mitunter sehr heterogen (Nutzung hierarchischer, fortlaufender und freier Nummerierungen in verschiedener Kombination). Vor und nach der Modifikation gilt, dass die LOR-Nummern aus acht Ziffern bestehen, von denen die ersten beiden Ziffern den Bezirk angeben und die nachfolgenden je zwei Ziffern den Prognoseraum, die Bezirksregion und den Planungsraum.

Als Grundsatz sollten bei der Nummerierung der neu zugeschnittenen LOR-Räume keine bisher genutzten Nummern vergeben werden, um eine Verwechslung und mögliche Nutzung von Daten für eine andere räumliche Einheit auszuschließen. Zudem sollte im Zuge der Änderung die Nomenklatur soweit wie möglich berlinweit vereinheitlicht werden, um das System insgesamt möglichst nachvollziehbar zu gestalten. Weitere Faktoren, die in die Betrachtung der Neugestaltung eingeflossen sind, wurden von verschiedenen Akteuren als Rückmeldung in den Modifikations-Prozess eingebracht:

- **Die Zeichenanzahl mit acht Nummern sollte beibehalten werden, damit bestehende Datenbanken und Verarbeitungsprozesse nicht angepasst werden müssen.**
- **In die Nummern sollten keine Buchstaben eingebunden werden, da es zu Problemen in Datenbankverarbeitungsprozessen bei alphanumerischen Daten kommen kann.**
- **Die durch Zusammenlegungen wegfallenden LOR sollten möglichst nicht für Lücken in der Reihenfolge sorgen.**
- **Aufeinanderfolgende Nummern sollten möglichst räumlich nebeneinander liegen.**

Alternative Lösungen, z. B. die vorhandenen Nummern beizubehalten und bei Änderung die nächsthöhere freie Nummer zu vergeben (Lücken in der Aufzählung) oder die Zeichenlänge auf neun oder zehn Zeichen zu erhöhen (Anpassung bestehender Datenbanken), wurden verworfen, weil sie mit zu vielen Nachteilen und Unwägbarkeiten verbunden wären. Im Zuge einer Abwägung von Vor- und Nachteilen wurde die folgend beschriebene Variante ausgewählt.

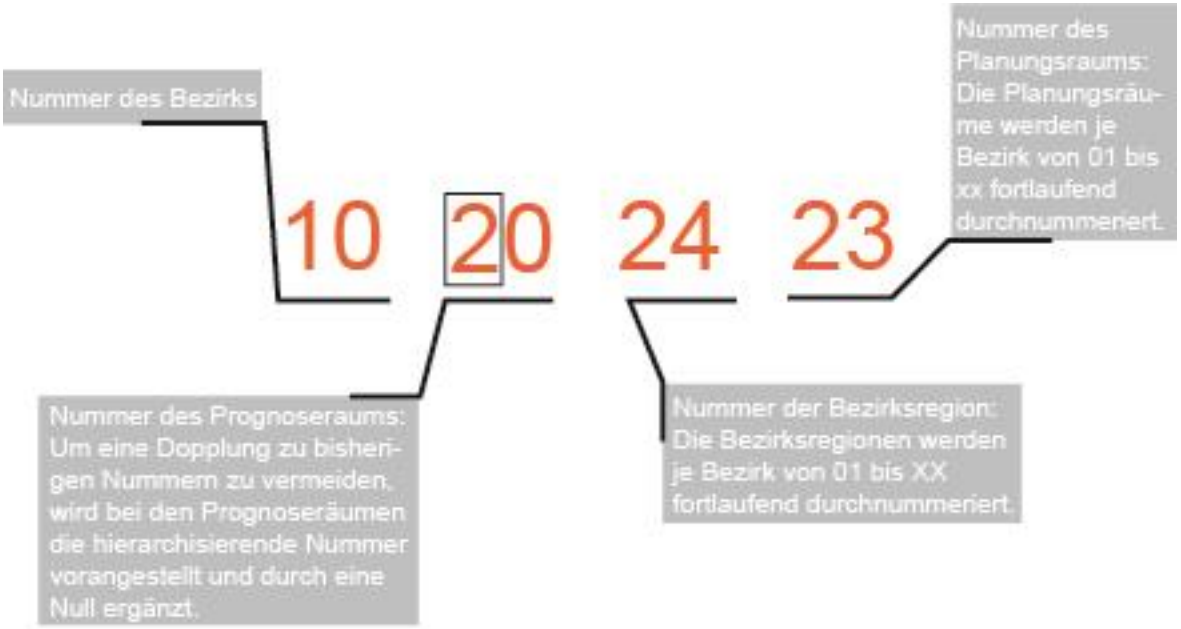

Abbildung 10: Neue Nummerierungssystematik der LOR ab 2021

Quelle: SenStadtWohn

Die Nummer zur Identifikation des Prognoseraums wird auf die erste Stelle der zwei Ziffern des Prognoseraums gesetzt, die zweite Ziffer ist die Null (Prognoseraum: 10, 20, 30 etc.). Dies wird möglich, da die Prognoseräume in jedem Bezirk hierarchisch strukturiert sind und in keinem Bezirk mehr als zehn Prognoseräume vorhanden sind.[5] Mit dem Ziel, die Methodik der Nummerierung gesamtstädtisch anzupassen und zu vereinheitlichen, werden die Bezirksregionen und die Planungsräume nach Bezirk jeweils von 01 bis XX fortlaufend nummeriert. Dieses System wurde schon bisher in den meisten Bezirken angewendet. Aus Sicht des Bezirks kann mit einer Doppelziffer Bezug auf eine Bezirksregion oder einen Planungsraum genommen werden und komplexe Nennungen von vier oder gar sechs Zahlen (Prognoseraum + Bezirksregion, Bezirksregion + Planungsraum, Prognoseraum + Bezirksregion + Planungsraum) sind nicht notwendig. Eine vollständige Liste mit der neuen LOR-Nummerierung findet sich im Anhang.

6.3 LOR-Systematik in den Bezirken

In den nachfolgenden Kapiteln werden die Ergebnisse der Modifikation je Bezirk vorgestellt. Neben einem Überblick gibt es je LOR-Ebene Hinweise zu wesentlichen Änderungen sowie tabellarische und kartografische Zusammenfassungen. Ein detaillierter Überblick zu allen LOR-Namen und LOR-Nummern findet sich im Anhang.

6.3.1 Bezirk Mitte

Überblick

Im Bezirk Mitte gab es zahlreiche Modifikationen auf Ebene der Planungsräume. Durch Teilung und Zusammenlegung wurde für alle PLR die anvisierte Mindest- und Maximalgröße, bzgl. der Zahl der Einwohnerinnen und Einwohner, erreicht. Die Ebenen der Bezirksregionen und Prognoseräume wurden nicht modifiziert.

Die folgende Abbildung 11 zeigt den neuen Zuschnitt der LOR in Mitte.

[5] Im Bezirk Reinickendorf gab es schon bisher den Prognoseraum 1230. Da der Zuschnitt dieses Prognoseraums aber verändert wurde, wird die 1230 in der neuen LOR-Systematik ab 2021 ausnahmsweise übersprungen. Die Nummer des Prognoseraums 1210 existierte ebenso schon in der LOR-Systematik 2019. Da jedoch der Prognoseraum keine Änderung erfahren hat, wird diese Nummer dem gleichen Raum erneut zugewiesen.

Abbildung 11: LOR in Mitte ab 2021

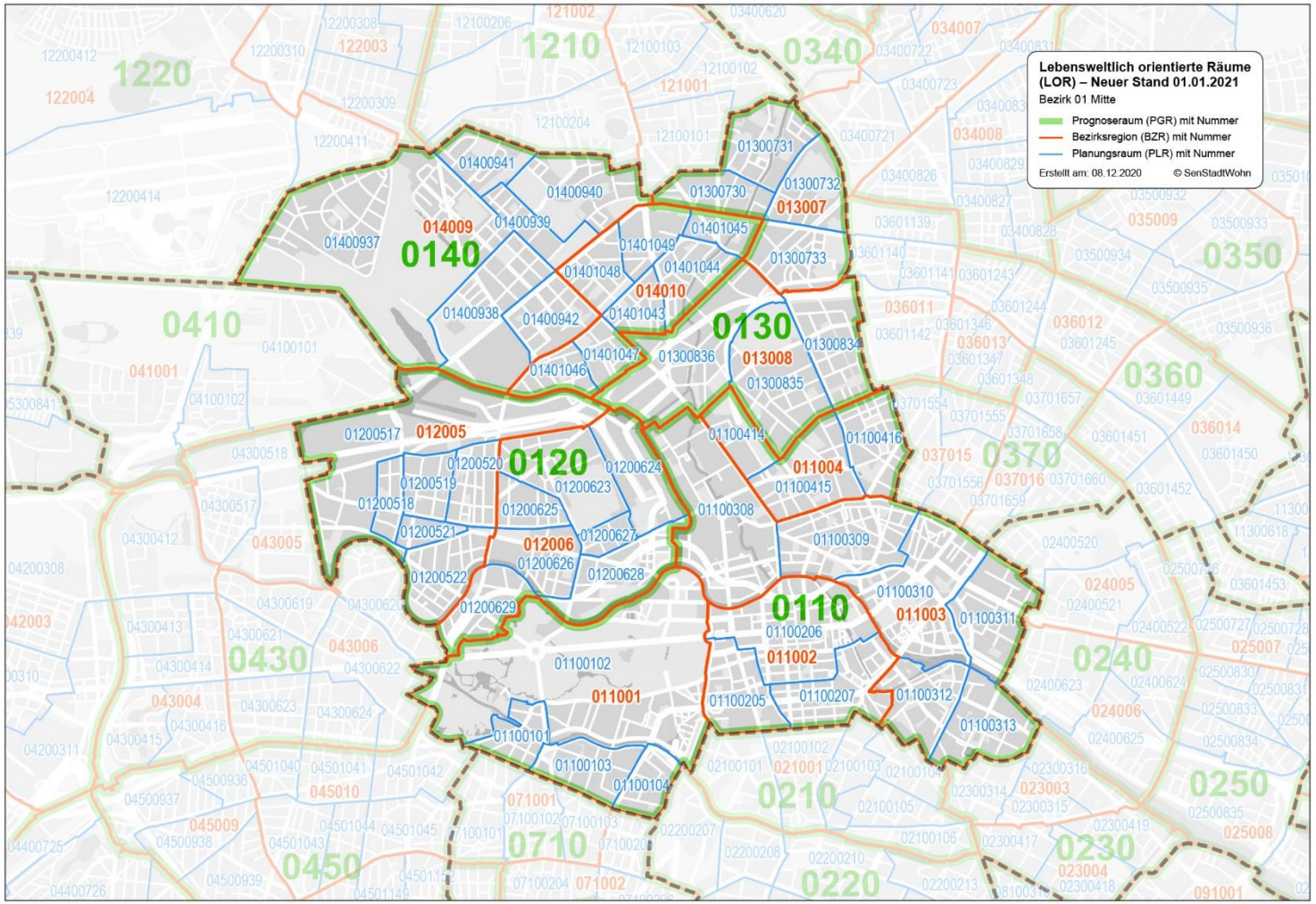

Quelle: eigene Darstellung

Prognoseräume in Mitte

Der Bezirk Mitte hat keine Änderungen an den Zuschnitten der Prognoseräume vorgenommen. Es existieren weiterhin vier Prognoseräume mit durchschnittlich rund 96.400 EW (siehe Tabelle 9), welche weiterhin deutlich über dem Mittelwert aller Bezirke (rund 66.300 EW) liegen. Die meisten Einwohnerinnen und Einwohner weist der Prognoseraum Zentrum (PGR 0110) mit knapp 117.500 EW auf. Der Prognoseraum mit der geringsten Einwohnerzahl ist Gesundbrunnen (PGR 0130) mit rund 78.300 EW.

Tabelle 9: Mitte - Übersicht zu Prognoseräumen vor und nach der Modifikation

	Mitte		**Mittelwert der Bezirke**	
Merkmal (EW-Stand: 31.12.2019)	**LOR-Systematik 2019**	**LOR-Systematik ab 2021**	**LOR-Systematik 2019**	**LOR-Systematik ab 2021**
Anzahl der PGR in Mitte	4	4	5	5
PGR kleinste Einwohnerzahl (Min.)	78.278	78.278	34.826	39.624
Durchschnittliche Einwohnerzahl	96.437	96.437	64.666	66.317
PGR größte Einwohnerzahl (Max.)	117.450	117.450	102.268	98.338
Spannweite (Max. - Min.)	39.172	39.172	67.443	58.714

Quelle: eigene Zusammenstellung

Bezirksregionen in Mitte

Der Bezirk Mitte hat keine Änderungen an den Zuschnitten der Bezirksregionen (BZR) vorgenommen. Es gibt weiterhin 10 BZR, die durchschnittlich 38.600 EW aufweisen, deutlich mehr Einwohnerinnen und Einwohner als im Durchschnitt aller Berliner Bezirke. Die einwohnerreichste Bezirksregion ist Alexanderplatz (BZR 011003) mit über 57.800 EW. Die BZR mit den wenigsten Einwohnerinnen und Einwohnern ist die BZR Regierungsviertel (BZR 011002). Dort lebten zum 31.12.2019 rund 12.700 EW. Die Spannweite der Einwohnerzahl der BZR liegt mit 45.100 EW deutlich über dem Durchschnitt der Bezirke, welcher in der LOR-Systematik ab 2021 rund 30.700 EW umfasst (siehe Tabelle 10).

Tabelle 10: Mitte - Übersicht zu Bezirksregionen vor und nach der Modifikation

	Mitte		**Mittelwert der Bezirke**	
Merkmal (EW-Stand: 31.12.2019)	**LOR-Systematik 2019**	**LOR-Systematik ab 2021**	LOR-Systematik 2019	LOR-Systematik ab 2021
Anzahl der BZR in Mitte	10	10	12	12
BZR kleinste Einwohnerzahl (Min.)	12.742	12.742	13.725	13.235
Durchschnittliche Einwohnerzahl	38.575	38.575	30.027	28.091
BZR größte Einwohnerzahl (Max.)	57.883	57.883	46.031	43.947
Spannweite (Max. - Min.)	45.141	45.141	32.306	30.712

Quelle: eigene Zusammenstellung

Planungsräume in Mitte

Die Anzahl der Planungsräume steigt von 41 auf 49. Auf der kleinräumigsten der LOR-Ebenen wurden insgesamt drei Planungsräume mit weniger als 1.000 Einwohnern durch Zusammenlegung aufgelöst. Gleichzeitig wurden insgesamt acht Planungsräume mit mehr als 15.000 Einwohnern geteilt. Nach Abschluss des Verfahrens liegen damit alle Planungsräume innerhalb der Mindest- und Maximalgröße, wodurch die Spannweite der Einwohnerzahl von 26.768 auf 12.902 deutlich reduziert wurde (siehe Tabelle 11).

Tabelle 11: Mitte - Übersicht zu Planungsräumen vor und nach der Modifikation

	Mitte		Mittelwert der Bezirke	
Merkmal (EW-Stand: 31.12.2019)	**LOR-Systematik 2019**	**LOR-Systematik ab 2021**	LOR-Systematik 2019	LOR-Systematik ab 2021
Anzahl der PLR in Mitte	41	49	37	45
PLR kleinste Einwohnerzahl (Min.)	188	1.755	851	826
Durchschnittliche Einwohnerzahl	9.408	7.872	8.610	6.988
PLR größte Einwohnerzahl (Max.)	26.956	14.657	22.435	13.816
Spannweite (Max. - Min.)	26.768	12.902	21.584	12.990

Quelle: eigene Zusammenstellung

6.3.2 Bezirk Friedrichshain-Kreuzberg

Überblick

Im Bezirk Friedrichshain-Kreuzberg gab es zahlreiche Modifikationen auf Ebene der Planungsräume. Durch Teilung von acht PLR konnte die durchschnittliche Einwohnerzahl an den Mittelwert der Bezirke angenähert werden. Durch die Verschiebung von zwei Blöcken wurde auf Ebene der Bezirksregionen der Grenzverlaufs zwischen der Nördlichen und Südlichen Luisenstadt modifiziert. Auf der Ebene der Prognoseräume erfolgten keine Änderungen.

Die folgende Abbildung 12 zeigt den neuen Zuschnitt der LOR in Friedrichshain-Kreuzberg.

Abbildung 12: LOR in Friedrichshain-Kreuzberg ab 2021

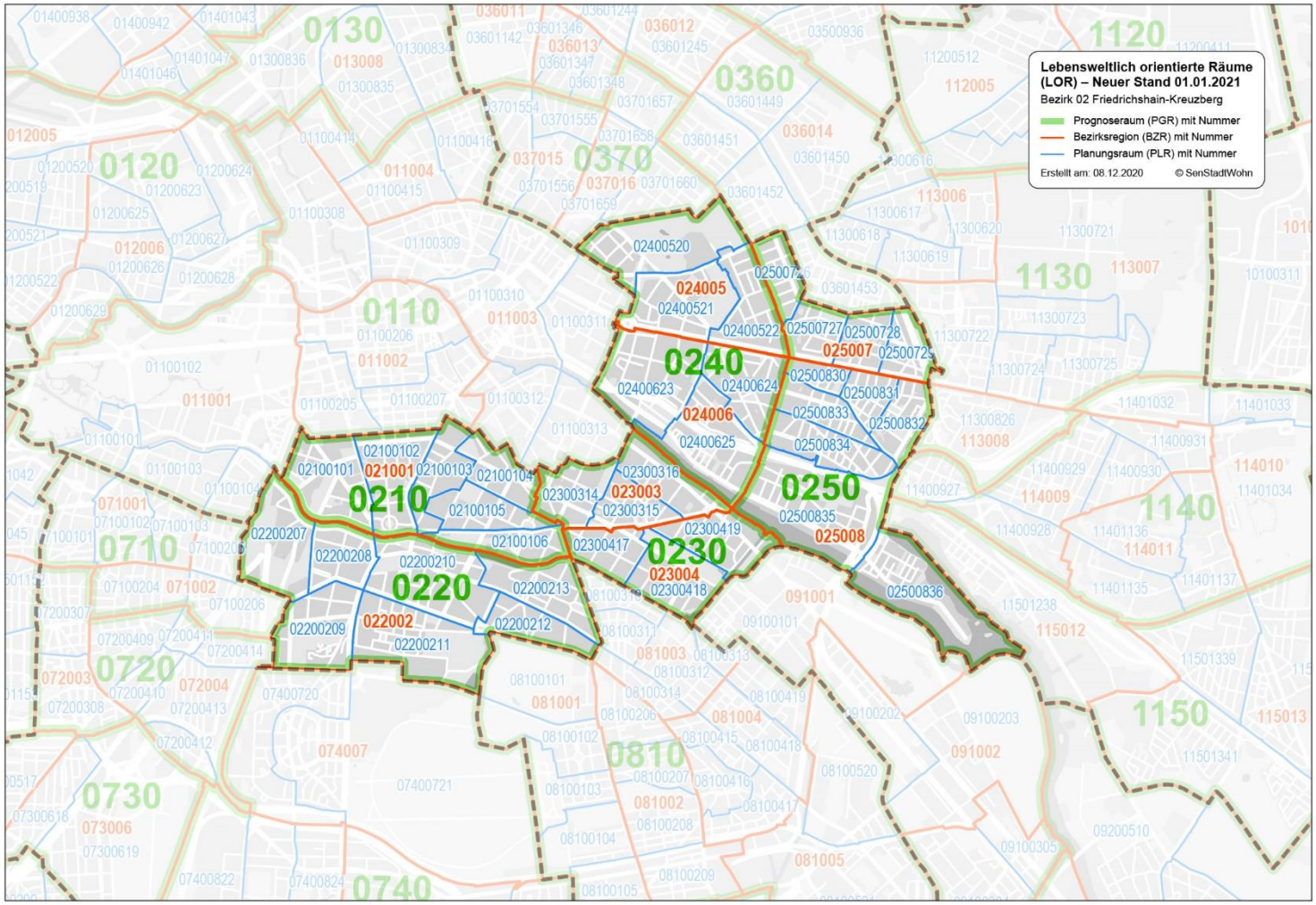

Quelle: eigene Darstellung

LOR in Friedrichshain-Kreuzberg ab 2021

Quelle: eigene Darstellung

Prognoseräume in Friedrichshain-Kreuzberg

Der Bezirk Friedrichshain-Kreuzberg hat keine Änderungen an den Zuschnitten der Prognoseräume vorgenommen. Es bestehen weiterhin fünf Prognoseräume, die durchschnittlich 58.100 EW aufweisen (siehe Tabelle 12). Der größte Prognoseraum ist Friedrichshain Ost (PGR 0250) mit über 85.800 EW. Der PGR mit den wenigsten Einwohnerinnen und Einwohnern ist Kreuzberg Nord (PGR 0210). Dort lebten am 31.12.2019 rund 40.500 EW.

Tabelle 12: Friedrichshain-Kreuzberg - Übersicht zu Prognoseräumen vor und nach der Modifikation

	Friedrichshain-Kreuzberg		**Mittelwert der Bezirke**	
Merkmal (EW-Stand: 31.12.2019)	**LOR-Systematik 2019**	**LOR-Systematik ab 2021**	**LOR-Systematik 2019**	**LOR-Systematik ab 2021**
Anzahl der PGR in Friedrichshain-Kreuzberg	5	5	5	5
PGR kleinste Einwohnerzahl (Min.)	40.530	40.530	34.826	39.624
Durchschnittliche Einwohnerzahl	58.077	58.077	64.666	66.317
PGR größte Einwohnerzahl (Max.)	85.819	85.819	102.268	98.338
Spannweite (Max. - Min.)	45.289	45.289	67.443	58.714

Quelle: eigene Zusammenstellung

Bezirksregionen in Friedrichshain-Kreuzberg

Auf Ebene der Bezirksregionen bestehen weiterhin acht Bezirksregionen, die durchschnittlich 36.300 EW aufweisen (siehe Tabelle 13Tabelle 12). Durch die Verschiebung zweier Blöcke wurde lediglich eine Arrondierung des Grenzverlaufs zwischen der Nördlichen und Südlichen Luisenstadt erreicht. Die Nördliche Luisenstadt (BZR 023003) ist mit rund 20.800 Einwohnerinnen und Einwohnern weiterhin die kleinste Bezirksregion. Die größte Bezirksregion ist die Tempelhofer Vorstadt (BZR 022002) mit über 65.600 EW.

Tabelle 13: Friedrichshain-Kreuzberg - Übersicht zu Bezirksregionen vor und nach der Modifikation

	Friedrichshain-Kreuzberg		**Mittelwert der Bezirke**	
Merkmal (EW-Stand: 31.12.2019)	**LOR-Systematik 2019**	**LOR-Systematik ab 2021**	**LOR-Systematik 2019**	**LOR-Systematik ab 2021**
Anzahl der BZR in Friedrichshain-Kreuzberg	8	8	12	12
BZR kleinste Einwohnerzahl (Min.)	21.989	20.791	13.725	13.235
Durchschnittliche Einwohnerzahl	36.298	36.298	30.027	28.091
BZR größte Einwohnerzahl (Max.)	65.647	65.647	46.031	43.947
Spannweite (Max. - Min.)	43.658	44.856	32.306	30.712

Quelle: eigene Zusammenstellung

Planungsräume in Friedrichshain-Kreuzberg

Die Anzahl der Planungsräume stieg im Zuge der Modifikation von 26 auf 36. Das starke EW-Wachstum in Friedrichshain-Kreuzberg führte dazu, dass die durchschnittliche EW-Zahl der PLR vor der Anpassung bei fast 11.200 EW und damit deutlich über dem Mittelwert der Bezirke lag. Durch die Teilung von acht Planungsräumen liegt der Mittelwert nach der neuen LOR-Systematik leicht unter dem Durchschnitt der zwölf Bezirke (siehe Tabelle 14).

Für den Planungsraum Chamissokiez (PLR 02020205) hat sich der Bezirk Friedrichshain-Kreuzberg aufgrund der einheitlichen Struktur und fehlender Wohnbaupotenziale im PLR gegen eine Teilung entschieden. Dier PLR ist mit rund 15.100 EW der größte Planungsraum. Der PLR mit den wenigsten Einwohnerinnen und Einwohnern ist Wriezener Bahnhof (PLR 02400625). Dort waren am 31.12.2019 1.160 EW gemeldet.

Tabelle 14: Friedrichshain-Kreuzberg - Übersicht zu Planungsräumen vor und nach der Modifikation

	Friedrichshain-Kreuzberg		**Mittelwert der Bezirke**	
Merkmal (EW-Stand: 31.12.2019)	**LOR-Systematik 2019**	**LOR-Systematik ab 2021**	**LOR-Systematik 2019**	**LOR-Systematik ab 2021**
Anzahl der PLR in Friedrichshain-Kreuzberg	26	36	37	45
PLR kleinste Einwohnerzahl (Min.)	1.160	1.160	851	826
Durchschnittliche Einwohnerzahl	11.169	8.066	8.610	6.988
PLR größte Einwohnerzahl (Max.)	21.899	15.140	22.435	13.816
Spannweite (Max. - Min.)	20.739	13.980	21.584	12.990

Quelle: eigene Zusammenstellung

6.3.3 Bezirk Pankow

Überblick

In Pankow gab es zahlreiche Modifikationen der Planungsräume, sowohl was Zuschnitte als auch Namensgebungen anbelangt. Die Ebenen der Bezirksregionen und Prognoseräume wurden nicht modifiziert. Der Bezirk Pankow hat hier zwar einen grundsätzlichen Änderungsbedarf erkannt und attestiert. Von Anpassungen wurde jedoch abgesehen, da a) die aktuelle Bevölkerungsprognose, die mit den Prognoseräumen vor der Modifikation arbeitet, nur sehr eingeschränkt angewendet werden könnte und b) das Jugendamt mit den BZR die Schulplanung betreibt und Änderungen die Arbeit über die Maße erschweren würden.

Abbildung 13 zeigt den neuen Zuschnitt der LOR in Pankow.

Abbildung 13: LOR in Pankow ab 2021

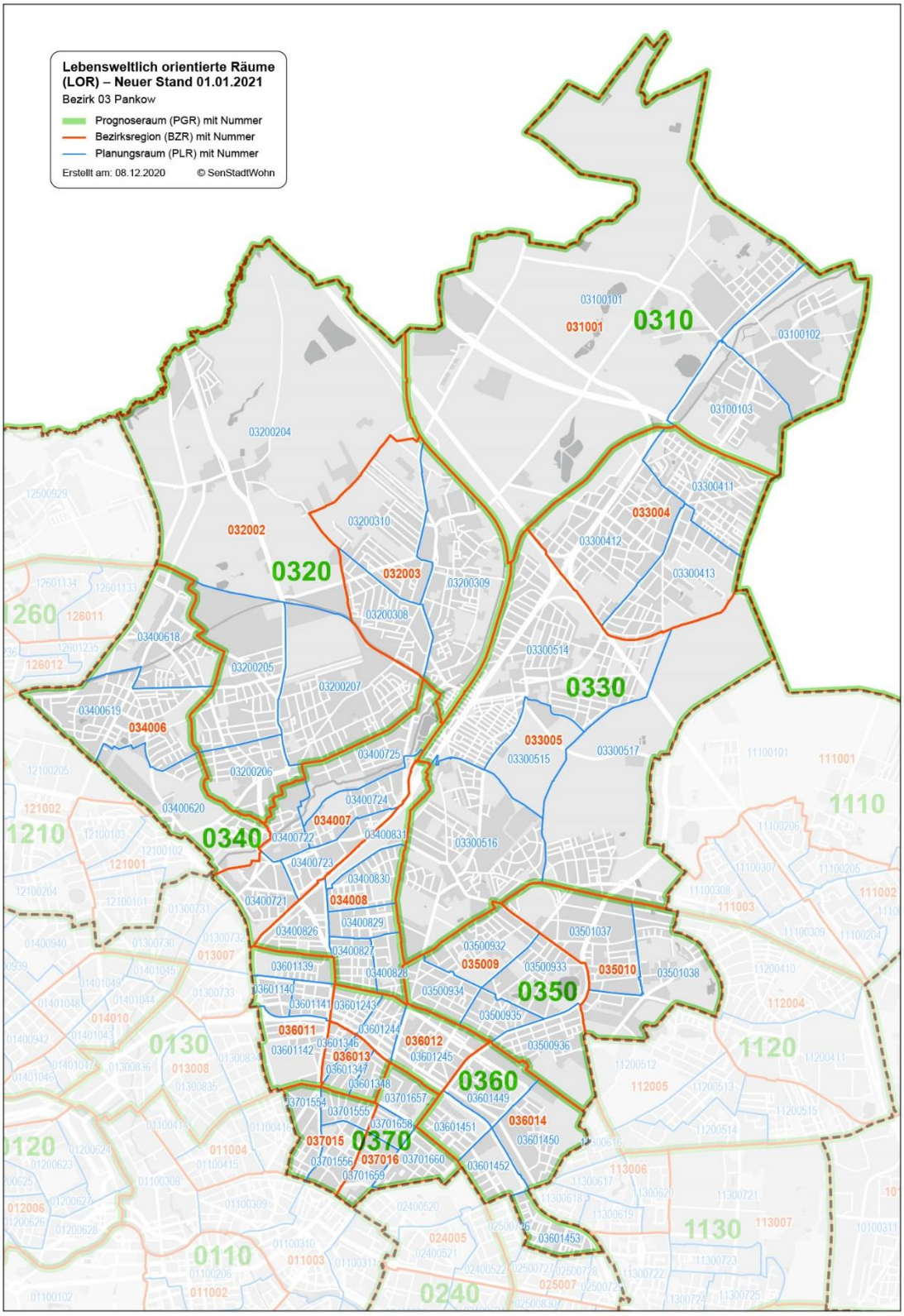

Quelle: eigene Darstellung

Prognoseräume in Pankow

Der Bezirk Pankow hat keine Änderungen an den Zuschnitten der Prognoseräume vorgenommen. Es bestehen weiterhin sieben Prognoseräume, die durchschnittlich 58.500 EW aufweisen (siehe Tabelle 15). Der größte Prognoseraum ist Nördlicher Prenzlauer Berg (PGR 0360) mit über 104.000 EW. Der PGR mit den wenigsten Einwohnerinnen und Einwohnern ist Buch (PGR 0310). Dort lebten am 31.12.2019 rund 17.100 EW.

Tabelle 15: Pankow - Übersicht zu Prognoseräumen vor und nach der Modifikation

	Pankow		Mittelwert der Bezirke	
Merkmal (EW-Stand: 31.12.2019)	**LOR-Systematik 2019**	**LOR-Systematik ab 2021**	LOR-Systema-tik 2019	LOR-Systema-tik ab 2021
Anzahl der PGR in Pankow	7	7	5	5
PGR kleinste Einwohnerzahl (Min.)	17.094	17.094	34.826	39.624
Durchschnittliche Einwohnerzahl	58.476	58.476	64.666	66.317
PGR größte Einwohnerzahl (Max.)	104.046	104.046	102.268	98.338
Spannweite (Max. - Min.)	86.952	86.952	67.443	58.714

Quelle: eigene Zusammenstellung

Bezirksregionen in Pankow

Der Bezirk Pankow hat keine Änderungen an den Zuschnitten der Bezirksregionen vorgenommen. Es gibt weiterhin 16 BZR, die durchschnittlich 25.600 EW aufweisen, weniger als der Durchschnitt der Bezirke (siehe Tabelle 16). Die größte Bezirksregion ist Weißensee (BZR 035009) mit über 38.500 EW. Die BZR mit den wenigsten Einwohnerinnen und Einwohnern ist Weißensee Ost (BZR 035010). Dort lebten am 31.12.2019 rund 15.500 EW.

Tabelle 16: Pankow - Übersicht zu Bezirksregionen vor und nach der Modifikation

	Pankow		Mittelwert der Bezirke	
Merkmal (EW-Stand: 31.12.2019)	**LOR-Systematik 2019**	**LOR-Systematik ab 2021**	LOR-Systematik 2019	LOR-Systematik ab 2021
Anzahl der BZR in Pankow	16	16	12	12
BZR kleinste Einwohnerzahl (Min.)	15.504	15.504	13.725	13.235
Durchschnittliche Einwohnerzahl	25.583	25.583	30.027	28.091
BZR größte Einwohnerzahl (Max.)	38.528	38.528	46.031	43.947
Spannweite (Max. - Min.)	23.024	23.024	32.306	30.712

Quelle: eigene Zusammenstellung

Planungsräume in Pankow

Die Anzahl der PLR ist um 50 Prozent auf 60 gestiegen. Dies ist auch dem starken EW-Wachstum in Pankow geschuldet. Dieses führte dazu, dass die durchschnittliche EW-Zahl der PLR auf über 10.200 wuchs und damit deutlich über dem Mittelwert der Bezirke lag. Dank der zahlreichen Neuzuschnitte, vor allem durch Teilungen, liegt der Mittelwert nun mit der neuen LOR-Systematik leicht unter dem Durchschnitt der zwölf Bezirke (siehe Tabelle 17).

Das Pankower Tor (PLR 03400831) und der PLR Blankenburger Süden (PLR 03300515, 43 EW) weisen derzeit keine bzw. kaum EW auf. Erst mittelfristig ist dort mit dem Zuzug von Bewohnerinnen und Bewohnern in neu entstehenden Wohnraum zu rechnen, weshalb diese PLR entsprechend neu abgegrenzt wurden. Das Märchenland (PLR 03300517) ist mit mehr als 1.100 EW der „eigentlich kleinste" Planungsraum, der derzeit bewohnt ist. Der einwohnerreichste PLR ist Bötzowstraße (PLR 037016609) mit rund 12.900 EW.

Im Rahmen der Modifikationen sind zudem mehrere PLR umbenannt worden, die keinen räumlichen Neuzuschnitt erfahren haben. Eine Liste mit allen neuen Namen befindet sich im Anhang.

Tabelle 17: Pankow - Übersicht zu Planungsräumen vor und nach der Modifikation

	Pankow		Mittelwert der Bezirke	
Merkmal (EW-Stand: 31.12.2019)	**LOR-Systematik 2019**	**LOR-Systematik ab 2021**	LOR-Systematik 2019	LOR-Systematik ab 2021
Anzahl der PLR in Pankow	40	60	37	45
PLR kleinste Einwohnerzahl (Min.)	229	42	851	826
Durchschnittliche Einwohnerzahl	10.233	6.938	8.610	6.988
PLR größte Einwohnerzahl (Max.)	37.024	12.868	22.435	13.816
Spannweite (max – min)	36.795	12.826	21.584	12.990

Quelle: eigene Zusammenstellung

6.3.4 Bezirk Charlottenburg-Wilmersdorf

Überblick

In Charlottenburg-Wilmersdorf lag der Fokus des Bezirks auf allen drei Ebene der LOR. Aus diesem Grund wurden auch die Prognoseräume und Bezirksregionen deutlich modifiziert. Hintergrund sind die Jugendhilfe-Regionen welche künftig mit den Grenzen der Prognoseräume deckungsgleich verlaufen sollen. Die Modifikation der PGR und BZR geht dabei über das Prinzip „Teilen und Zusammenlegen“ hinaus und Grenzverläufe wurden neugezogen. Im Rahmen der Modifikation erfolgte zudem eine geografische Namensgebung für die Prognoseräume im Sinne einer einheitlichen Bezeichnung der Räume.

Abbildung 14 zeigt den neuen Zuschnitt der LOR in Charlottenburg-Wilmersdorf.

Abbildung 14: LOR in Charlottenburg-Wilmersdorf ab 2021

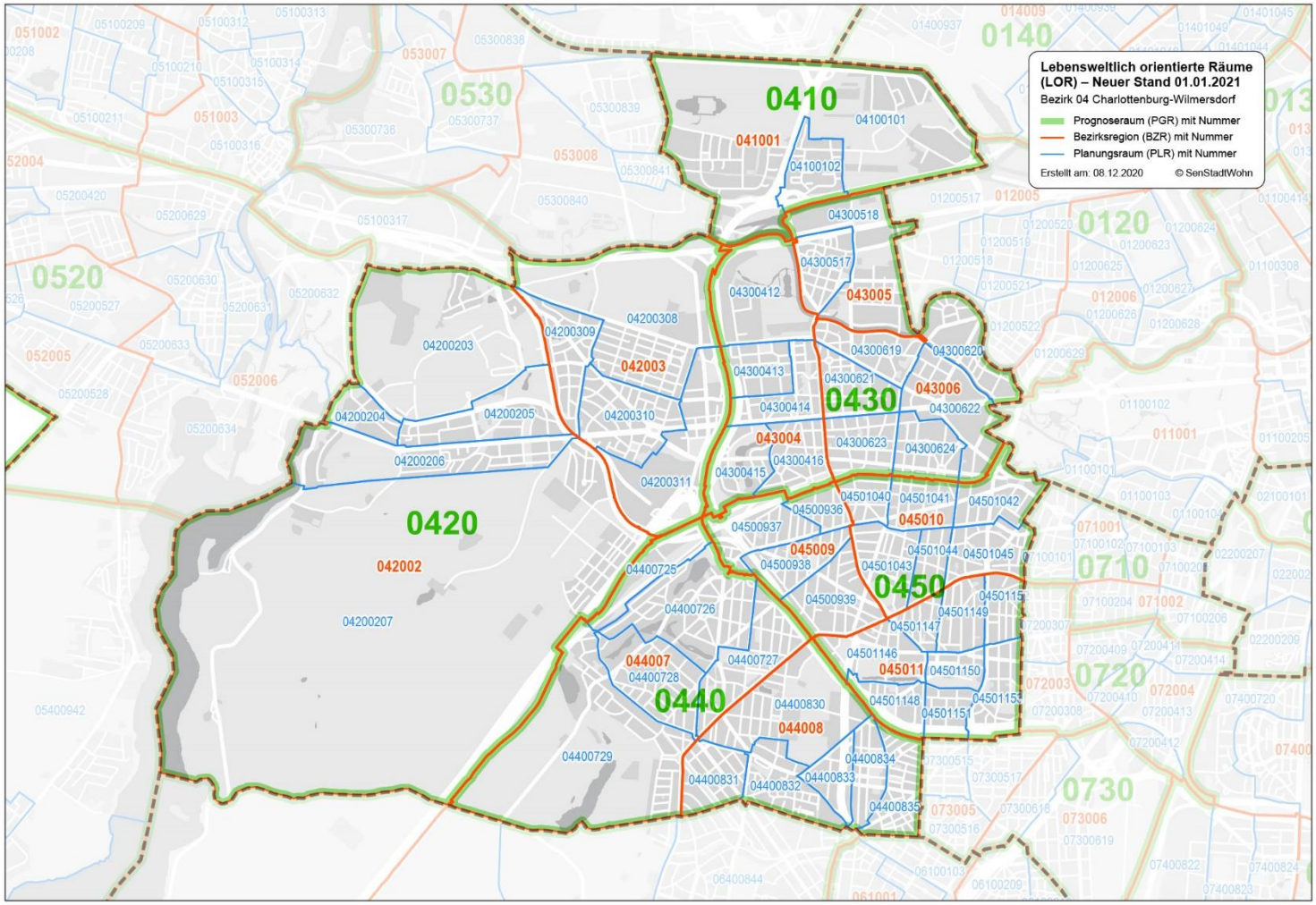

Quelle: eigene Darstellung

Prognoseräume in Charlottenburg-Wilmersdorf

Im Bezirk Charlottenburg-Wilmersdorf wurde die Anzahl der Prognoseräume von sechs auf fünf PGR reduziert und es erfolgte eine neue Namensgebung. Die Modifikation der PGR ging über das Prinzip „Teilen und Zusammenlegen“ hinaus und Grenzverläufe wurden neugezogen. Durch die Arrondierung der BZR Halensee und Lietzenburger Straße zum PGR Wilmersdorfer Zentrum wurde der Grenzverlauf zwischen dem PGR Charlottenburger Zentrum (PGR 0430) und dem PGR Wilmersdorfer Zentrum (PGR 0450) entlang der Bahntrasse der S- und Regional-Bahn neu zugeschnitten. Der PGR CW 6 wurde aufgelöst und überwiegend dem PGR Charlottenburg West (PGR 0420) zugeordnet. Die östlich der Bahngleise gelegenen Blöcke (047111, 047112) wurden dem PGR Wilmersdorf Süd (PGR 0440) zugesprochen.

Die durchschnittliche Einwohnerzahl hat sich auf 68.700 EW erhöht und liegt damit leicht über dem Mittelwert der Bezirke (siehe Tabelle 18). Der PGR Charlottenburg Nord (PGR 0410) weist weiterhin mit knapp 19.600 Personen die wenigsten Einwohnerinnen und Einwohner auf, der neu zugeschnittene Prognoseraum Wilmersdorf Zentrum (PGR 0450) mit rund 119.400 EW die meisten.

Tabelle 18: Charlottenburg-Wilmersdorf – Übersicht zu Prognoseräumen vor und nach der Modifikation

	Charlottenburg-Wilmersdorf		**Mittelwert der Bezirke**	
Merkmal (EW-Stand: 31.12.2019)	**LOR-Systematik 2019**	**LOR-Systematik ab 2021**	**LOR-Systematik 2019**	**LOR-Systematik ab 2021**
Anzahl der PGR in Charlottenburg-Wilmersdorf	6	5	5	5
PGR kleinste Einwohnerzahl (Min.)	68	19.579	34.826	39.624
Durchschnittliche Einwohnerzahl	57.265	68.718	64.666	66.317
PGR größte Einwohnerzahl (Max.)	146.437	119.359	102.268	98.338
Spannweite (Max. - Min.)	146.369	99.780	67.443	58.714

Quelle: eigene Zusammenstellung

Bezirksregionen in Charlottenburg-Wilmersdorf

Die Anzahl der Bezirksregionen wurde von 17 auf 11 BZR reduziert. Die vor der Modifikation deutlich unter dem gesamtstädtischen Mittelwert liegende durchschnittliche EW-Anzahl wurde damit auf rund 31.200 EW erhöht (siehe Tabelle 19). Durch die Zusammenlegung wurden gering bewohnte BZR aufgelöst, sodass die BZR Heerstraße (BZR 042002) nun mit etwas mehr als 13.200 EW die Bezirksregion mit den wenigsten Einwohnerinnen und Einwohnern ist. Die BZR Otto-Suhr-Allee/Kantstraße (BZR 043006) ist nach der Arrondierung von den PLR Karl-August-Platz und Savignyplatz nun mit rund 50.200 EW die bevölkerungsreichste Bezirksregion.

Mit der Neustrukturierung des Grenzverlaufs des PGR Wilmersdorf Zentrum, wurden der PGR durch Zusammenlegung von Bezirksregionen und neuer Grenzverläufe entlang räumlicher Barrieren, wie der Lewishamstraße, neugeordnet. Der PGR Wilmersdorf Zentrum besteht nun aus den drei BZR Halensee (BZR 045009), Lietzenburger Straße (045019) und Volkspark Wilmersdorf (045011).

Im Rahmen der Modifikationen sind zudem mehrere BZR umbenannt worden, die keinen räumlichen Neuzuschnitt erfahren haben. Eine Liste mit allen neuen Namen befindet sich im Anhang.

Tabelle 19: Charlottenburg-Wilmersdorf - Übersicht zu Bezirksregionen vor und nach der Modifikation

	Charlottenburg-Wilmersdorf		**Mittelwert der Bezirke**	
Merkmal (EW-Stand: 31.12.2019)	**LOR-Systematik 2019**	**LOR-Systematik ab 2021**	**LOR-Systematik 2019**	**LOR-Systematik ab 2021**
Anzahl der BZR in Charlottenburg-Wilmersdorf	17	11	12	12
BZR kleinste Einwohnerzahl (Min.)	68	13.212	13.725	13.235
Durchschnittliche Einwohnerzahl	20.211	31.236	30.027	28.091
BZR größte Einwohnerzahl (Max.)	35.299	50.242	46.031	43.947
Spannweite (Max. - Min.)	35.231	37.030	32.306	30.712

Quelle: eigene Zusammenstellung

Planungsräume in Charlottenburg-Wilmersdorf

Die Anzahl der Planungsräume wurde im Bezirk Charlottenburg-Wilmersdorf von 57 auf 53 PLR reduziert. Der Bezirk wies mehrere gering bewohnten bzw. unbewohnten Planungsräumen auf. Um weiterhin eine Bereitstellung kleinräumiger Daten der Bundesagentur für Arbeit zu garantieren, wurden diese PLR mit angrenzenden PLR zusammengelegt. Die durchschnittliche Einwohnerzahl ist nach der Modifikation auf rund 6.500 EW gestiegen (siehe Tabelle 20). Der PLR Güterbahnhof Grunewald (PLR 04400725), in dem mittelfristig mit Wohnungsneubau zu rechnen ist, stellt derzeit mit 106 Einwohnerinnen und Einwohnern den am geringsten bewohnten Planungsraum dar. Der PLR Amtsgerichtsplatz (PLR 04300416) ist mit mehr als 12.400 EW der bevölkerungsstärkste PLR des Bezirks.

Tabelle 20: Charlottenburg-Wilmersdorf - Übersicht zu Planungsräumen vor und nach der Modifikation

	Charlottenburg-Wilmersdorf		**Mittelwert der Bezirke**	
Merkmal (EW-Stand: 31.12.2019)	**LOR-Systematik 2019**	**LOR-Systematik ab 2021**	**LOR-Systematik 2019**	**LOR-Systematik ab 2021**
Anzahl der PLR in Charlottenburg-Wilmersdorf	57	53	37	45
PLR kleinste Einwohnerzahl (Min.)	9	106	851	826
Durchschnittliche Einwohnerzahl	6.028	6.483	8.610	6.988
PLR größte Einwohnerzahl (Max.)	15.756	12.434	22.435	13.816
Spannweite (Max. - Min.)	15.747	12.328	21.584	12.990

Quelle: eigene Zusammenstellung

6.3.5 Bezirk Spandau

Überblick

In Spandau gab es zahlreiche Modifikationen der Planungsräume, sowohl was Zuschnitte als auch Namensgebungen anbelangt. Auf der Ebenen der Bezirksregionen und Prognoseräume wurden durch Blockverschiebungen vereinzelt Grenzverläufe angepasst. Es wurden keine Teilungen und Zusammenlegungen von Bezirksregionen und Prognoseräumen vorgenommen. Für die vier Prognoseräume erfolgte eine einheitliche Namensgebung durch den Bezirk.

Abbildung 15 zeigt den neuen Zuschnitt der LOR in Spandau.

Abbildung 15: LOR in Spandau ab 2021

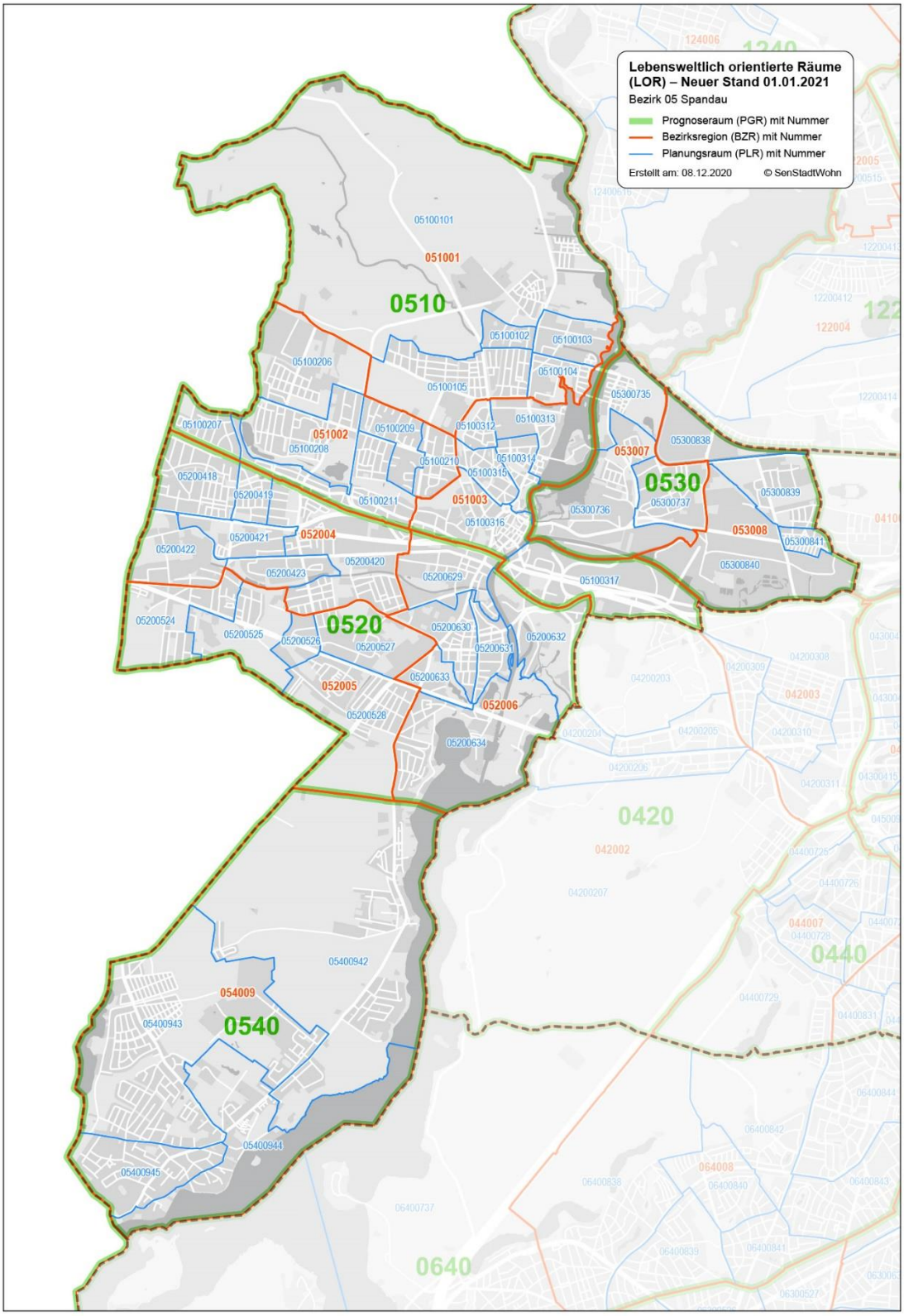

Quelle: eigene Darstellung

Prognoseräume in Spandau

Im Bezirk Spandau gibt es weiterhin vier Prognoseräume mit durchschnittlich 61.300 Einwohnerinnen und Einwohnern. Durch die Arrondierung von zwei Blöcken (032358, 032359) wurde der Grenzverlauf zwischen dem PGR Spandau Mitte / Nord (PGR 0510) und dem PGR Wilhelmstadt / Staaken (PGR 0520) entlang der Ruhlebener Straße angepasst. Im Rahmen der Modifikation erfolgte zudem eine geografische Namensgebung für die vier Prognoseräume im Sinne einer einheitlichen Bezeichnung der Räume. Der größte Prognoseraum ist Spandau Mitte / Nord (PGR 0510) mit über 106.600 EW. Der PGR mit den wenigsten Einwohnerinnen und Einwohnern ist Gatow / Kladow (PGR 0540). Dort lebten am 31.12.2019 rund 19.900 EW. Die Spannweite zwischen den PGR liegt mit rund 86.700 EW weiterhin über dem Mittelwert der Bezirke mit 58.700 EW (siehe Tabelle 21).

Tabelle 21: Spandau - Übersicht zu Prognoseräumen vor und nach der Modifikation

	Spandau		Mittelwert der Bezirke	
Merkmal (EW-Stand: 31.12.2019)	**LOR-Systematik 2019**	**LOR-Systematik ab 2021**	LOR-Systematik 2019	LOR-Systematik ab 2021
Anzahl der PGR in Spandau	4	4	5	5
PGR kleinste Einwohnerzahl (Min.)	19.945	19.945	34.826	39.624
Durchschnittliche Einwohnerzahl	61.299	61.299	64.666	66.317
PGR größte Einwohnerzahl (Max.)	105.978	106.631	102.268	98.338
Spannweite (Max. - Min.)	86.033	86.686	67.443	58.714

Quelle: eigene Zusammenstellung

Bezirksregionen in Spandau

Der Bezirk Spandau hat keine Teilungen oder Zusammenlegungen der Bezirksregionen vorgenommen. Durch die Verschiebung von (bisher) unbewohnten Blöcken wurde jedoch vereinzelt Grenzverläufe zwischen den Bezirksregionen angepasst. Die Arrondierung der Grenzverläufe resultiert zumeist aus bestehenden städtebaulichen Barrieren innerhalb der Bezirksregionen. Es gibt weiterhin neun BZR, die durchschnittlich 27.200 EW aufweisen. Die größte Bezirksregion ist Falkenhagener Feld (BZR 051002) mit über 42.000 EW. Die BZR mit den wenigsten Einwohnerinnen und Einwohnern ist Siemensstadt (BZR 053008). Dort lebten am 31.12.2019 rund 12.800 EW (siehe Tabelle 22).

Tabelle 22: Spandau - Übersicht zu Bezirksregionen vor und nach der Modifikation

	Spandau		**Mittelwert der Bezirke**	
Merkmal (EW-Stand: 31.12.2019)	**LOR-Systematik 2019**	**LOR-Systematik ab 2021**	LOR-Systema-tik 2019	LOR-Systema-tik ab 2021
Anzahl der BZR in Spandau	9	9	12	12
BZR kleinste Einwohnerzahl (Min.)	12.831	12.831	13.725	13.235
Durchschnittliche Einwohnerzahl	27.244	27.244	30.027	28.091
BZR größte Einwohnerzahl (Max.)	42.031	42.031	46.031	43.947
Spannweite (Max. - Min.)	29.200	29.200	32.306	30.712

Quelle: eigene Zusammenstellung

Planungsräume in Spandau

Die Anzahl der Planungsräume ist von 39 auf 45 PLR gestiegen. Die durchschnittliche Einwohnerzahl der PLR liegt nun bei rund 5.400 EW. Die Anpassungen erhöhen die Homogenität der PLR innerhalb des Bezirks, erleichtern aber auch Vergleiche über die Bezirksgrenzen hinaus. Die vor der Modifikation bestehende Spannweite der EW-Zahlen zwischen den Planungsräumen von fast 17.800 EW, ist durch die Modifikation auf 11.900 EW deutlich gesunken (siehe Tabelle 23).

Der Planungsraum Gartenfeld (PLR 05300838), in dem zukünftig mit weiterem Wohnungsneubau zu rechnen ist, stellt derzeit den kleinsten PLR mit knapp 30 EW dar. Der PLR Maulbeerallee (PLR 05200527) ist mit rund 12.000 EW der bevölkerungsstärkste PLR des Bezirks.

Tabelle 23: Spandau - Übersicht zu Planungsräumen vor und nach der Modifikation

	Spandau		Mittelwert der Bezirke	
Merkmal (EW-Stand: 31.12.2019)	**LOR-Systematik 2019**	**LOR-Systematik ab 2021**	LOR-Systematik 2019	LOR-Systematik ab 2021
Anzahl der PLR in Spandau	39	45	37	45
PLR kleinste Einwohnerzahl (Min.)	457	27	851	826
Durchschnittliche Einwohnerzahl	6.287	5.449	8.610	6.988
PLR größte Einwohnerzahl (Max.)	18.244	11.954	22.435	13.816
Spannweite (Max. - Min.)	17.787	11.927	21.584	12.990

Quelle: eigene Zusammenstellung

6.3.6 Bezirk Steglitz-Zehlendorf

Überblick

Im Bezirk Steglitz-Zehlendorf wurde im Rahmen der Modifikationen die Anzahl der Planungsräume durch Teilung von 41 auf 44 erhöht. Die Teilungen der Planungsräume erfolgten aufgrund der bestehenden hohen Einwohnerzahlen bzw. zukünftig erwarteter Bevölkerungsentwicklungen. Für die Ebenen der Bezirksregionen und Prognoseräume wurden keine Neuzuschnitte vorgenommen. Die Namen der Prognoseräume wurden im Sinne einer geografischen Bezeichnung angepasst.

Abbildung 16 zeigt den neuen Zuschnitt der LOR in Steglitz-Zehlendorf.

Abbildung 16: LOR in Steglitz-Zehlendorf ab 2021

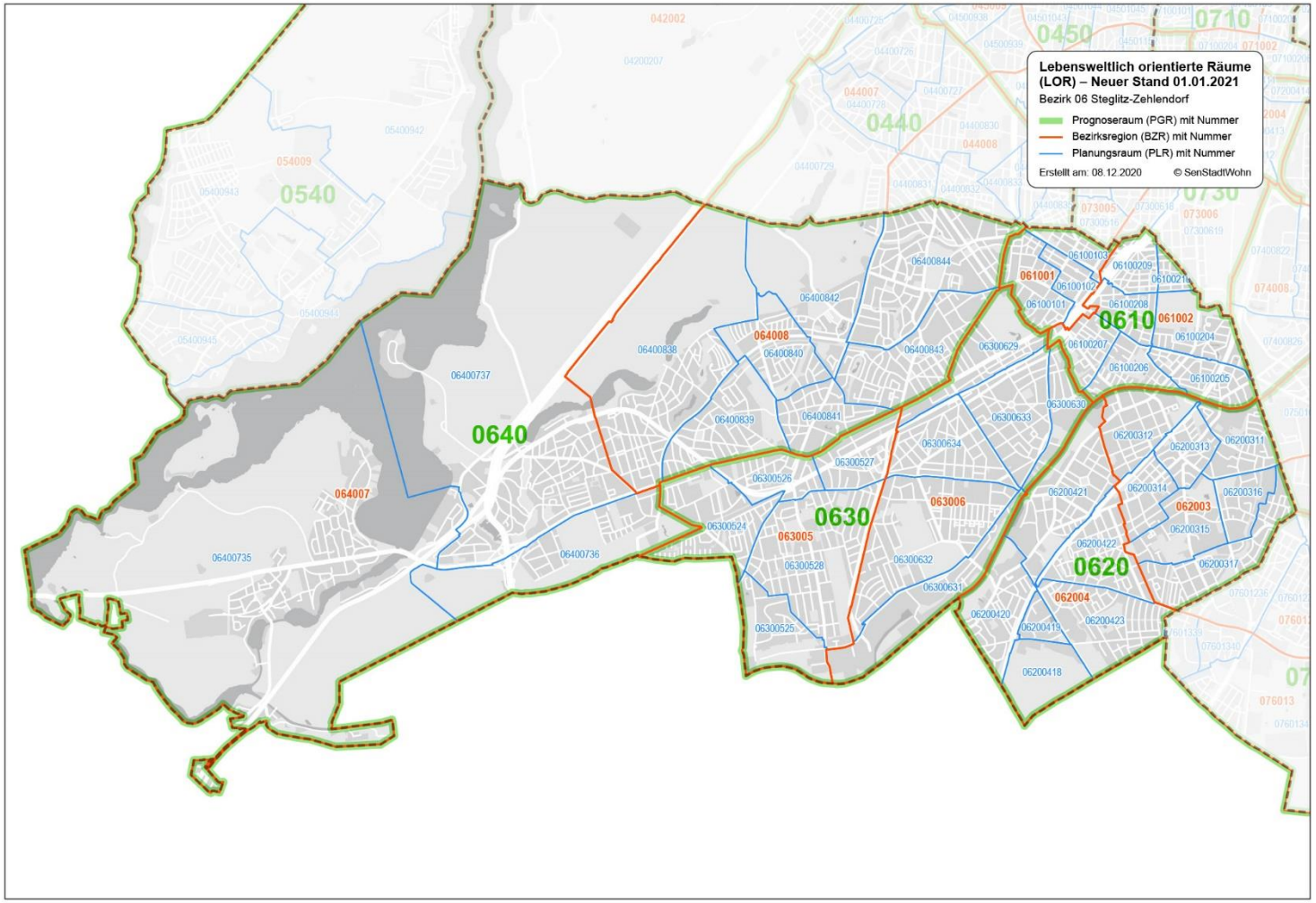

Quelle: eigene Darstellung

Prognoseräume in Steglitz-Zehlendorf

Der Bezirk Steglitz-Zehlendorf hat keine Änderungen an den Zuschnitten der Prognoseräume vorgenommen. Es bestehen weiterhin vier Prognoseräume, die durchschnittlich 77.500 EW aufweisen. Der größte Prognoseraum ist Zehlendorf Süd/Lichterfelde West (PGR 0630) mit über 84.700 EW. Der PGR mit den wenigsten Einwohnerinnen und Einwohnern ist Zehlendorf Nord/Wannsee (PGR 0640). Dort lebten am 31.12.2019 rund 70.200 EW. Damit sind die Prognoseräume in ihrer Einwohneranzahl sehr homogen und weisen eine sehr geringe Spannweite auf, die deutlich unter dem Mittelwert der Berliner Bezirke liegt (siehe Tabelle 24).

Im Rahmen der Modifikation erfolgte eine geografische Namensgebung für die vier Prognoseräume im Sinne einer einheitlichen Bezeichnung der Räume.

Tabelle 24: Steglitz-Zehlendorf - Übersicht zu Prognoseräumen vor und nach der Modifikation

	Steglitz-Zehlendorf		**Mittelwert der Bezirke**	
Merkmal (EW-Stand: 31.12.2019)	**LOR-Systematik 2019**	**LOR-Systematik ab 2021**	**LOR-Systematik 2019**	**LOR-Systematik ab 2021**
Anzahl der PGR in Steglitz-Zehlendorf	4	4	5	5
PGR kleinste Einwohnerzahl (Min.)	70.163	70.163	34.826	39.624
Durchschnittliche Einwohnerzahl	77.523	77.523	64.666	66.317
PGR größte Einwohnerzahl (Max.)	84.718	84.718	102.268	98.338
Spannweite (Max. - Min.)	14.555	14.555	67.443	58.714

Quelle: eigene Zusammenstellung

Bezirksregionen in Steglitz-Zehlendorf

Der Bezirk Steglitz-Zehlendorf hat keine Änderungen an den Zuschnitten der Bezirksregionen vorgenommen. Es gibt weiterhin acht BZR, die durchschnittlich 38.800 EW aufweisen, deutlich mehr als im Durchschnitt der Berliner Bezirke (siehe Tabelle 25). Die Spannweite zwischen der größte Bezirksregion Albrechtstraße (BZR 061002) mit fast 53.600 EW und der BZR Schloßstraße (BZR 061001) mit den wenigsten Einwohnerinnen und Einwohnern entspricht in etwa dem Mittelwert aller Bezirke.

Tabelle 25: Steglitz-Zehlendorf - Übersicht zu Bezirksregionen vor und nach der Modifikation

	Steglitz-Zehlendorf		Mittelwert der Bezirke	
Merkmal (EW-Stand: 31.12.2019)	**LOR-Systematik 2019**	**LOR-Systematik ab 2021**	LOR-Systematik 2019	LOR-Systematik ab 2021
Anzahl der BZR in Steglitz-Zehlendorf	8	8	12	12
BZR kleinste Einwohnerzahl (Min.)	22.221	22.221	13.725	13.235
Durchschnittliche Einwohnerzahl	38.762	38.762	30.027	28.091
BZR größte Einwohnerzahl (Max.)	53.582	53.582	46.031	43.947
Spannweite (Max. - Min.)	31.361	31.361	32.306	30.712

Quelle: eigene Zusammenstellung

Planungsräume in Steglitz-Zehlendorf

Die Anzahl der Planungsräume ist von 41 auf 44 PLR gestiegen. Die durchschnittliche Einwohnerzahl der PLR liegt nun bei rund 7.000 Einwohnerinnen und Einwohnern (siehe Tabelle 26). Im Rahmen der Modifikation wurden die Planungsräume Thermometersiedlung, Gemeindepark Lankwitz und Zehlendorf Mitte aufgrund ihrer Einwohnerzahl bzw. zukünftig erwarteten Einwohnerzahl geteilt. Zwischen dem neuen PLR Landweg (PLR 06200418) und Lichterfelde Süd (PLR 06200420) erfolgt durch eine Blockverschiebung eine Anpassung des Grenzverlaufs entlang der Bahngleise.

Im PLR Landweg (PLR 06200418) sind derzeit kaum Menschen gemeldet. Erst mittelfristig ist dort mit dem Zuzug von Bewohnerinnen und Bewohnern in neu entstehenden Wohngebieten zu rechnen, weshalb dieser PLR neu abgegrenzt wurde. Der PLR Schweizer Viertel (PLR 06300632) ist mit rund 13.800 EW der bevölkerungsstärkste PLR des Bezirks.

Tabelle 26: Steglitz-Zehlendorf - Übersicht zu Planungsräumen vor und nach der Modifikation

	Steglitz-Zehlendorf		**Mittelwert der Bezirke**	
Merkmal (EW-Stand: 31.12.2019)	**LOR-Systematik 2019**	**LOR-Systematik ab 2021**	**LOR-Systematik 2019**	**LOR-Systematik ab 2021**
Anzahl der PLR in Steglitz-Zehlendorf	41	44	37	45
PLR kleinste Einwohnerzahl (Min.)	3.148	21	851	826
Durchschnittliche Einwohnerzahl	7.563	7.048	8.610	6.988
PLR größte Einwohnerzahl (Max.)	13.784	13.784	22.435	13.816
Spannweite (Max. - Min.)	10.636	13.763	21.584	12.990

Quelle: eigene Zusammenstellung

6.3.7 Bezirk Tempelhof-Schöneberg

Überblick

Im Bezirk Tempelhof-Schöneberg sind auf allen drei Ebene Modifikationen vorgenommen worden. Auf der Ebene der Bezirksregionen und der Planungsräume gibt es mit der LOR-Systematik ab 2021 mehr LOR als zuvor. Die neuen LOR-Zuschnitte sind daher vor allem durch Teilungen bisher bestehender Räume entstanden. Auf der Ebene der Prognoseräume gab es hingegen eine Konsolidierung.

Abbildung 17 zeigt den neuen Zuschnitt der LOR in Tempelhof-Schöneberg.

Abbildung 17: LOR in Tempelhof-Schöneberg ab 2021

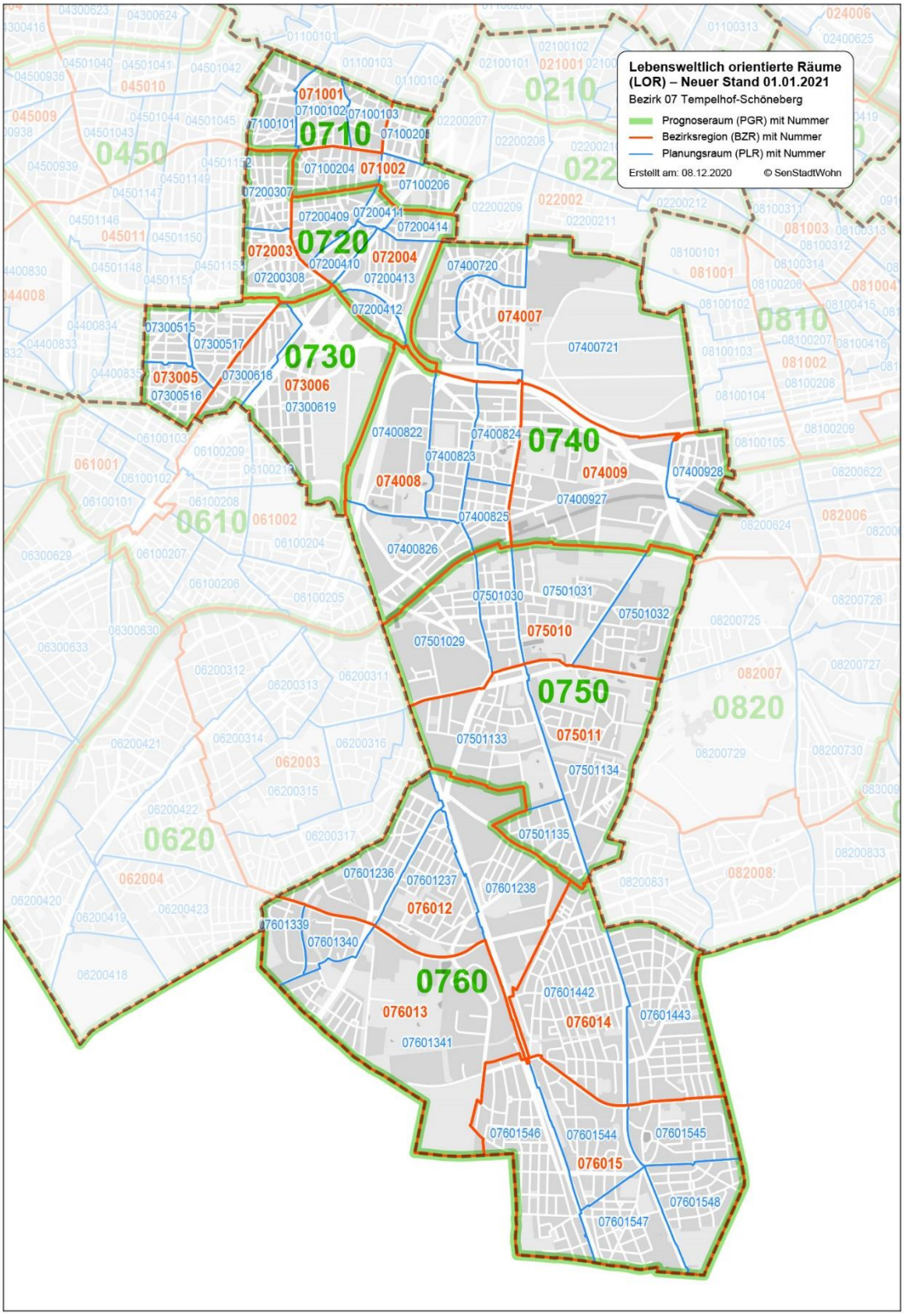

Quelle: eigene Darstellung

Prognoseräume in Tempelhof-Schöneberg

Es erfolgte eine Reduktion von sieben auf sechs PGR (siehe Tabelle 27). Die bisherigen Prognoseräume Marienfelde und Lichtenrade wurden zusammengelegt. Sie bilden nun den PGR Marienfelde / Lichtenrade. Damit wird insbesondere der EW-schwächere PGR Marienfelde (32.000 EW) einem größeren Raum zugeordnet. Durch die Zusammenlegung entsteht der größte PGR des Bezirks, der nun über 84.000 EW aufweist. Für den Bezirk erhöht sich damit die durchschnittliche Einwohnerzahl von 50.000 auf über 58.000 EW. Friedenau (0730) ist mit 46.428 EW nun der PGR mit den wenigsten Bewohnerinnen und Bewohnern im Bezirk.

Tabelle 27: Tempelhof-Schöneberg - Übersicht zu Prognoseräumen vor und nach der Modifikation

	Tempelhof-Schöneberg		**Mittelwert der Bezirke**	
Merkmal (EW-Stand: 31.12.2019)	**LOR-Systematik 2019**	**LOR-Systematik ab 2021**	LOR-Systematik 2019	LOR-Systematik ab 2021
Anzahl der PGR in Tempelhof-Schöneberg	7	6	5	5
PGR kleinste Einwohnerzahl (Min.)	32.337	46.428	34.826	39.624
Durchschnittliche Einwohnerzahl	50.141	58.497	64.666	66.317
PGR größte Einwohnerzahl (Max.)	65.094	84.292	102.268	98.338
Spannweite (Max. - Min.)	32.757	37.864	67.443	58.714

Quelle: eigene Zusammenstellung

Bezirksregionen in Tempelhof-Schöneberg

Die BZR wurden von sieben auf 15 erhöht. Die Teilungen entsprechen den Zielen des Prozesses und erweitern die bisherige Hierarchie der LOR im gewünschten Sinne. Bisher galt, dass PGR und BZR identisch waren (gleicher Zuschnitt). Nun gibt es eine 1:n-Beziehung über alle drei LOR-Ebenen. Die Teilung der BZR orientierte sich zumeist an städtebaulichen Barrieren und bildet damit lebensweltliche Grenzen ab. Die entstandene durchschnittliche Anzahl von rund 23.400 EW entspricht nun eher dem Mittelwert der zwölf Bezirke von 28.100 EW (siehe Tabelle 28). Marienfelde Süd (BZR 076013) weist nun mit 14.500 Personen die wenigsten Einwohnerinnen und Einwohner auf, Tempelhof Südwest (BZR 074008) mit über 32.000 die meisten.

Tabelle 28: Tempelhof-Schöneberg - Übersicht zu Bezirksregionen vor und nach der Modifikation

	Tempelhof-Schöneberg		**Mittelwert der Bezirke**	
Merkmal (EW-Stand: 31.12.2019)	**LOR-Systematik 2019**	**LOR-Systematik ab 2021**	**LOR-Systematik 2019**	**LOR-Systematik ab 2021**
Anzahl der BZR in Tempelhof-Schöneberg	7	15	12	12
BZR kleinste Einwohnerzahl (Min.)	32.337	14.506	13.725	13.235
Durchschnittliche Einwohnerzahl	50.141	23.399	30.027	28.091
BZR größte Einwohnerzahl (Max.)	65.094	32.108	46.031	43.947
Spannweite (Max. - Min.)	32.757	17.602	32.306	30.712

Quelle: eigene Zusammenstellung

Planungsräume in Tempelhof-Schöneberg

Die Anzahl der Planungsräume ist von 34 auf 48 deutlich gestiegen. Die vor der Modifikation über dem gesamtstädtischen Durchschnitt liegende EW-Anzahl der PLR ist damit deutlich gesunken. Sie liegt nun bei circa 7.300 EW und somit nur noch leicht über dem Berliner Bezirks-Mittelwert (siehe Tabelle 29). Die Anpassungen erhöhen die Homogenität der PLR innerhalb des Bezirks, aber auch für den Vergleich über die Bezirksgrenzen hinaus.

Die Schöneberger Linse (PLR 07200412), in der zukünftig mit weiterem Wohnungsneubau zu rechnen ist, stellt derzeit den kleinsten PR mit etwas über 400 EW dar. Der Grazer Platz (PLR 07300619) ist mit 12.248 EW der bevölkerungsstärkste PLR des Bezirks.

Tabelle 29: Tempelhof-Schöneberg - Übersicht zu Planungsräumen vor und nach der Modifikation

	Tempelhof-Schöneberg		**Mittelwert der Bezirke**	
Merkmal (EW-Stand: 31.12.2019)	**LOR-Systematik 2019**	**LOR-Systematik ab 2021**	**LOR-Systematik 2019**	**LOR-Systematik ab 2021**
Anzahl der PLR in Tempelhof-Schöneberg	34	48	37	45
PLR kleinste Einwohnerzahl (Min.)	2.254	443	851	826
Durchschnittliche Einwohnerzahl	10.323	7.312	8.610	6.988
PLR größte Einwohnerzahl (Max.)	24.771	12.248	22.435	13.816
Spannweite (Max. - Min.)	22.517	11.805	21.584	12.990

Quelle: eigene Zusammenstellung

6.3.8 Bezirk Neukölln

Überblick

Im Bezirk Neukölln erfolgte im Rahmen der Modifikationen Anpassungen auf Ebene der Planungsräume und der Bezirksregionen. Durch Teilung und Zusammenlegung im Sinne der übergeordneten Ziele des Prozesses wurden die PLR und BZR den anvisierten Zielgrößen angepasst und die angestrebte Hierarchie der LOR-Systematik gestärkt. Auf der Ebene der Prognoseräume wurden keine Änderungen vorgenommen.

Abbildung 18 zeigt den neuen Zuschnitt der LOR in Neukölln.

Abbildung 18: LOR in Neukölln ab 2021

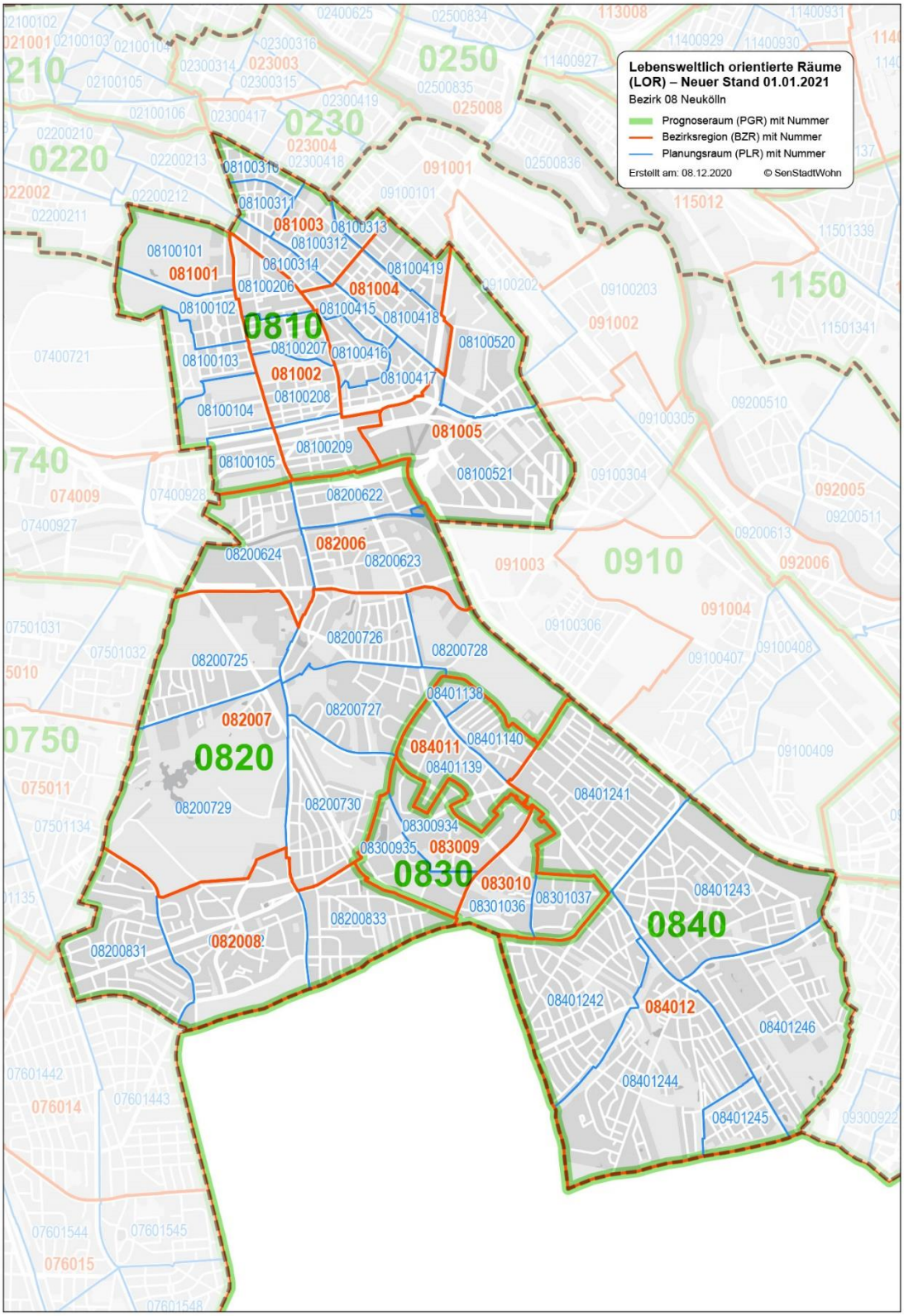

Quelle: eigene Darstellung

Prognoseräume in Neukölln

Der Bezirk Neukölln hat keine Änderungen an den Zuschnitten der Prognoseräume vorgenommen. Es bestehen weiterhin vier Prognoseräume, die durchschnittlich 82.500 EW aufweisen und in ihrer Einwohnergröße damit über dem Mittelwert der Berliner Bezirke liegen (siehe Tabelle 30). Die Einwohnerzahlen der Prognoseräume beträgt zwischen rund 166.200 Einwohnerinnen und Einwohnern im PGR Neukölln (PGR 0810) und 37.500 EW im PGR Gropiusstadt (PGR 0830). Damit ist die Spannweite zwischen den Prognoseräumen in Neukölln rund doppelt so groß wie im Mittelwert aller Berliner Bezirke.

Tabelle 30: Neukölln - Übersicht zu Prognoseräumen vor und nach der Modifikation

	Neukölln		**Mittelwert der Bezirke**	
Merkmal (EW-Stand: 31.12.2019)	**LOR-Systematik 2019**	**LOR-Systematik ab 2021**	LOR-Systematik 2019	LOR-Systematik ab 2021
Anzahl der PGR in Neukölln	4	4	5	5
PGR kleinste Einwohnerzahl (Min.)	37.507	37.507	34.826	39.624
Durchschnittliche Einwohnerzahl	82.476	82.476	64.666	66.317
PGR größte Einwohnerzahl (Max.)	166.157	166.157	102.268	98.338
Spannweite (Max. - Min.)	128.650	128.650	67.443	58.714

Quelle: eigene Zusammenstellung

Bezirksregionen in Neukölln

Im Zuge der Modifikation werden die Bezirksregionen Britz und Gropiusstadt aufgrund ihrer hohen Einwohnerzahl und im Sinne der gewünschten Stärkung der Hierarchie innerhalb der LOR-Systematik jeweils in zwei neue BZR geteilt. Die Spannweite der Bezirksregionen bleibt mit einer Differenz von 34.000 EW zwischen der größten Bezirksregion Rudow (BZR 084012) mit knapp 44.000 EW und der kleinsten BZR Buckow Nord (BZR 084011) mit 9.700 EW bestehen (siehe Tabelle 31).

Durch die Teilung der beiden Bezirksregionen Britz und Gropiusstadt verändert sich jedoch die durchschnittliche Einwohnerzahl und sinkt von 33.000 auf rund 27.500 EW.

Tabelle 31: Neukölln - Übersicht zu Bezirksregionen vor und nach der Modifikation

	Neukölln		Mittelwert der Bezirke	
Merkmal (EW-Stand: 31.12.2019)	**LOR-Systematik 2019**	**LOR-Systematik ab 2021**	LOR-Systematik 2019	LOR-Systematik ab 2021
Anzahl der BZR in Neukölln	10	12	12	12
BZR kleinste Einwohnerzahl (Min.)	9.653	9.653	13.725	13.235
Durchschnittliche Einwohnerzahl	32.990	27.492	30.027	28.091
BZR größte Einwohnerzahl (Max.)	43.926	43.926	46.031	43.947
Spannweite (Max. - Min.)	34.273	34.273	32.306	30.712

Quelle: eigene Zusammenstellung

Planungsräume in Neukölln

Mit der Modifikation der LOR-Systematik wurden durch Teilung und Zusammenlegung die Planungsräume in Neukölln im Hinblick auf die EW-Zahl an die Zielgrößen 1.000 bis 10.000 EW angeglichen. Die Anzahl der Planungsräume erhöhte sich infolgedessen von 40 auf 46 PLR. Infolge der zahlreichen Neuzuschnitte liegt die durchschnittliche Einwohnerzahl nach der neuen LOR-Systematik nur leicht über dem Durchschnitt der zwölf Bezirke. Der kleinste PLR ist fortan der PLR Ortolanweg mit etwa 1.300 EW. Der PLR Gropiusstadt Nord bildet den größten Planungsraum mit rund 12.500 EW (siehe Tabelle 32).

In der Bezirksregion Britz wurden zudem die Grenzverläufe der PLR Tempelhofer Weg, Mohriner Allee Nord und Britzer Garten angepasst. Die Änderungen ergeben sich infolge räumlicher Barrieren und funktionaler Zusammenhänge.

Tabelle 32: Neukölln - Übersicht zu Planungsräumen vor und nach der Modifikation

	Neukölln		Mittelwert der Bezirke	
Merkmal (EW-Stand: 31.12.2019)	**LOR-Systematik 2019**	**LOR-Systematik ab 2021**	LOR-Systematik 2019	LOR-Systematik ab 2021
Anzahl der PLR in Neukölln	40	46	37	45
PLR kleinste Einwohnerzahl (Min.)	478	1.247	851	826
Durchschnittliche Einwohnerzahl	8.248	7.172	8.610	6.988
PLR größte Einwohnerzahl (Max.)	27.602	12.546	22.435	13.816
Spannweite (Max. - Min.)	27.124	11.299	21.584	12.990

Quelle: eigene Zusammenstellung

6.3.9 Bezirk Treptow-Köpenick

Überblick

Der Bezirk Treptow-Köpenick hat auf allen Ebenen der LOR Modifikationen vorgenommen. Die Anzahl der Prognoseräume und Bezirksregionen bleibt dabei identisch. Die Verschiebung von einzelnen, meist unbewohnten Blöcken führte zu einer Arrondierung der Grenzverläufe auf Ebene der PGR und BZR. Auf der Ebene der Planungsräume steigt mit der neuen LOR-Systematik und vor allem aufgrund von Teilungen bestehender Teilräume die Zahl der PLR.

Abbildung 19 zeigt den neuen Zuschnitt der LOR in Treptow-Köpenick.

Abbildung 19: LOR in Treptow-Köpenick ab 2021

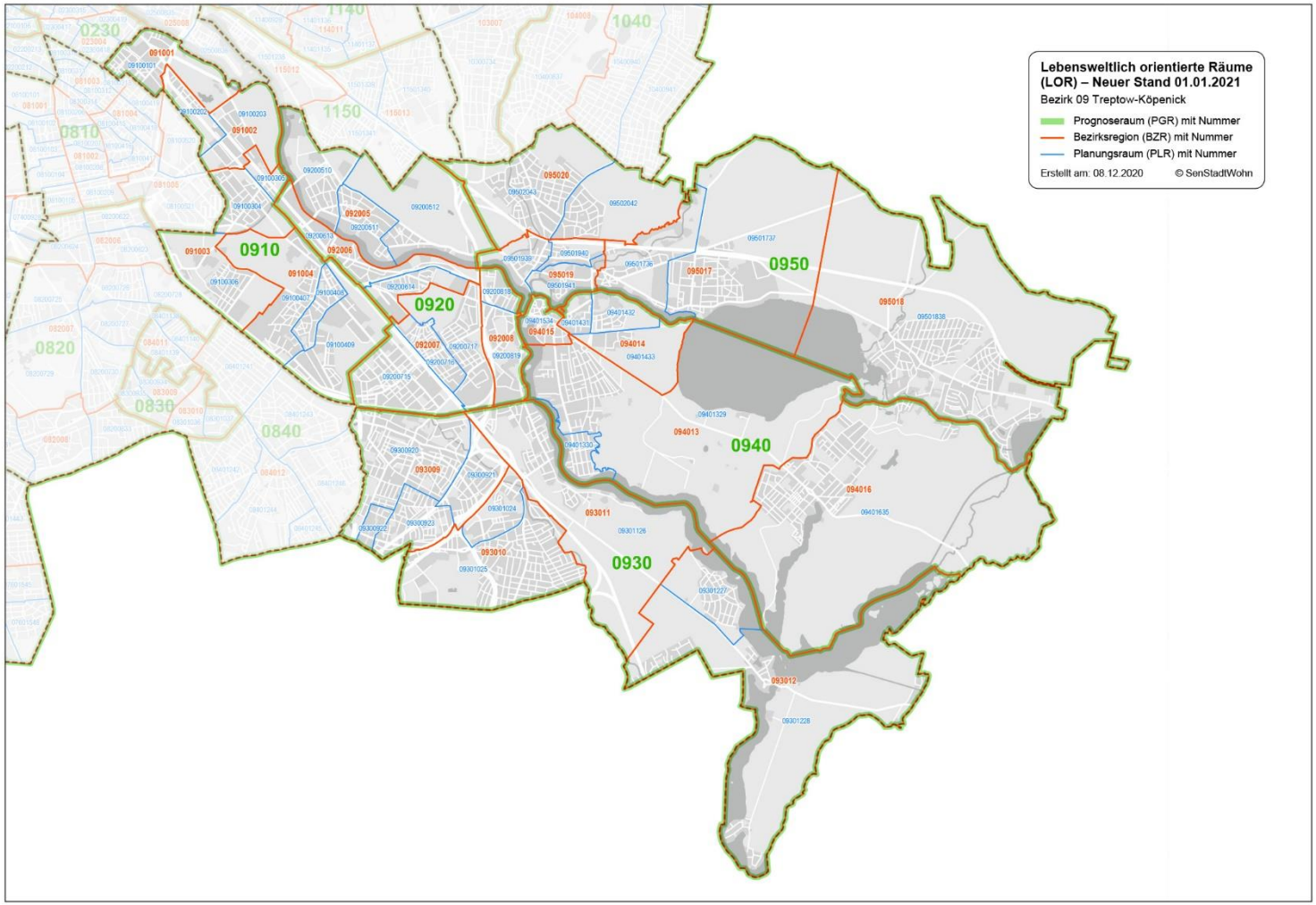

Quelle: eigene Darstellung

Prognoseräume in Treptow-Köpenick

Es bestehen weiterhin fünf Prognoseräume, die durchschnittlich 54.600 EW aufweisen (siehe Tabelle 33). Durch die Verschiebung von drei unbewohnten Blöcken wurde lediglich eine Arrondierung des Grenzverlaufs zwischen Treptow-Köpenick 2 und Treptow-Köpenick 1 erreicht. Der größte Prognoseraum ist Treptow-Köpenick 2 (PGR 0920) mit über 66.900 EW. Der Prognoseraum Treptow-Köpenick 4 (PGR 0940) weist mit rund 37.600 EW die geringste Einwohnerzahl auf.

Tabelle 33: Treptow-Köpenick - Übersicht zu Prognoseräumen vor und nach der Modifikation

	Treptow-Köpenick		**Mittelwert der Bezirke**	
Merkmal (EW-Stand: 31.12.2019)	**LOR-Systematik 2019**	**LOR-Systematik ab 2021**	**LOR-Systematik 2019**	**LOR-Systematik ab 2021**
Anzahl der PGR in Treptow-Köpenick	5	5	5	5
PGR kleinste Einwohnerzahl (Min.)	37.570	37.570	34.826	39.624
Durchschnittliche Einwohnerzahl	54.644	54.644	64.666	66.317
PGR größte Einwohnerzahl (Max.)	66.931	66.931	102.268	98.338
Spannweite (Max. - Min.)	29.361	29.361	67.443	58.714

Quelle: eigene Zusammenstellung

Bezirksregionen in Treptow-Köpenick

Im Bezirk Treptow-Köpenick gibt es weiterhin 20 Bezirksregionen mit durchschnittlich 13.700 Einwohnerinnen und Einwohnern. Es wurden keine Teilungen oder Zusammenlegungen vorgenommen. Lediglich die Verschiebung von drei unbewohnten Blöcken (122908, 122049, 122050) vom BZR Niederschöneweide zum BZR Johannistal Ost, sowie die Arrondierung des Blocks 126188 mit neun EW zur BZR Altglinicke führt zu einer Anpassung des Grenzverlaufs. Die größte Bezirksregion ist Altglinicke (BZR 093009) mit über 27.900 EW. Die BZR mit den wenigsten Einwohnerinnen und Einwohnern ist die Bezirksregion Schmöckwitz/Karolinenhof/Rauchfangswerder (BZR 093012). Dort lebten am 31.12.2019 rund 4.400 EW. Im Vergleich zu den anderen Berliner Bezirken weist Treptow-Köpenick überdurchschnittlich viele Bezirksregionen mit einer vergleichsweise geringen durchschnittlichen EW-Zahl auf (siehe Tabelle 34).

Tabelle 34: Treptow-Köpenick - Übersicht zu Bezirksregionen vor und nach der Modifikation

	Treptow-Köpenick		**Mittelwert der Bezirke**	
Merkmal (EW-Stand: 31.12.2019)	**LOR-Systematik 2019**	**LOR-Systematik ab 2021**	**LOR-Systematik 2019**	**LOR-Systematik ab 2021**
Anzahl der BZR in Treptow-Köpenick	20	20	12	12
BZR kleinste Einwohnerzahl (Min.)	4.424	4.424	13.725	13.235
Durchschnittliche Einwohnerzahl	13.661	13.661	30.027	28.091
BZR größte Einwohnerzahl (Max.)	27.925	27.914	46.031	43.947
Spannweite (Max. - Min.)	23.501	23.490	32.306	30.712

Quelle: eigene Zusammenstellung

Planungsräume in Treptow-Köpenick

Die Anzahl der PLR ist von 35 auf 43 PLR gestiegen. Die Teilung der bisherigen Planungsräume erfolgte entsprechend der Zielgrößen und erweitert die bisherige Hierarchie der LOR im gewünschten Sinne. In Treptow-Köpenick wiesen zahlreiche Planungsräume einen identischen Zuschnitt zu bestehenden Bezirksregion auf. Für die bisherigen PLR Baumschulenstraße, Bohnsdorf, Hirschgarten und Dammvorstadt konnte durch eine Teilung die hierarchische Struktur in der neuen LOR-Systematik stärkere Berücksichtigung finden.

Die Anpassungen der PLR durch Teilung und Zusammenlegung entsprechend der Zielgrößen, erhöhen zudem die Homogenität der PLR innerhalb des Bezirks, erleichtern aber auch Vergleiche über die Bezirksgrenzen hinaus.

Die Siedlung Kämmereiheide (PLR 09401432) stellt derzeit den kleinsten PLR mit rund 1.600 EW dar. Alt-Friedrichshagen (PLR 0 9501737) ist mit rund 14.600 EW der bevölkerungsstärkste PLR des Bezirks.

Im Rahmen der Modifikationen sind zudem mehrere PLR umbenannt worden, die keinen räumlichen Neuzuschnitt erfahren haben. Eine Liste mit allen neuen Namen befindet sich im Anhang.

Tabelle 35: Treptow-Köpenick - Übersicht zu Planungsräumen vor und nach der Modifikation

	Treptow-Köpenick		Mittelwert der Bezirke	
Merkmal (EW-Stand: 31.12.2019)	**LOR-Systematik 2019**	**LOR-Systematik ab 2021**	LOR-Systematik 2019	LOR-Systematik ab 2021
Anzahl der PLR in Treptow-Köpenick	35	43	37	45
PLR kleinste Einwohnerzahl (Min.)	68	1.567	851	826
Durchschnittliche Einwohnerzahl	7.806	6.354	8.610	6.988
PLR größte Einwohnerzahl (Max.)	17.021	14.553	22.435	13.816
Spannweite (Max. - Min.)	16.953	12.986	21.584	12.990

Quelle: eigene Zusammenstellung

6.3.10 Bezirk Marzahn-Hellersdorf

Überblick

In Marzahn-Hellersdorf gab es mehrere Modifikationen der Planungsräume, sowohl was Zuschnitte als auch Namensgebungen anbelangt. Mehrere einwohnerreiche Planungsräume wurden geteilt, sodass nun insgesamt mehr PLR im Bezirk existieren. In mehreren Fällen sind Namensänderungen von PLR erfolgt, die nicht von Neuzuschnitten betroffen waren. Die Ebenen der Bezirksregionen und Prognoseräume wurden nicht modifiziert.

Abbildung 20 zeigt den neuen Zuschnitt der LOR in Marzahn-Hellersdorf.

Abbildung 20: LOR in Marzahn-Hellersdorf ab 2021

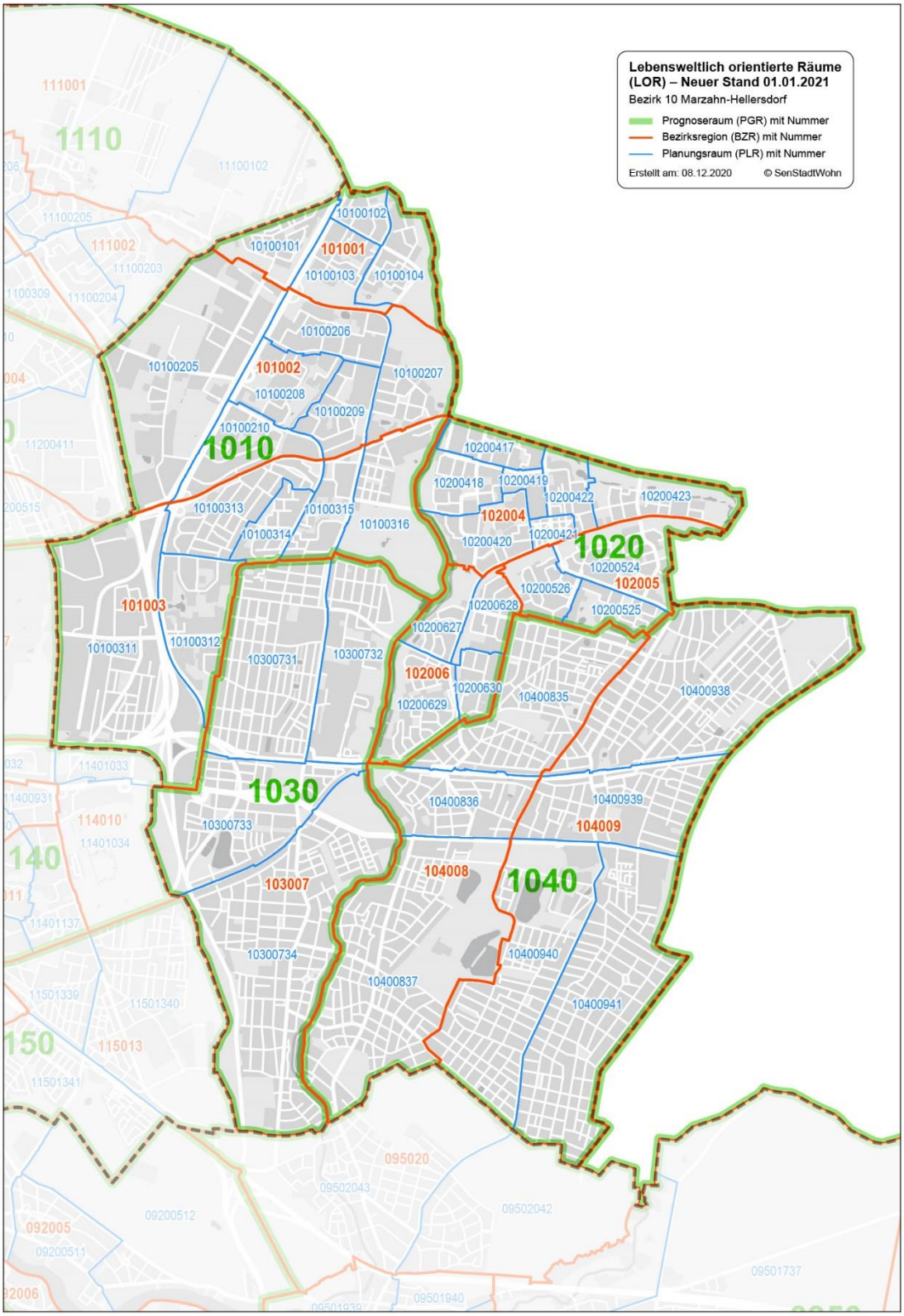

Quelle: eigene Darstellung

Prognoseräume in Marzahn-Hellersdorf

Der Bezirk Marzahn-Hellersdorf hat keine Änderungen an den Zuschnitten der Prognoseräume vorgenommen. Es bestehen weiterhin vier Prognoseräume, die durchschnittlich 67.500 EW aufweisen (siehe Tabelle 36). Der größte Prognoseraum ist Marzahn (PGR 1010) mit über 111.000 EW. Der PGR mit den wenigsten Einwohnerinnen und Einwohnern ist Biesdorf (PGR 1030). Dort lebten am 31.12.2019 rund 28.100 EW.

Tabelle 36: Marzahn-Hellersdorf - Übersicht zu Prognoseräumen vor und nach der Modifikation

	Marzahn-Hellersdorf		**Mittelwert der Bezirke**	
Merkmal (EW-Stand: 31.12.2019)	**LOR-Systematik 2019**	**LOR-Systematik ab 2021**	**LOR-Systematik 2019**	**LOR-Systematik ab 2021**
Anzahl der PGR in Marzahn-Hellersdorf	4	4	5	5
PGR kleinste Einwohnerzahl (Min.)	28.063	28.063	34.826	39.624
Durchschnittliche Einwohnerzahl	67.529	67.529	64.666	66.317
PGR größte Einwohnerzahl (Max.)	111.021	111.021	102.268	98.338
Spannweite (Max. - Min.)	82.958	82.958	67.443	58.714

Quelle: eigene Zusammenstellung

Bezirksregionen in Marzahn-Hellersdorf

Der Bezirk Marzahn-Hellersdorf hat keine Änderungen an den Zuschnitten der Bezirksregionen vorgenommen. Es gibt weiterhin neun BZR, die durchschnittlich 30.000 EW aufweisen, mehr als der Durchschnitt der Bezirke nach der Modifikation (siehe Tabelle 37). Die größte Bezirksregion ist Marzahn Mitte (BZR 101002) mit über 48.000 EW. Die kleinste BZR, mit Bezug auf EW, ist Kaulsdorf (BZR 104008). Dort lebten Ende 2019 19.400 Personen.

Tabelle 37: Marzahn-Hellersdorf - Übersicht zu Bezirksregionen vor und nach der Modifikation

	Marzahn-Hellersdorf		Mittelwert der Bezirke	
Merkmal (EW-Stand: 31.12.2019)	**LOR-Systematik 2019**	**LOR-Systematik ab 2021**	LOR-Systematik 2019	LOR-Systematik ab 2021
Anzahl der BZR in Marzahn-Hellersdorf	9	9	12	12
BZR kleinste Einwohnerzahl (Min.)	19.408	19.408	13.725	13.235
Durchschnittliche Einwohnerzahl	30.013	30.013	30.027	28.091
BZR größte Einwohnerzahl (Max.)	48.008	48.008	46.031	43.947
Spannweite (Max. - Min.)	28.600	28.600	32.306	30.712

Quelle: eigene Zusammenstellung

Planungsräume in Marzahn-Hellersdorf

Mit der neuen LOR Systematik ab 2021 gibt es 41 Planungsräume im Bezirk Marzahn-Hellersdorf, acht mehr als zuvor. Durch die Teilung von fünf bisherigen PLR in mehrere neue PLR ist die durchschnittliche EW-Zahl deutlich gesunken und liegt mit 6.600 EW etwas unter dem Durchschnitt der Bezirke (siehe Tabelle 38).

Der PLR mit den wenigsten Einwohnerinnen und Einwohnern ist Gewerbegebiet Bitterfelder Straße (PLR 10100205). Dort lebten Ende 2019 etwas über 1.300 Personen. Der einwohnerreichste PLR des Bezirks ist mit der LOR-Systematik ab 2021 Springpfuhl (PLR 10100312), mit 14.600 EW.

Für den Planungsraum-Neuzuschnitt des alten PLR Gut Hellersdorf (alt: 10200420) in u. a. Kyritzer Str. (PLR 10200418) und Havelländer Ring (10200419) wird die Teilung zweier Blöcke notwendig. Die absehbare Bebauung, entsprechend des Bebauungsplans 10 - 44, begründet die ausnahmsweise Teilung im Rahmen der Modifikation. Um den gewünschten PLR-Zuschnitt zu erreichen, müssen die Blöcke 194624 und 194628 geteilt werden. Die Teilung/Neuzuschnitt in vier Blöcke wird durch den Geoservice des AfS realisiert.

Im Rahmen der Modifikationen sind zudem mehrere PLR umbenannt worden, die keinen räumlichen Neuzuschnitt erfahren haben. Eine Liste mit allen neuen Namen befindet sich im Anhang.

Tabelle 38: Marzahn-Hellersdorf - Übersicht zu Planungsräumen vor und nach der Modifikation

	Marzahn-Hellersdorf		Mittelwert der Bezirke	
Merkmal (EW-Stand: 31.12.2019)	**LOR-Systematik 2019**	**LOR-Systematik ab 2021**	LOR-Systematik 2019	LOR-

				Systema-tik ab 2021
Anzahl der PLR in Marzahn-Hellers-dorf	33	41	37	45
PLR kleinste Einwohnerzahl (Min.)	1.308	1.308	851	826
Durchschnittliche Einwohnerzahl	8.185	6.588	8.610	6.988
PLR größte Einwohnerzahl (Max.)	18.471	14.605	22.435	13.816
Spannweite (Max. - Min.)	17.163	13.297	21.584	12.990

Quelle: eigene Zusammenstellung

6.3.11 Bezirk Lichtenberg

Überblick

In Lichtenberg gab es ausschließlich Modifikationen der Planungsräume. Die Ebenen der Bezirksregionen und Prognoseräume wurden nicht modifiziert. Mehrere einwohnerreiche Planungsräume wurden geteilt, sodass nun insgesamt mehr PLR im Bezirk existieren.

Abbildung 21 zeigt den neuen Zuschnitt der LOR in Lichtenberg.

Abbildung 21: LOR in Lichtenberg ab 2021

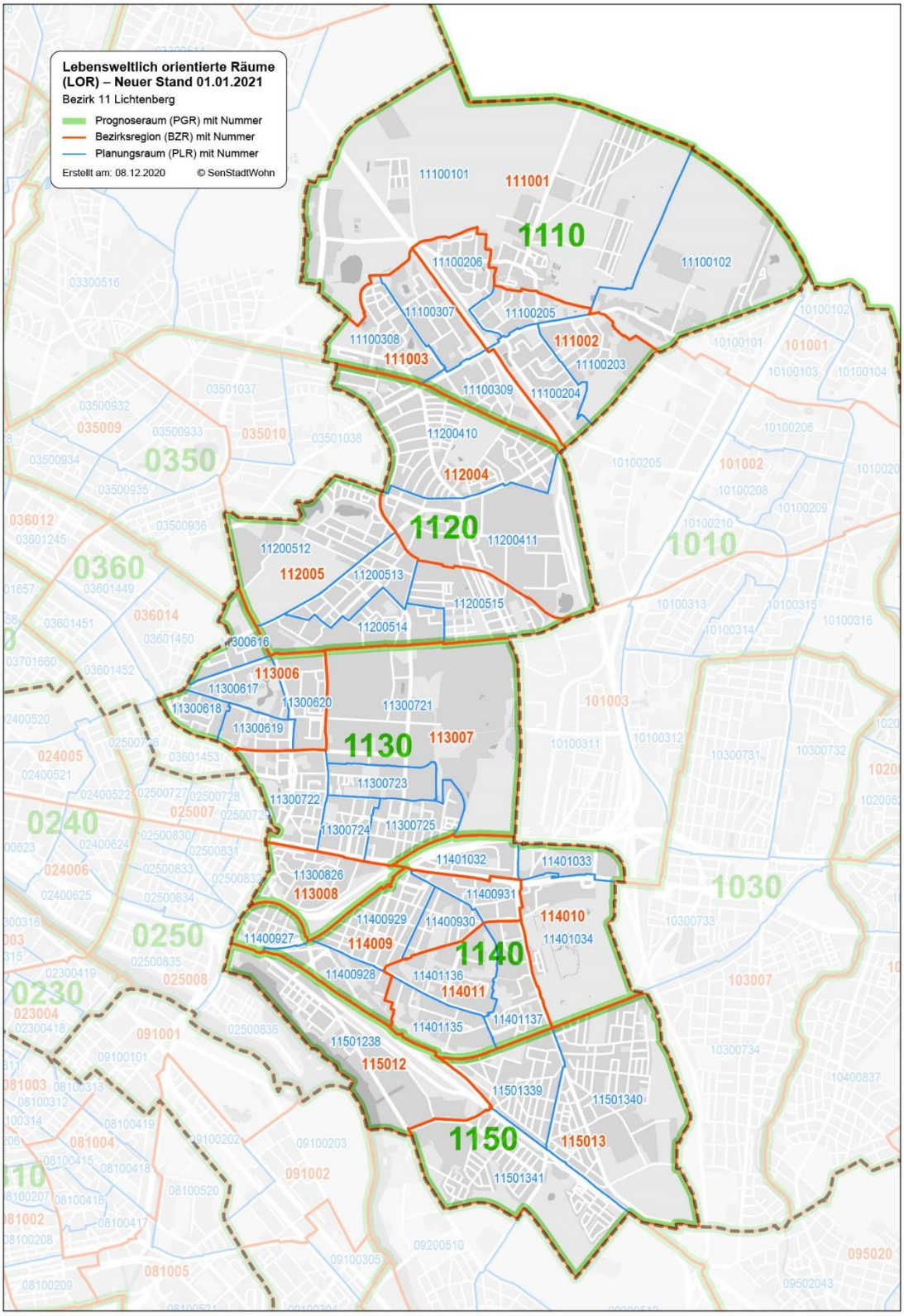

Quelle: eigene Darstellung

Prognoseräume in Lichtenberg

Der Bezirk Lichtenberg hat keine Änderungen an den Zuschnitten der Prognoseräume vorgenommen. Es bestehen weiterhin fünf Prognoseräume, die durchschnittlich 58.800 EW aufweisen und damit kleiner sind als im Durchschnitt der Bezirke (siehe Tabelle 39). Der größte Prognoseraum ist Lichtenberg Nord (PGR 1130) mit fast 76.000 EW. Der PGR mit den wenigsten Einwohnerinnen und Einwohnern ist Lichtenberg Süd (PGR 1150). Dort lebten am 31.12.2019 rund 32.200 EW.

Tabelle 39: Lichtenberg - Übersicht zu Prognoseräumen vor und nach der Modifikation

	Lichtenberg		Mittelwert der Bezirke	
Merkmal (EW-Stand: 31.12.2019)	**LOR-Systematik 2019**	**LOR-Systematik ab 2021**	LOR-Systematik 2019	LOR-Systematik ab 2021
Anzahl der PGR in Lichtenberg	5	5	5	5
PGR kleinste Einwohnerzahl (Min.)	32.248	32.248	34.826	39.624
Durchschnittliche Einwohnerzahl	58.840	58.840	64.666	66.317
PGR größte Einwohnerzahl (Max.)	75.832	75.832	102.268	98.338
Spannweite (Max. - Min.)	43.584	43.584	67.443	58.714

Quelle: eigene Zusammenstellung

Bezirksregionen in Lichtenberg

Der Bezirk Lichtenberg hat keine Änderungen an den Zuschnitten der Bezirksregionen vorgenommen. Es gibt weiterhin 13 BZR, die durchschnittlich 22.600 EW aufweisen, weniger als der Durchschnitt der Bezirke nach der Modifikation (siehe Tabelle 40). Die größte Bezirksregion ist Fennpfuhl (BZR 113006) mit über 34.000 EW. Die kleinste BZR, mit Bezug auf EW, ist Rummelsburger Bucht (BZR 115012). Dort lebten Ende 2019 rund 4.300 Personen.

Die BZR Rummelsburger Bucht (BZR 115012) stellt im hierarchischen System der LOR im Bezirk Lichtenberg eine Ausnahme dar. Erfüllt die LOR-Systematik in diesem Bezirk sonst den Anspruch der 1:n-Beziehung (siehe Kriterien der Modifikation), so besitzt die BZR Rummelsburger Bucht (BZR 115012) auch weiterhin nur einen zugehörigen Planungsraum (Rummelsburg, PLR 11501238).

Tabelle 40: Lichtenberg - Übersicht zu Bezirksregionen vor und nach der Modifikation

	Lichtenberg		Mittelwert der Bezirke	
Merkmal (EW-Stand: 31.12.2019)	**LOR-Systematik 2019**	**LOR-Systematik ab 2021**	LOR-Systematik 2019	LOR-Systematik ab 2021
Anzahl der BZR in Lichtenberg	13	13	12	12
BZR kleinste Einwohnerzahl (Min.)	4.254	4.254	13.725	13.235
Durchschnittliche Einwohnerzahl	22.631	22.631	30.027	28.091
BZR größte Einwohnerzahl (Max.)	34.074	34.074	46.031	43.947
Spannweite (Max. - Min.)	29.820	29.820	32.306	30.712

Quelle: eigene Zusammenstellung

Planungsräume in Lichtenberg

Mit der neuen LOR Systematik ab 2021 gibt es 41 Planungsräume im Bezirk Lichtenberg, neun mehr als zuvor. Durch das Zusammenlegen von zwei und die Teilung von vier bisherigen PLR in mehrere neue PLR ist die durchschnittliche EW-Zahl um über 2.000 Personen gesunken und liegt mit 7.200 EW etwas über dem Durchschnitt der Bezirke (siehe Tabelle 41).

Der PLR mit den wenigsten Einwohnerinnen und Einwohnern ist Dorf Falkenberg (PLR 11100102). Dort lebten Ende 2019 etwa 1.900 Personen. Der einwohnerreichste PLR des Bezirks ist mit der LOR-Systematik ab 2021 Weitlingkiez (PLR 11400929), mit 16.200 EW. Damit ist dieser PLR der einwohnerreichste PLR Berlins und liegt nur ausnahmsweise über der definierten Obergrenze (siehe Kriterien der Modifikation). Der PLR Weitlingkiez (PLR 11400929) ist aus dem bisherigen PLR Weitlingstraße (PLR alt 11040926) hervorgegangen, der in vier neue PLR geteilt wurde. Auf eine kleinteiligere Teilung zugunsten geringerer EW-Zahlen wurde bewusst verzichtet, um den Weitlingkiez als bekanntes und etabliertes Ortsteilzentrum abbildbar zu machen.

Tabelle 41: Lichtenberg - Übersicht zu Planungsräumen vor und nach der Modifikation

	Lichtenberg		Mittelwert der Bezirke	
Merkmal (EW-Stand: 31.12.2019)	**LOR-Systematik 2019**	**LOR-Systematik ab 2021**	LOR-Systematik 2019	LOR-Systematik ab 2021
Anzahl der PLR in Lichtenberg	32	41	37	45
PLR kleinste Einwohnerzahl (Min.)	644	1.870	851	826
Durchschnittliche Einwohnerzahl	9.194	7.176	8.610	6.988
PLR größte Einwohnerzahl (Max.)	29.596	16.172	22.435	13.816
Spannweite (Max. - Min.)	28.952	14.302	21.584	12.990

Quelle: eigene Zusammenstellung

6.3.12 Bezirk Reinickendorf

Überblick

Der Bezirk Reinickendorf hat auf allen Ebenen der LOR Modifikationen vorgenommen. Die Anpassungen erhöhen dadurch die Homogenität der Prognoseräume und Bezirksregionen innerhalb des Bezirks und tragen zur Vervollständigung und Vereinheitlichung der LOR-Systematik bei. Neben den angewandten Prinzipien der Teilung und Zusammenlegung führen Verschiebung von einzelnen Blöcken zu einer Arrondierung der Grenzverläufe auf Ebene der PGR und BZR. Auf der Ebene der Planungsräume gibt es mit der LOR-Systematik ab 2021 sechs PLR mehr als zuvor. Dies erfolgt zumeist durch die Teilung bisher bestehender Räume.

Abbildung 22 zeigt den neuen Zuschnitt der LOR in Reinickendorf.

Abbildung 22: LOR in Reinickendorf ab 2021

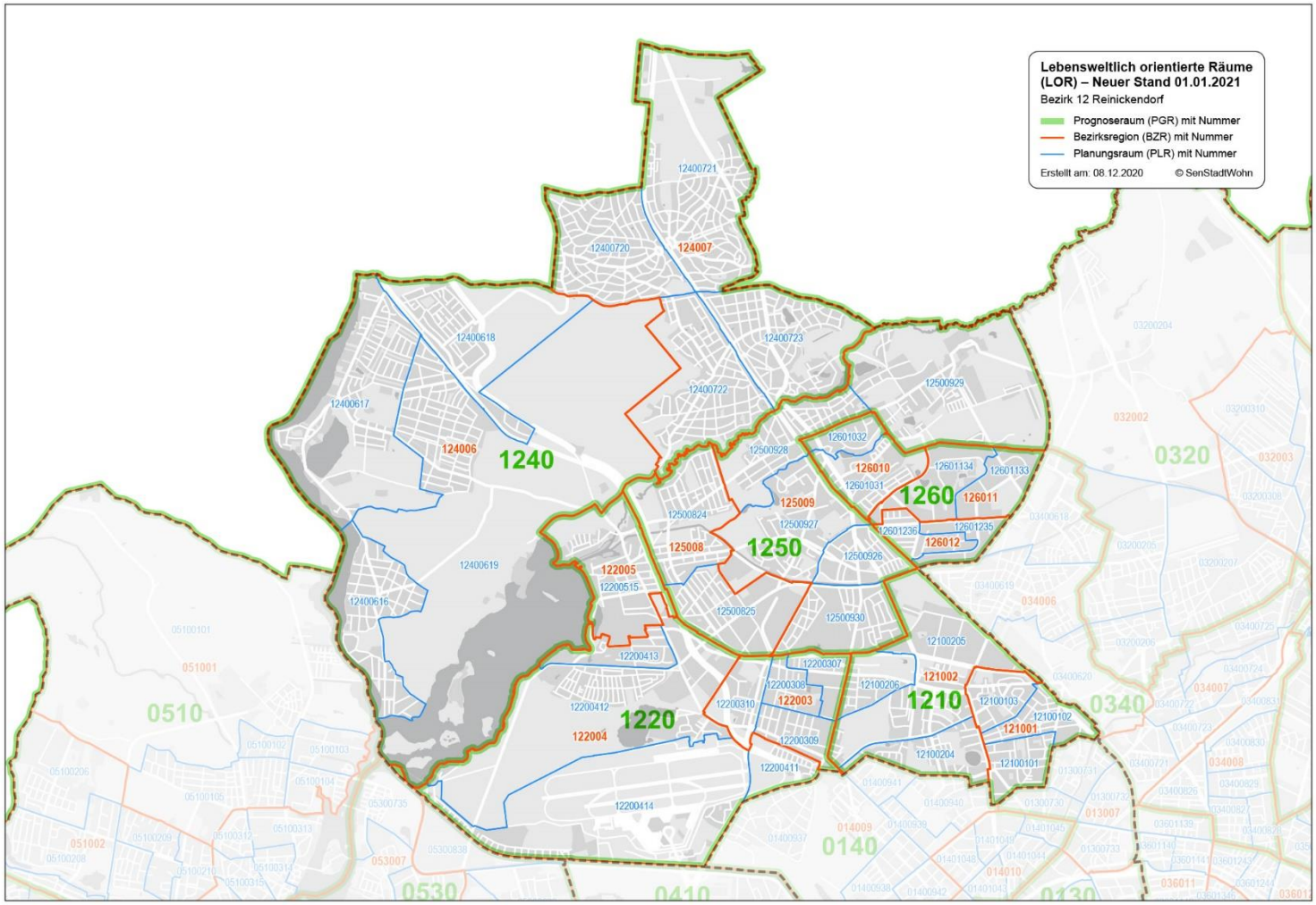

Quelle: eigene Darstellung

Prognoseräume in Reinickendorf

Der Bezirk Reinickendorf hat im Rahmen der Modifikation auch Anpassungen auf Ebene der Prognoseräume vorgenommen und durch Teilung und Zusammenlegung neu zugeschnitten. Im Ergebnis stehen fünf Prognoseräume mit durchschnittlich rund 53.300 Einwohnerinnen und Einwohnern. Die Anpassungen erhöhen die Homogenität der PGR innerhalb des Bezirks und tragen zur Vervollständigung und Vereinheitlichung der LOR-Systematik bei. Zudem ermöglichen die neuen PGR auch aus sozialräumlicher Perspektive homogenere Raumeinheiten. Darüber hinaus kommt es zu einer Veränderung des Grenzverlaufs zwischen den PGR Grüner Norden (PGR 1240) und Tegel (PGR 1220) durch die Zusammenlegung der PLR Heiligensee und Teilen des Tegeler Forst.

Die Spannweite der EW-Zahlen zwischen den einzelnen PGR ist durch die Modifikation um knapp 10.000 EW deutlich gesunken (siehe Tabelle 42). Der größte Prognoseraum ist der neue PGR Grüner Norden (PGR 1240), der aus der Fusionierung der PGR Heiligensee/Konradshöhe und PGR Frohnau/Hermsdorf entstanden ist. Dort lebten am 31.12.2019 rund 57.800 EW. Zuvor lag die Zahl der Einwohnerinnen und Einwohner beider PGR deutlich unter dem Mittelwert der Bezirke und die Ebene der PGR und BZR bildeten identische Räume. Im Zuge der Modifikation wurde damit durch den Neuzuschnitt das Ziel einer stärkeren Hierarchisierung der LOR-Systematik umgesetzt. Der PGR mit den wenigsten Einwohnerinnen und Einwohnern ist Wittenau/Borsigwalde (PGR 1250). Durch die Teilung des ehemaligen PGR Waidmannslust weist der neu entstandene PGR Wittenau/Borsigwalde rund 48.100 EW auf.

Tabelle 42: Reinickendorf - Übersicht zu Prognoseräumen vor und nach der Modifikation

	Reinickendorf		**Mittelwert der Bezirke**	
Merkmal (EW-Stand: 31.12.2019)	**LOR-Systematik 2019**	**LOR-Systematik ab 2021**	**LOR-Systematik 2019**	**LOR-Systematik ab 2021**
Anzahl der PGR in Reinickendorf	5	5	5	5
PGR kleinste Einwohnerzahl (Min.)	24.104	48.081	34.826	39.624
Durchschnittliche Einwohnerzahl	53.282	53.282	64.666	66.317
PGR größte Einwohnerzahl (Max.)	97.734	57.794	102.268	98.338
Spannweite (Max. - Min.)	73.630	9.713	67.443	58.714

Quelle: eigene Zusammenstellung

Bezirksregionen in Reinickendorf

Die Anzahl der Bezirksregionen hat sich von elf auf zwölf BZR mit durchschnittlich je 22.200 Einwohnerinnen und Einwohner erhöht. Die Teilung der nach der LOR-Systematik 2019 einwohnerstärksten Bezirksregion MV 1 - Märkisches Viertel (rund 40.500 EW) in die beiden BZR MV Süd (BZR 126012) und MV Nord (BZR 126011) führte zu einer Angleichung des Einwohnerdurchschnitts auf BZR-Ebene und trägt aus sozialräumlicher Perspektive zu homogeneren Raumeinheiten bei. Eine Anpassung des Grenzverlaufs zwischen der BZR West 1 - Tegel-Süd/Flughafensee (122004) und der BZR West 4 - Auguste-Viktoria-Allee (122003) erfolgte entlang der Scharnweberstraße, die bislang eine städtebauliche Barriere innerhalb der BZR und des PLR Scharnweberstraße darstellte.

Die einwohnerstärkste Bezirksregion stellt nun Nord 1 - Frohnau/Hermsdorf (BZR 124007) mit rund 33.400 EW dar. Die Rollbergesiedlung (BZR 126010) ist mit 9.300 EW die BZR, mit den wenigsten Bewohnerinnen und Bewohnern im Bezirk.

Tabelle 43: Reinickendorf - Übersicht zu Bezirksregionen vor und nach der Modifikation

	Reinickendorf		**Mittelwert der Bezirke**	
Merkmal (EW-Stand: 31.12.2019)	**LOR-Systematik 2019**	**LOR-Systematik ab 2021**	**LOR-Systematik 2019**	**LOR-Systematik ab 2021**
Anzahl der BZR in Reinickendorf	11	12	12	12
BZR kleinste Einwohnerzahl (Min.)	9.274	9.274	13.725	13.235
Durchschnittliche Einwohnerzahl	24.219	22.201	30.027	28.091
BZR größte Einwohnerzahl (Max.)	40.379	33.421	46.031	43.947
Spannweite (Max. - Min.)	31.105	24.147	32.306	30.712

Quelle: eigene Zusammenstellung

Planungsräume in Reinickendorf

Die Anzahl der Planungsräume im Bezirk Reinickendorf hat sich von 30 auf 36 PLR erhöht. Die durchschnittliche Einwohnerzahl ist im Rahmen der Modifikation auf 7.400 EW gesunken und liegt leicht über dem Mittelwert der Berliner Bezirke (siehe Tabelle 44). Fünf Planungsräume wurden aufgrund der hohen Einwohnerzahl oder prognostizierter Überschreitung der Einwohnergrenze durch zukünftigen Wohnungsneubau bis 2030 geteilt. Der PLR Tegeler Forst wurde aufgrund der geringen Einwohnerzahl aufgelöst und ging in den PLR Alt-Tegel (PLR 12200515) und den PLR Heiligensee (PLR 12400619) auf. Mit Fokus auf sozialräumliche Kriterien gab es im PLR Konradshöhe/Tegelort (PLR 12400616) eine Anpassung des Grenzverlaufs durch eine Blockverschiebung (089223). Hier befindet sich eine Grundschule dessen Einzugsgebiet ausschließlich im PLR Konradshöhe/Tegelort liegt.

Den bevölkerungsstärksten PLR bildet Märkisches Zentrum (PLR 12601134) mit über 14.800 EW. Der PLR Schumacher-Quartier (PLR 12200411), in dem zukünftig mit weiterem Wohnungsneubau zu rechnen ist, stellt derzeit den kleinsten PLR mit knapp 400 EW dar.

Tabelle 44: Reinickendorf - Übersicht zu Planungsräumen vor und nach der Modifikation

	Reinickendorf		**Mittelwert der Bezirke**	
Merkmal (EW-Stand: 31.12.2019)	**LOR-Systematik 2019**	**LOR-Systematik ab 2021**	**LOR-Systematik 2019**	**LOR-Systematik ab 2021**
Anzahl der PLR in Reinickendorf	30	36	37	45
PLR kleinste Einwohnerzahl (Min.)	269	360	851	826
Durchschnittliche Einwohnerzahl	8.880	7.400	8.610	6.988
PLR größte Einwohnerzahl (Max.)	18.100	14.827	22.435	13.816
Spannweite (Max. - Min.)	17.831	14.467	21.584	12.990

Quelle: eigene Zusammenstellung

Anhang

Danksagung

Die Modifikation der Lebensweltlich orientierten Räume (LOR) ist ein Gesamt-Berliner Projekt – betrifft es doch die ganze Stadt. Alle Anwenderinnen und Anwender können die neue Systematik für Ihre Zwecke nutzen. Insbesondere die öffentliche Verwaltung verwendet die LOR häufig als Planungsgrundlage für fachliche und politische Entscheidungen. Entsprechend hoch waren das Interesse und die Bereitschaft, sich in einen aufwändigen Prozess einzubringen. Mehrere Dutzend Expertinnen und Experten aus über 20 Verwaltungseinheiten, sowohl von der bezirklichen als auch gesamtstädtischen Ebene, haben sich intensiv beteiligt – sei es in gemeinsamen Abstimmungen oder in hausinternen Diskussionen. Das große Engagement Aller hat zu einem reibungslosen, Ebenen-übergreifenden Prozess beigetragen und den Erfolg der Modifikationen ermöglicht. Den Beteiligten gilt ein großer Dank für die gute zielführende Kommunikation und insbesondere für die hohe Einsatz- und Lösungsbereitschaft. Dies gilt umso mehr, als dass ein großer und wichtiger Teil des Projekts in die Zeit der Corona-Pandemie fiel, in der andere Herausforderungen stärker im Fokus standen und das gewohnte Arbeiten nur eingeschränkt möglich war.

Tabellarische Übersicht der neuen LOR-Systematik ab 2021

PGR ID	PGR Name	BZR ID	BZR Name	PLR ID	PLR Name	EW 31.12.19
			01 Mitte			
0110	**Zentrum**	011001	**Tiergarten Süd**	01100101	Stülerstraße	3.445
				01100102	Großer Tiergarten	1.755
				01100103	Lützowstraße	5.159
				01100104	Körnerstraße	4.626
			Tiergarten Süd - gesamt			**14.985**
		011002	**Regierungsviertel**	01100205	Wilhelmstraße	2.456
				01100206	Unter den Linden	1.825
				01100207	Leipziger Straße	8.461
			Regierungsviertel - gesamt			**12.742**
		011003	**Alexanderplatz**	01100308	Charitéviertel	6.910
				01100309	Oranienburger Straße	12.540
				01100310	Alexanderplatzviertel	10.011
				01100311	Karl-Marx-Allee	8.813
				01100312	Heine-Viertel West	8.778
				01100313	Heine-Viertel Ost	10.831
			Alexanderplatz - gesamt			**57.883**
		011004	**Brunnenstraße Süd**	01100414	Nordbahnhof	5.198
				01100415	Invalidenstraße	13.002
				01100416	Arkonaplatz	13.640
			Brunnenstraße Süd - gesamt			**31.840**
	Zentrum - gesamt					**117.450**
0120	**Moabit**	012005	**Moabit West**	01200517	Huttenkiez	3.819
				01200518	Beusselkiez	6.809
				01200519	Emdener Straße	9.211
				01200520	Bremer Straße	9.612
				01200521	Zwinglistraße	5.365
				01200522	Elberfelder Straße	11.459
			Moabit West - gesamt			**46.275**
		012006	**Moabit Ost**	01200623	Stephankiez	11.048
				01200624	Heidestraße	3.580
				01200625	Lübecker Straße	7.150

PGR ID	PGR Name	BZR ID	BZR Name	PLR ID	PLR Name	EW 31.12.19
				01200626	Thomasiusstraße	6.081
				01200627	Zillesiedlung	3.316
				01200628	Lüneburger Straße	3.045
				01200629	Hansaviertel	5.822
			Moabit Ost - gesamt			**40.042**
	Moabit - gesamt					**86.317**
0130	Gesundbrunnen	013007	Osloer Straße	01300730	Drontheimer Straße	8.184
				01300731	Koloniestraße	8.795
				01300732	Soldiner Straße	9.977
				01300733	Gesundbrunnen	11.853
			Osloer Straße - gesamt			**38.809**
		013008	Brunnenstraße Nord	01300834	Brunnenstraße	14.303
				01300835	Humboldthain Süd	10.509
				01300836	Humboldthain Nordwest	14.657
			Brunnenstraße Nord - gesamt			**39.469**
	Gesundbrunnen - gesamt					**78.278**
0140	Wedding	014009	Parkviertel	01400937	Afrikanische Straße	10.949
				01400938	Kameruner Straße	9.980
				01400939	Glasgower Straße	5.949
				01400940	Schillerpark	6.796
				01400941	Londoner Straße	3.871
				01400942	Westliche Müllerstraße	8.809
			Parkviertel - gesamt			**46.354**
		014010	Wedding Zentrum	01401043	Antonstraße	7.853
				01401044	Uferstraße	10.395
				01401045	Schwedenstraße	5.855
				01401046	Nordufer	9.057
				01401047	Sparrplatz	8.131
				01401048	Leopoldplatz	9.202
				01401049	Schulstraße	6.856
			Wedding Zentrum - gesamt			**57.349**
	Wedding - gesamt					**103.703**
02 Friedrichshain-Kreuzberg						

PGR ID	PGR Name	BZR ID	BZR Name	PLR ID	PLR Name	EW 31.12.19
0210	Kreuzberg Nord	021001	Südliche Friedrichstadt	02100101	Askanischer Platz	6.482
				02100102	Mehringplatz	8.494
				02100103	Am Berlin Museum	5.276
				02100104	Moritzplatz	5.553
				02100105	Prinzenstraße	9.630
				02100106	Wassertorplatz	5.095
			Südliche Friedrichstadt - gesamt			**40.530**
	Kreuzberg Nord – gesamt					**40.530**
0220	Kreuzberg Süd	022002	Tempelhofer Vorstadt	02200207	Gleisdreieck	1.860
				02200208	Rathaus Yorckstraße	6.037
				02200209	Viktoriapark	10.965
				02200210	Urbanstraße	12.657
				02200211	Chamissokiez	15.140
				02200212	Graefekiez Süd	8.657
				02200213	Graefekiez Nord	10.331
			Tempelhofer Vorstadt - gesamt			**65.647**
	Kreuzberg Süd - gesamt					**65.647**
0230	Kreuzberg Ost	023003	Nördliche Luisenstadt	02300314	Oranienplatz	7.695
				02300315	Lausitzer Platz	8.869
				02300316	Köpenicker Straße	4.227
			Nördliche Luisenstadt - gesamt			**20.791**
		023004	Südliche Luisenstadt	02300417	Reichenberger Straße West	8.515
				02300418	Reichenberger Straße Ost	7.851
				02300419	Wrangelkiez	11.017
			Südliche Luisenstadt - gesamt			**27.383**
	Kreuzberg Ost - gesamt					**48.174**
0240	Friedrichshain West	024005	Karl-Marx-Allee Nord	02400520	Barnimkiez	5.427
				02400521	Friedenstraße	7.558
				02400522	Richard-Sorge-Viertel	11.351
			Karl-Marx-Allee Nord - gesamt			**24.336**
		024006	Karl-Marx-Allee Süd	02400623	Andreasviertel	13.406
				02400624	Weberwiese	11.314
				02400625	Wriezener Bahnhof	1.160

PGR ID	PGR Name	BZR ID	BZR Name	PLR ID	PLR Name	EW 31.12.19
			Karl-Marx-Allee Süd - gesamt			**25.880**
	Friedrichshain West - gesamt					**50.216**
0250	**Friedrichshain Ost**	025007	**Frankfurter Allee Nord**	02500726	Hausburgviertel	9.268
				02500727	Forckenbeckplatz	6.544
				02500728	Samariterviertel	9.877
				02500729	Pettenkofer Straße	5.478
			Frankfurter Allee Nord - gesamt			**31.167**
		025008	**Frankfurter Allee Süd FK**	02500830	Niederbarnimstraße	3.891
				02500831	Wismarplatz	7.938
				02500832	Traveplatz	8.807
				02500833	Boxhagener Platz	10.199
				02500834	Revaler Straße	11.426
				02500835	Stralauer Kiez	7.719
				02500836	Stralauer Halbinsel	4.672
			Frankfurter Allee Süd FK - gesamt			**54.652**
	Friedrichshain Ost - gesamt					**85.819**
			03 Pankow			
0310	**Buch**	031001	**Buch**	03100101	Bucher Forst	4.454
				03100102	Klinikum Buch	3.218
				03100103	Karower Chaussee	9.422
			Buch - gesamt			**17.094**
	Buch - gesamt					**17.094**
0320	**Nördliches Pankow**	032002	**Blankenfelde/ Niederschönhau-sen**	03200204	Blankenfelde	2.064
				03200205	Uhlandstraße	8.660
				03200206	Pastor-Niemöller-Platz	6.510
				03200207	Herthaplatz	11.472
			Blankenfelde/Niederschönhausen - gesamt			**28.706**
		032003	**Buchholz**	03200308	Nisbléstraße	5.167
				03200309	Eddastraße	5.066
				03200310	Krugpfuhl	8.026
			Buchholz - gesamt			**18.259**
	Nördliches Pankow - gesamt					**46.965**
0330		033004	**Karow**	03300411	Karow Nord	11.444

PGR ID	PGR Name	BZR ID	BZR Name	PLR ID	PLR Name	EW 31.12.19
	Nördliches Weißensee			03300412	Karow Bahnhof	5.116
				03300413	Karow Ost	3.119
			Karow - gesamt			**19.679**
		033005	**Blankenburg/ Heinersdorf/ Märchenland**	03300514	Blankenburg	6.833
				03300515	Blankenburger Süden	42
				03300516	Heinersdorf	7.869
				03300517	Märchenland	1.120
			Blankenburg/Heinersdorf/Märchenland - gesamt			**15.864**
	Nördliches Weißensee - gesamt					**35.543**
0340	**Südliches Pankow**	034006	**Schönholz/ Wilhelmsruh/ Rosenthal**	03400618	Rosenthal	4.551
				03400619	Wilhelmsruh	10.354
				03400620	Schönholz	3.424
			Schönholz/Wilhelmsruh/Rosenthal - gesamt			**18.329**
		034007	**Pankow Zentrum**	03400721	Florakiez	11.465
				03400722	Parkstraße	3.621
				03400723	Garbátyplatz	7.147
				03400724	Wolfshagener Straße	7.541
				03400725	Schlosspark	7.250
			Pankow Zentrum - gesamt			**37.024**
		034008	**Pankow Süd**	03400826	Tiroler Viertel	6.590
				03400827	Trelleborger Viertel	9.642
				03400828	Spiekermann Straße	4.150
				03400829	Arnold-Zweig-Straße	5.623
				03400830	Kissingenviertel	9.340
				03400831	Pankower Tor	
			Pankow Süd - gesamt			**35.345**
	Südliches Pankow - gesamt					**90.698**
0350	**Südliches Weißensee**	035009	**Weißensee**	03500932	Bühringstraße	5.140
				03500933	Weißer See	7.517
				03500934	Weißenseer Spitze	9.762
				03500935	Behaimstraße	6.287
				03500936	Komponistenviertel Weißensee	9.822
			Weißensee - gesamt			**38.528**

PGR ID	PGR Name	BZR ID	BZR Name	PLR ID	PLR Name	EW 31.12.19
		035010	**Weißensee Ost**	03501037	Rathaus Weißensee	8.194
				03501038	Hansastraße	7.310
			Weißensee Ost - gesamt			**15.504**
	Südliches Weißensee - gesamt					**54.032**
0360	**Nördlicher Prenzlauer Berg**	036011	**Prenzlauer Berg Nordwest**	03601139	Norweger Viertel	3.749
				03601140	Malmöer Straße	5.694
				03601141	Arnimplatz	6.496
				03601142	Falkplatz	10.597
			Prenzlauer Berg Nordwest - gesamt			**26.536**
		036012	**Prenzlauer Berg Nord**	03601243	Rodenbergstraße	7.022
				03601244	Humannplatz	7.619
				03601245	Ostseestraße	12.803
			Prenzlauer Berg Nord - gesamt			**27.444**
		036013	**Helmholtzplatz**	03601346	Gethsemanekirche	5.503
				03601347	Helmholtzplatz	9.613
				03601348	Senefelderstraße	7.641
			Helmholtzplatz - gesamt			**22.757**
		036014	**Prenzlauer Berg Ost**	03601449	Michelangelostraße	10.002
				03601450	Volkspark Prenzlauer Berg	4.055
				03601451	Anton-Saefkow-Park	6.491
				03601452	Velodrom	4.020
				03601453	Alter Schlachthof	2.741
			Prenzlauer Berg Ost - gesamt			**27.309**
	Nördlicher Prenzlauer Berg - gesamt					**104.046**
0370	**Südlicher Prenzlauer Berg**	037015	**Prenzlauer Berg Südwest**	03701554	Teutoburger Platz	11.281
				03701555	Sredzkistraße	7.277
				03701556	Kollwitzplatz	8.625
			Prenzlauer Berg Südwest - gesamt			**27.183**
		037016	**Prenzlauer Berg Süd**	03701657	Thälmannpark	3.196
				03701658	Christburger Straße	8.554
				03701659	Immanuelkirchstraße	9.156
				03701660	Bötzowstraße	12.868
			Prenzlauer Berg Süd - gesamt			**33.774**

PGR ID	PGR Name	BZR ID	BZR Name	PLR ID	PLR Name	EW 31.12.19
	Südlicher Prenzlauer Berg - gesamt					**60.957**
04 Charlottenburg-Wilmersdorf						
0410	**Charlotten-burg Nord**	041001	**Charlottenburg Nord**	04100101	Jungfernheide/Plötzensee	11.615
				04100102	Paul-Hertz-Siedlung	7.964
			Charlottenburg Nord - gesamt			**19.579**
	Charlottenburg Nord - gesamt					**19.579**
0420	**Charlotten-burg West**	042002	**Heerstraße**	04200203	Olympiagelände	1.485
				04200204	Angerburger Allee	2.896
				04200205	Flatowallee	2.539
				04200206	Kranzallee	2.978
				04200207	Eichkamp	3.314
			Heerstraße - gesamt			**13.212**
		042003	**Westend**	04200308	Branitzer Platz	6.358
				04200309	Neu Westend	7.077
				04200310	Fürstenplatz	8.042
				04200311	Königin-Elisabeth-Straße	7.258
			Westend - gesamt			**28.735**
	Charlottenburg West - gesamt					**41.947**
0430	**Charlotten-burg Zentrum**	043004	**Schloss Charlot-tenburg**	04300412	Schlossgarten	3.346
				04300413	Klausenerplatz	10.593
				04300414	Schloßstraße	10.954
				04300415	Lietzensee	6.576
				04300416	Amtsgerichtsplatz	12.434
			Schloss Charlottenburg - gesamt			**43.903**
		043005	**Mierendorffplatz**	04300517	Tegeler Weg	9.561
				04300518	Kaiserin-Augusta-Allee	5.908
			Mierendorffplatz - gesamt			**15.469**
		043006	**Otto-Suhr-Allee/ Kantstraße**	04300619	Alt-Lietzow	8.928
				04300620	Spreestadt	3.172
				04300621	Richard-Wagner-Straße	10.910
				04300622	Ernst-Reuter-Platz	5.071
				04300623	Karl-August-Platz	12.303
				04300624	Savignyplatz	9.671

PGR ID	PGR Name	BZR ID	BZR Name	PLR ID	PLR Name	EW 31.12.19
			Otto-Suhr-Allee/Kantstraße - gesamt			**50.055**
	Charlottenburg Zentrum - gesamt					**109.427**
0440	Wilmersdorf Süd	044007	Grunewald	04400725	Güterbahnhof Grunewald	106
				04400726	Bismarckallee	5.323
				04400727	Flinsberger Platz	8.338
				04400728	Hagenplatz	3.130
				04400729	Hundekehle	2.814
			Grunewald - gesamt			**19.711**
		044008	Schmargendorf	04400830	Forckenbeckstraße	6.433
				04400831	Messelpark	1.544
				04400832	Breite Straße	7.042
				04400833	Schlangenbader Straße	4.200
				04400834	Binger Straße	3.579
				04400835	Rüdesheimer Platz	10.771
			Schmargendorf - gesamt			**33.569**
	Wilmersdorf Süd - gesamt					**53.280**
0450	Wilmersdorf Zentrum	045009	Halensee	04500936	Droysenstraße	5.732
				04500937	Halensee	7.621
				04500938	Hochmeisterplatz	8.135
				04500939	Eisenzahnstraße	6.437
			Halensee - gesamt			**27.925**
		045010	Lietzenburger Straße	04501040	Hindemithplatz	6.061
				04501041	George-Grosz-Platz	5.736
				04501042	Breitscheidplatz	3.725
				04501043	Preußenpark	10.980
				04501044	Ludwigkirchplatz	5.348
				04501045	Schaperstraße	9.342
			Lietzenburger Straße - gesamt			**41.192**
		045011	Volkspark Wilmersdorf	04501146	Barstraße	4.696
				04501147	Leon-Jessel-Platz	5.690
				04501148	Brabanter Platz	4.557
				04501149	Nikolsburger Platz	9.945
				04501150	Wilhelmsaue	3.081

PGR ID	PGR Name	BZR ID	BZR Name	PLR ID	PLR Name	EW 31.12.19
				04501151	Hildegardstraße	7.739
				04501152	Prager Platz	7.037
				04501153	Babelsberger Straße	7.497
			Volkspark Wilmersdorf - gesamt			**50.242**
	Wilmersdorf Zentrum - gesamt					**119.359**
05 Spandau						
0510	**Spandau Mitte / Nord**	051001	**Hakenfelde**	05100101	Hakenfelde Nord	4.040
				05100102	Am Forstacker	4.441
				05100103	Mertensstraße	5.747
				05100104	Maselake	4.868
				05100105	Amorbacher Weg	7.630
			Hakenfelde - gesamt			**26.726**
		051002	**Falkenhagener Feld**	05100206	Griesingerstraße	3.584
				05100207	An der Tränke	2.283
				05100208	Im Spektefeld	10.738
				05100209	Westerwaldstraße	11.609
				05100210	Germersheimer Platz	7.705
				05100211	An der Kappe	6.112
			Falkenhagener Feld - gesamt			**42.031**
		051003	**Spandau Mitte**	05100312	Eckschanze	3.953
				05100313	Eiswerder	5.633
				05100314	Kurstraße	7.463
				05100315	Ackerstraße	6.834
				05100316	Carl-Schurz-Straße	10.345
				05100317	Freiheit	3.646
			Spandau Mitte - gesamt			**37.874**
	Spandau Mitte / Nord - gesamt					**106.631**
0520	**Wilhelmstadt / Staaken**	052004	**Brunsbütteler Damm**	05200418	Isenburger Weg	3.835
				05200419	Am Heideberg	1.703
				05200420	Staakener Straße	5.862
				05200421	Spandauer Straße	4.395
				05200422	Werkstraße	921
				05200423	Magistratsweg	6.639

PGR ID	PGR Name	BZR ID	BZR Name	PLR ID	PLR Name	EW 31.12.19
			Brunsbütteler Damm - gesamt			**23.355**
		052005	**Heerstraße**	05200524	Döberitzer Weg	3.366
				05200525	Pillnitzer Weg	2.485
				05200526	Rudolf-Wissell-Großsiedlung	5.762
				05200527	Maulbeerallee	11.954
				05200528	Weinmeisterhornweg	7.069
			Heerstraße - gesamt			**30.636**
		052006	**Wilhelmstadt**	05200629	Borkumer Straße	7.689
				05200630	Wilhelmstadt West	9.754
				05200631	Wilhelmstadt Ost	8.490
				05200632	Tiefwerder	3.729
				05200633	Graetschelsteig	2.022
				05200634	Börnicker Straße	4.435
			Wilhelmstadt - gesamt			**36.119**
	Wilhelmstadt / Staaken - gesamt					**90.110**
0530	**Haselhorst / Siemensstadt**	053007	**Haselhorst**	05300735	Haveleck	1.350
				05300736	Zitadellenweg	3.678
				05300737	Gartenfelder Straße	10.652
			Haselhorst - gesamt			**15.680**
		053008	**Siemensstadt**	05300838	Gartenfeld	27
				05300839	Rohrdamm	7.708
				05300840	Nonnendammallee	504
				05300841	Siemensdamm	4.592
			Siemensstadt - gesamt			**12.831**
	Haselhorst / Siemensstadt - gesamt					**28.511**
0540	**Gatow / Kladow**	054009	**Gatow/Kladow**	05400942	Alt-Gatow	3.914
				05400943	Jägerallee	10.142
				05400944	Kladower Damm	2.203
				05400945	Kafkastraße	3.686
			Gatow/Kladow - gesamt			**19.945**
	Gatow / Kladow - gesamt					**19.945**
06 Steglitz-Zehlendorf						
0610	**Steglitz**	061001	**Schloßstraße**	06100101	Fichtenberg	6.958

PGR ID	PGR Name	BZR ID	BZR Name	PLR ID	PLR Name	EW 31.12.19
				06100102	Schloßstraße	8.835
				06100103	Markelstraße	6.428
			Schloßstraße - gesamt			**22.221**
		061002	**Albrechtstraße**	06100204	Munsterdamm	6.873
				06100205	Südende	9.820
				06100206	Stadtpark	7.787
				06100207	Mittelstraße	8.021
				06100208	Bergstraße	6.867
				06100209	Feuerbachstraße	9.318
				06100210	Bismarckstraße	4.896
			Albrechtstraße - gesamt			**53.582**
	Steglitz - gesamt					**75.803**
0620	**Lankwitz/ Lichterfelde Ost**	062003	**Lankwitz**	06200311	Alt-Lankwitz	5.004
				06200312	Komponistenviertel Lankwitz	6.083
				06200313	Lankwitz Kirche	7.364
				06200314	Kaiser-Wilhelm-Straße	7.261
				06200315	Gallwitzallee	5.931
				06200316	Belßstraße	5.530
				06200317	Lankwitz Süd	6.393
			Lankwitz - gesamt			**43.566**
		062004	**Ostpreußendamm**	06200418	Landweg	21
				06200419	Thermometersiedlung	4.662
				06200420	Lichterfelde Süd	6.971
				06200421	Königsberger Straße	8.455
				06200422	Oberhofer Platz	7.097
				06200423	Schütte-Lanz-Straße	8.636
			Ostpreußendamm - gesamt			**35.842**
	Lankwitz/Lichterfelde Ost - gesamt					**79.408**
0630	**Zehlendorf Süd/Lichter-felde West**	063005	**Teltower Damm**	06300524	Berlepschstraße	5.760
				06300525	Zehlendorf Süd	5.633
				06300526	Zehlendorf Mitte	3.340
				06300527	Sundgauer Straße	8.467
				06300528	Teltower Damm	11.133

PGR ID	PGR Name	BZR ID	BZR Name	PLR ID	PLR Name	EW 31.12.19
			Teltower Damm - gesamt			**34.333**
		063006	**Drakestraße**	06300629	Botanischer Garten	7.133
				06300630	Hindenburgdamm	5.623
				06300631	Goerzwerke	3.148
				06300632	Schweizer Viertel	13.784
				06300633	Augustaplatz	12.206
				06300634	Lichterfelde West	8.491
			Drakestraße - gesamt			**50.385**
	Zehlendorf Süd/Lichterfelde West - gesamt					**84.718**
0640	**Zehlendorf Nord/Wann-see**	064007	**Zehlendorf Südwest**	06400735	Wannsee	10.334
				06400736	Düppel	5.517
				06400737	Nikolassee	11.178
			Zehlendorf Südwest - gesamt			**27.029**
		064008	**Zehlendorf Nord**	06400838	Krumme Lanke	7.591
				06400839	Fischerhüttenstraße	5.298
				06400840	Fischtal	7.345
				06400841	Zehlendorf Eiche	5.971
				06400842	Hüttenweg	4.762
				06400843	Thielallee	5.007
				06400844	Dahlem	7.160
			Zehlendorf Nord - gesamt			**43.134**
	Zehlendorf Nord/Wannsee - gesamt					**70.163**
07 Tempelhof-Schöneberg						
0710	**Schöneberg Nord**	071001	**Schöneberg Nord-west**	07100101	Wittenbergplatz	10.138
				07100102	Kalckreuthstraße	8.838
				07100103	Frobenstraße	7.712
			Schöneberg Nordwest - gesamt			**26.688**
		071002	**Schöneberg Nord-ost**	07100204	Barbarossaplatz	10.542
				07100205	Alvenslebenstraße	5.381
				07100206	Großgörschenstraße	8.304
			Schöneberg Nordost - gesamt			**24.227**
	Schöneberg Nord - gesamt					**50.915**
0720		072003		07200307	Bayerischer Platz	10.620

PGR ID	PGR Name	BZR ID	BZR Name	PLR ID	PLR Name	EW 31.12.19
	Schöneberg Süd		Schöneberg Südwest	07200308	Volkspark (Rudolph-Wilde-Park)	10.488
			Schöneberg Südwest - gesamt			**21.108**
		072004	Schöneberg Südost	07200409	Belziger Straße	9.434
				07200410	Feurigstraße	5.652
				07200411	Julius-Leber-Brücke	2.818
				07200412	Schöneberger Linse	443
				07200413	Cheruskerstraße	7.896
				07200414	Hohenfriedbergstraße	3.798
			Schöneberg Südost - gesamt			**30.041**
	Schöneberg Süd - gesamt					**51.149**
0730	Friedenau	073005	Friedenau West	07300515	Taunusstraße	6.935
				07300516	Odenwaldstraße	8.965
				07300517	Perelsplatz	8.871
			Friedenau West - gesamt			**24.771**
		073006	Friedenau Ost	07300618	Ceciliengärten	9.409
				07300619	Grazer Platz	12.248
			Friedenau Ost - gesamt			**21.657**
	Friedenau - gesamt					**46.428**
0740	Tempelhof	074007	Tempelhof Nord	07400720	Gontermannstraße	12.076
				07400721	Paradestraße	5.526
			Tempelhof Nord - gesamt			**17.602**
		074008	Tempelhof Südwest	07400822	Lindenhofsiedlung	2.312
				07400823	Wittekindstraße	9.774
				07400824	Bosepark	7.456
				07400825	Friedrich-Karl-Straße	7.413
				07400826	Marienhöhe	5.153
			Tempelhof Südwest - gesamt			**32.108**
		074009	Tempelhof Südost	07400927	Rathaus Tempelhof	11.315
				07400928	Germaniagarten	4.069
			Tempelhof Südost - gesamt			**15.384**
	Tempelhof - gesamt					**65.094**
0750	Mariendorf	075010	Mariendorf Nord	07501029	Ringstraße	8.166
				07501030	Machonstraße	8.952

PGR ID	PGR Name	BZR ID	BZR Name	PLR ID	PLR Name	EW 31.12.19
				07501031	Eisenacher Straße	9.165
				07501032	Imbrosweg	5.693
			Mariendorf Nord - gesamt			**31.976**
		075011	**Mariendorf Süd**	07501133	Fritz-Werner-Straße	8.225
				07501134	Hundsteinweg	10.651
				07501135	Birnhornweg	2.254
			Mariendorf Süd - gesamt			**21.130**
	Mariendorf - gesamt					**53.106**
0760	**Marienfelde / Lichtenrade**	076012	**Marienfelde Nord**	07601236	Marienfelder Allee Nordwest	10.194
				07601237	Kirchstraße	4.792
				07601238	Marienfelde Nordost	2.845
			Marienfelde Nord - gesamt			**17.831**
		076013	**Marienfelde Süd**	07601339	Tirschenreuther Ring West	5.803
				07601340	Tirschenreuther Ring Ost	6.446
				07601341	Diedersdorfer Weg	2.257
			Marienfelde Süd - gesamt			**14.506**
		076014	**Lichtenrade Nord**	07601442	Kettinger Straße	10.540
				07601443	Töpchiner Weg	10.925
			Lichtenrade Nord - gesamt			**21.465**
		076015	**Lichtenrade Süd**	07601544	John-Locke-Straße	8.096
				07601545	Nahariyastraße	8.521
				07601546	Franziusweg	7.014
				07601547	Horstwalder Straße	3.866
				07601548	Wittelsbacherstraße	2.993
			Lichtenrade Süd - gesamt			**30.490**
	Marienfelde / Lichtenrade - gesamt					**84.292**
08 Neukölln						
0810	**Neukölln**	081001	**Schillerpromenade**	08100101	Hasenheide	4.526
				08100102	Schillerpromenade Nord	8.440
				08100103	Schillerpromenade Süd	7.577
				08100104	Wartheplatz	6.830
				08100105	Silbersteinstraße	5.042
			Schillerpromenade - gesamt			**32.415**

PGR ID	PGR Name	BZR ID	BZR Name	PLR ID	PLR Name	EW 31.12.19
		081002	**Neuköllner Mitte/Zentrum**	08100206	Flughafenstraße	9.873
				08100207	Rollberg	7.385
				08100208	Körnerpark	12.288
				08100209	Glasower Straße	8.439
			Neuköllner Mitte/Zentrum - gesamt			**37.985**
		081003	**Reuterstraße**	08100310	Maybachufer	8.046
				08100311	Reuterplatz	7.462
				08100312	Weichselplatz	12.094
				08100313	Bouchéstraße	3.880
				08100314	Donaustraße	8.389
			Reuterstraße - gesamt			**39.871**
		081004	**Rixdorf**	08100415	Ganghoferstraße	6.761
				08100416	Alt-Rixdorf	6.620
				08100417	Braunschweiger Straße	10.052
				08100418	Hertzbergplatz	9.743
				08100419	Treptower Straße Nord	7.148
			Rixdorf - gesamt			**40.324**
		081005	**Köllnische Heide**	08100520	Weiße Siedlung	5.785
				08100521	Schulenburgpark	9.777
			Köllnische Heide - gesamt			**15.562**
	Neukölln - gesamt					**166.157**
0820	**Britz/Buckow**	082006	**Britz Nord**	08200622	Jahnstraße	5.648
				08200623	Park am Buschkrug	5.959
				08200624	Tempelhofer Weg	8.737
			Britz Nord - gesamt			**20.344**
		082007	**Britz**	08200725	Mohriner Allee Nord	2.436
				08200726	Hufeisensiedlung	6.283
				08200727	Parchimer Allee Süd	8.051
				08200728	Ortolanweg	1.247
				08200729	Britzer Garten	1.840
				08200730	Handwerker-Siedlung	3.313
			Britz - gesamt			**23.170**
		082008	**Buckow**	08200831	Buckow West	8.410

PGR ID	PGR Name	BZR ID	BZR Name	PLR ID	PLR Name	EW 31.12.19
				08200832	Buckow Mitte	11.898
				08200833	Buckow Ost	8.837
			Buckow - gesamt			**29.145**
	Britz/Buckow - gesamt					**72.659**
0830	Gropiusstadt	083009	Gropiusstadt West	08300934	Gropiusstadt Nord-West	12.546
				08300935	Gropiusstadt Süd-West	7.258
			Gropiusstadt West - gesamt			**19.804**
		083010	Gropiusstadt Ost	08301036	Gropiusstadt Mitte	7.263
				08301037	Gropiusstadt Süd-Ost	10.440
			Gropiusstadt Ost - gesamt			**17.703**
	Gropiusstadt - gesamt					**37.507**
0840	Buckow Nord/Rudow	084011	Buckow Nord	08401138	Goldhähnchenweg	2.826
				08401139	Vogelviertel Süd	4.174
				08401140	Vogelviertel Nord	2.653
			Buckow Nord - gesamt			**9.653**
		084012	Rudow	08401241	Blumenviertel	8.324
				08401242	Zittauer Straße	6.814
				08401243	Alt-Rudow	9.937
				08401244	Waßmannsdorfer Chaussee	7.052
				08401245	Frauenviertel	3.837
				08401246	Waltersdorfer Chaussee Ost	7.962
			Rudow - gesamt			**43.926**
	Buckow Nord/Rudow - gesamt					**53.579**
09 Treptow-Köpenick						
0910	Treptow-Köpenick 1	091001	Alt-Treptow	09100101	Alt-Treptow	12.878
			Alt-Treptow - gesamt			**12.878**
		091002	Plänterwald	09100202	Plänterwald West	4.378
				09100203	Plänterwald Ost	6.987
			Plänterwald - gesamt			**11.365**
		091003	Baumschulenweg	09100304	Baumschulenweg West	11.703
				09100305	Baumschulenweg Ost	4.027
				09100306	Späthsfelde	3.112
			Baumschulenweg - gesamt			**18.842**

PGR ID	PGR Name	BZR ID	BZR Name	PLR ID	PLR Name	EW 31.12.19
		091004	**Johannisthal**	09100407	Johannisthal West	8.444
				09100408	Johannisthal Ost	8.022
				09100409	Landschaftspark Adlershof	3.387
			Johannisthal - gesamt			**19.853**
	Treptow-Köpenick 1 - gesamt					**62.938**
0920	**Treptow-Köpenick 2**	092005	**Oberschöneweide**	09200510	Helmholtz-Kiez	7.575
				09200511	Griechischer Park	12.683
				09200512	Wuhlheide	3.242
			Oberschöneweide - gesamt			**23.500**
		092006	**Niederschöne-weide**	09200613	Bahnhof Schöneweide	9.268
				09200614	Oberspree	3.582
			Niederschöneweide - gesamt			**12.850**
		092007	**Adlershof**	09200715	Wista	2.913
				09200716	Dörpfeldstraße West	7.616
				09200717	Dörpfeldstraße Ost	9.405
			Adlershof - gesamt			**19.934**
		092008	**Köllnische Vor-stadt/Spindlers-feld**	09200818	Spindlersfeld	2.470
				09200819	Köllnische Vorstadt	8.177
			Köllnische Vorstadt/Spindlersfeld - gesamt			**10.647**
	Treptow-Köpenick 2 - gesamt					**66.931**
0930	**Treptow-Köpenick 3**	093009	**Altglienicke**	09300920	Dorf Altglienicke	11.514
				09300921	Preußen Siedlung	2.600
				09300922	Kosmos Viertel	5.639
				09300923	Kölner Viertel	8.161
			Altglienicke - gesamt			**27.914**
		093010	**Bohnsdorf**	09301024	Falkenberg	2.292
				09301025	Alt-Bohnsdorf	10.822
			Bohnsdorf - gesamt			**13.114**
		093011	**Grünau**	09301126	Grünau	6.784
			Grünau - gesamt			**6.784**
		093012	**Schmöckwitz**	09301227	Karolinenhof	1.852
				09301228	Schmöckwitz/Rauchfangswerder	2.572
			Schmöckwitz - gesamt			**4.424**

PGR ID	PGR Name	BZR ID	BZR Name	PLR ID	PLR Name	EW 31.12.19
	Treptow-Köpenick 3 - gesamt					**52.236**
0940	Treptow-Köpenick 4	094013	Köpenick Süd	09401329	Kietzer Feld/Nachtheide	10.116
				09401330	Wendenschloß	1.907
			Köpenick Süd - gesamt			**12.023**
		094014	Allende-Viertel	09401431	Allende I	5.447
				09401432	Siedlung Kämmereiheide	1.567
				09401433	Allende II	4.441
			Allende-Viertel - gesamt			**11.455**
		094015	Altstadt Köpenick	09401534	Altstadt Köpenick	7.294
			Altstadt Köpenick - gesamt			**7.294**
		094016	Müggelheim	09401635	Müggelheim	6.798
			Müggelheim - gesamt			**6.798**
	Treptow-Köpenick 4 - gesamt					**37.570**
0950	Treptow-Köpenick 5	095017	Friedrichshagen	09501736	Hirschgarten	4.592
				09501737	Alt-Friedrichshagen	14.553
			Friedrichshagen - gesamt			**19.145**
		095018	Rahnsdorf	09501838	Rahnsdorf	9.523
			Rahnsdorf - gesamt			**9.523**
		095019	Dammvorstadt	09501939	Bahnhofstraße	6.347
				09501940	Güterbahnhof Köpenick	2.630
				09501941	Friedrichshagener Straße	2.627
			Dammvorstadt - gesamt			**11.604**
		095020	Köpenick Nord	09502042	Mittelheide	4.099
				09502043	Dammheide	9.174
			Köpenick Nord - gesamt			**13.273**
	Treptow-Köpenick 5 - gesamt					**53.545**
10 Marzahn-Hellersdorf						
1010	Marzahn	101001	Marzahn Nord	10100101	Marzahn West	5.687
				10100102	Rosenbecker Straße	3.295
				10100103	Wittenberger Straße	7.548
				10100104	Golliner Straße	7.628
			Marzahn Nord - gesamt			**24.158**
		101002	Marzahn Mitte	10100205	Gewerbegebiet Bitterfelder Straße	1.308

PGR ID	PGR Name	BZR ID	BZR Name	PLR ID	PLR Name	EW 31.12.19
				10100206	Wuhletalstraße	10.616
				10100207	Ahrensfelder Berge	8.165
				10100208	Bürgerpark	8.900
				10100209	Lea-Grundig-Straße	8.393
				10100210	Marzahner Promenade	10.626
			Marzahn Mitte - gesamt			**48.008**
		101003	**Marzahn Süd**	10100311	Marzahner Chaussee	2.214
				10100312	Springpfuhl	14.605
				10100313	Alt-Marzahn	4.709
				10100314	Auersbergstraße	6.366
				10100315	Bärenstein	7.265
				10100316	Landsberger Tor	3.696
			Marzahn Süd - gesamt			**38.855**
	Marzahn - gesamt					**111.021**
1020	**Hellersdorf**	102004	**Hellersdorf Nord**	10200417	Zossener Straße	7.230
				10200418	Kyritzer Straße	5.542
				10200419	Havelländer Ring	3.429
				10200420	Gut Hellersdorf	7.191
				10200421	Helle Mitte	1.728
				10200422	Hellersdorfer Promenade	5.854
				10200423	Böhlener Straße	5.654
			Hellersdorf Nord - gesamt			**36.628**
		102005	**Hellersdorf Ost**	10200524	Adele-Sandrock-Straße	9.486
				10200525	Schleipfuhl	5.318
				10200526	Boulevard Kastanienallee	6.052
			Hellersdorf Ost - gesamt			**20.856**
		102006	**Hellersdorf Süd**	10200627	Am Kienberg	3.379
				10200628	Neue Grottkauer Straße	6.317
				10200629	Teterower Ring	8.547
				10200630	Cecilienplatz	6.537
			Hellersdorf Süd - gesamt			**24.780**
	Hellersdorf - gesamt					**82.264**
1030	**Biesdorf**	103007	**Biesdorf**	10300731	Oberfeldstraße	7.820

PGR ID	PGR Name	BZR ID	BZR Name	PLR ID	PLR Name	EW 31.12.19
				10300732	Buckower Ring	6.671
				10300733	Alt-Biesdorf	3.488
				10300734	Biesdorf Süd	10.084
			Biesdorf - gesamt			**28.063**
	Biesdorf - gesamt					**28.063**
1040	Kaulsdorf/ Mahlsdorf	104008	Kaulsdorf	10400835	Kaulsdorf Nord	7.800
				10400836	Alt-Kaulsdorf	3.938
				10400837	Kaulsdorf Süd	7.670
			Kaulsdorf - gesamt			**19.408**
		104009	Mahlsdorf	10400938	Mahlsdorf Nord	9.753
				10400939	Alt-Mahlsdorf	4.295
				10400940	Elsensee	5.782
				10400941	Pilgramer Straße	9.530
			Mahlsdorf - gesamt			**29.360**
	Kaulsdorf/Mahlsdorf - gesamt					**48.768**
11 Lichtenberg						
1110	Hohenschön-hausen Nord	111001	Malchow, Warten-berg und Falken-berg	11100101	Dörfer Malchow-Wartenberg	3.264
				11100102	Dorf Falkenberg	1.870
			Malchow, Wartenberg und Falkenberg - gesamt			**5.134**
		111002	Neu-Hohenschön-hausen Nord	11100203	Falkenberg Ost	8.985
				11100204	Falkenberg West	7.069
				11100205	Wartenberg Süd	6.127
				11100206	Wartenberg Nord	7.494
			Neu-Hohenschönhausen Nord - gesamt			**29.675**
		111003	Neu-Hohenschön-hausen Süd	11100307	Zingster Straße Ost	11.760
				11100308	Zingster Straße West	9.675
				11100309	Mühlengrund	5.727
			Neu-Hohenschönhausen Süd - gesamt			**27.162**
	Hohenschönhausen Nord - gesamt					**61.971**
1120	Hohenschön-hausen Süd	112004	Alt-Hohenschön-hausen Nord	11200410	Malchower Weg	9.618
				11200411	Hauptstraße	6.825
			Alt-Hohenschönhausen Nord - gesamt			**16.443**
		112005		11200512	Orankesee	3.938

PGR ID	PGR Name	BZR ID	BZR Name	PLR ID	PLR Name	EW 31.12.19
			Alt-Hohenschön-hausen Süd	11200513	Große-Leege-Straße	9.729
				11200514	Landsberger Allee	14.760
				11200515	Weiße Taube	4.109
			Alt-Hohenschönhausen Süd - gesamt			**32.536**
	Hohenschönhausen Süd - gesamt					**48.979**
1130	**Lichtenberg Nord**	113006	**Fennpfuhl**	11300616	Hohenschönhausener Straße	6.313
				11300617	Fennpfuhlpark	4.316
				11300618	Storkower Bogen	3.764
				11300619	Rudolf-Seiffert-Park	8.549
				11300620	Fennpfuhl Ost	11.132
			Fennpfuhl - gesamt			**34.074**
		113007	**Alt-Lichtenberg**	11300721	Herzbergstraße	5.483
				11300722	Rathaus Lichtenberg	9.685
				11300723	Bornitzstraße	2.869
				11300724	Roedeliusplatz	3.935
				11300725	Nibelungenviertel	9.677
			Alt-Lichtenberg - gesamt			**31.649**
		113008	**Frankfurter Allee Süd**	11300826	Frankfurter Allee Süd	10.109
			Frankfurter Allee Süd - gesamt			**10.109**
	Lichtenberg Nord - gesamt					**75.832**
1140	**Lichtenberg Mitte**	114009	**Neu-Lichtenberg**	11400927	Victoriastadt	4.231
				11400928	Nöldnerplatz	2.237
				11400929	Weitlingkiez	16.172
				11400930	Zachertstraße	4.505
				11400931	Massower Straße	6.682
			Neu-Lichtenberg - gesamt			**33.827**
		114010	**Friedrichsfelde Nord**	11401032	Rosenfelder Ring	5.457
				11401033	Gensinger Straße	6.739
				11401034	Tierpark	3.181
			Friedrichsfelde Nord - gesamt			**15.377**
		114011	**Friedrichsfelde Süd**	11401135	Dolgenseestraße	9.299
				11401136	Volkradstraße	8.193
				11401137	Erieseering	8.475

PGR ID	PGR Name	BZR ID	BZR Name	PLR ID	PLR Name	EW 31.12.19
			Friedrichsfelde Süd - gesamt			**25.967**
	Lichtenberg Mitte - gesamt					**75.171**
1150	Lichtenberg Süd	115012	Rummelsburger Bucht	11501238	Rummelsburg	4.254
			Rummelsburger Bucht - gesamt			**4.254**
		115013	Karlshorst	11501339	Karlshorst West	10.218
				11501340	Karlshorst Nord	10.623
				11501341	Karlshorst Süd	7.153
			Karlshorst - gesamt			**27.994**
	Lichtenberg Süd - gesamt					**32.248**
12 Reinickendorf						
1210	Reinickendorf Ost	121001	Ost 1 - Reginhardstraße	12100101	Letteplatz	10.983
				12100102	Hausotterplatz	10.059
				12100103	Breitkopfbecken	7.755
			Ost 1 - Reginhardstraße - gesamt			**28.797**
		121002	Ost 2 - Alt-Reinickendorf	12100204	Schäfersee	8.901
				12100205	Teichstraße	14.069
				12100206	Humboldtstraße	4.624
			Ost 2 - Alt-Reinickendorf - gesamt			**27.594**
	Reinickendorf Ost - gesamt					**56.391**
1220	Tegel	122003	West 4 - Auguste-Viktoria-Allee	12200307	Reinickes Hof	2.753
				12200308	Mellerbogen	5.669
				12200309	Scharnweberstraße	10.432
				12200310	Klixstraße	8.304
			West 4 - Auguste-Viktoria-Allee - gesamt			**27.158**
		122004	West 1 - Tegel-Süd/Flughafensee	12200411	Schumacher-Quartier	360
				12200412	Waldidyll/Flughafensee	6.404
				12200413	Tegel Süd	8.132
				12200414	TXL	1.429
			West 1 - Tegel-Süd/Flughafensee - gesamt			**16.325**
		122005	West 5 - Tegel	12200515	Alt-Tegel	11.006
			West 5 - Tegel - gesamt			**11.006**
	Tegel - gesamt					**54.489**
1240	Grüner Norden	124006		12400616	Konradshöhe/Tegelort	6.004

PGR ID	PGR Name	BZR ID	BZR Name	PLR ID	PLR Name	EW 31.12.19
			West 2 - Heiligen-see/Konradshöhe	12400617	Alt-Heiligensee	6.934
				12400618	Heiligensee Nord	3.644
				12400619	Heiligensee	7.791
			West 2 - Heiligensee/Konradshöhe - gesamt			**24.373**
		124007	Nord 1 - Frohnau/Herms-dorf	12400720	Frohnau West	8.713
				12400721	Frohnau Ost	8.101
				12400722	Hermsdorf West	8.567
				12400723	Hermsdorf Ost/Waldsee	8.040
			Nord 1 - Frohnau/Hermsdorf - gesamt			**33.421**
	Grüner Norden - gesamt					**57.794**
1250	Wittenau/Bor-sigwalde	125008	West 3 - Borsig-walde/Freie Scholle	12500824	Ziekowstraße/Freie Scholle	9.746
				12500825	Borsigwalde	6.756
			West 3 - Borsigwalde/Freie Scholle - gesamt			**16.502**
		125009	Nord 2 - Waid-mannslust/Wit-tenau/Lübars	12500926	Wittenau Süd	4.975
				12500927	Wittenau Nord	6.387
				12500928	Waidmannslust	4.990
				12500929	Lübars	5.203
				12500930	Wittenau Mitte	10.024
			Nord 2 - Waidmannslust/Wittenau/Lübars - gesamt			**31.579**
	Wittenau/Borsigwalde - gesamt					**48.081**
1260	Märkisches Viertel	126010	Rollbergesiedlung	12601031	Lübarser Straße	3.291
				12601032	Rollbergesiedlung	5.983
			Rollbergesiedlung - gesamt			**9.274**
		126011	MV Nord	12601133	Treuenbrietzener Straße	11.714
				12601134	Märkisches Zentrum	14.827
			MV Nord - gesamt			**26.541**
		126012	MV Süd	12601235	Dannenwalder Weg	10.708
				12601236	Schorfheidestraße	3.130
			MV Süd - gesamt			**13.838**
	Märkisches Viertel - gesamt					**49.653**

Quelle: eigene Zusammenstellung; Daten: AfS

Gegenüberstellung / Synopse zu Änderungen an der LOR-Systematik im Zuge der Modifikation

Die nachfolgende Übersicht stellt die vorgenommenen Modifikationen auf Ebene der LOR und die jeweiligen Auswirkungen auf Nummerierung und Namensgebung vor. Für jeden Bezirk gibt es eine eigene Tabelle. In der Spalte „Maßnahme“ werden Teilungen, Zusammenlegungen sowie Anpassungen des Grenzverlaufes dokumentiert. Die Neunummerierung, die für alle LOR vollzogen wurde, wird nicht explizit als Maßnahme beschrieben. Namensänderungen lassen sich durch den Abgleich zwischen altem und neuem Namen ableiten und werden nicht explizit unter „Modifikation“ geführt.

01 Mitte

PRG ID alt	PRG Name alt	BZR ID alt	BZR Name alt	PLR ID alt	PLR Name alt	Modifikation → T = Teilung in … (PLR neu) Z = Zusammenlegung zu … (PLR neu) G = Anpassung Grenze	PRG ID neu	PRG Name neu	BZR ID neu	BZR Name neu	PLR ID neu	PLR Name neu
0101	Zentrum	010111	Tiergarten Süd	01011101	Stülerstraße	-	0110	Zentrum	011001	Tiergarten Süd	01100101	Stülerstraße
				01011102	Großer Tiergarten	Z 01100102					01100102	Großer Tiergarten
				01011103	Lützowstraße	-					01100103	Lützowstraße
				01011104	Körnerstraße	-					01100104	Körnerstraße
				01011105	Nördlicher Landwehrkanal	Z 01100102						
		010112	Regierungsviertel	01011201	Wilhelmstraße	-			011002	Regierungsviertel	01100205	Wilhelmstraße
				01011202	Unter den Linden Nord	Z 01100206					01100206	Unter den Linden
				01011203	Unter den Linden Süd	Z 01100206						
				01011204	Leipziger Straße	-					01100207	Leipziger Straße
		010113	Alexanderplatz	01011301	Charitéviertel	-			011003	Alexanderplatz	01100308	Charitéviertel
				01011302	Oranienburger Straße	-					01100309	Oranienburger Straße
				01011303	Alexanderplatzviertel	-					01100310	Alexanderplatzviertel
				01011304	Karl-Marx-Allee	-					01100311	Karl-Marx-Allee
				01011305	Heine-Viertel West	-					01100312	Heine-Viertel West
				01011306	Heine-Viertel Ost	-					01100313	Heine-Viertel Ost
		010114	Brunnenstraße Süd	01011401	Invalidenstraße	T 01100414/ 15			011004	Brunnenstraße Süd	01100414	Nordbahnhof
											01100415	Invalidenstraße
				01011402	Arkonaplatz	-					01100416	Arkonaplatz

0102	Moabit	010221	Moabit West	01022101	Huttenkiez	Z 01200517	0120	Moabit	012005	Moabit West	01200517	Huttenkiez
				01022102	Beusselkiez	-					01200518	Beusselkiez
				01022103	Westhafen	Z 01200517						
				01022104	Emdener Straße	T 01200519/ 20					01200519	Emdener Straße
											01200520	Bremer Straße
				01022105	Zwinglistraße	-					01200521	Zwinglistraße
				01022106	Elberfelder Straße	-					01200522	Elberfelder Straße
		010222	Moabit Ost	01022201	Stephankiez	-			012006	Moabit Ost	01200623	Stephankiez
				01022202	Heidestraße	-					01200624	Heidestraße
				01022203	Lübecker Straße	-					01200625	Lübecker Straße
				01022204	Thomasius-straße	-					01200626	Thomasius-straße
				01022205	Zillesiedlung	-					01200627	Zillesiedlung
				01022206	Lüneburger Straße	-					01200628	Lüneburger Straße
				01022207	Hansaviertel	-					01200629	Hansaviertel
0103	Gesund-brunnen	010331	Osloer Straße	01033101	Soldiner Straße	T 01300730/ 31/32	0130	Gesund-brunnen	013007	Osloer Straße	01300730	Drontheimer Straße
											01300731	Koloniestraße
											01300732	Soldiner Straße
				01033102	Gesundbrunnen	-					01300733	Gesundbrun-nen
		010332	Brunnenstraße Nord	01033201	Brunnenstraße	-			013008	Brunnenstraße Nord	01300834	Brunnenstraße
				01033202	Humboldthain Süd	-					01300835	Humboldthain Süd
				01033203	Humboldthain Nordwest	-					01300836	Humboldthain Nordwest
0104	Wedding	010441	Parkviertel	01044101	Rehberge	T 01400937/ 38	0140	Wedding	014009	Parkviertel	01400937	Afrikanische Straße
											01400938	Kameruner Straße
				01044102	Schillerpark	T 01400939/ 40/41					01400939	Glasgower Straße
											01400940	Schillerpark

											01400941	Londoner Straße
				01044103	Westliche Müllerstraße	-					01400942	Westliche Müllerstraße
		010442	Wedding Zentrum	01044201	Reinickendorfer Straße	T 01401043/ 44/45			014010	Wedding Zentrum	01401043	Antonstraße
											01401044	Uferstraße
											01401045	Schwedenstraße
				01044202	Sparrplatz	T 01401046/ 47					01401046	Nordufer
											01401047	Sparrplatz
				01044203	Leopoldplatz	T 01401048/ 49					01401048	Leopoldplatz
											01401049	Schulstraße

02 Friedrichshain-Kreuzberg												
PRG ID alt	PRG Name alt	BZR ID alt	BZR Name alt	PLR ID alt	PLR Name alt	Modifikation → T = Teilung in … (PLR neu) Z = Zusammenlegung zu … (PLR neu) G = Anpassung Grenze	PRG ID neu	PRG Name neu	BZR ID neu	BZR Name neu	PLR ID neu	PLR Name neu
0201	Kreuzberg Nord	020101	Südliche Friedrichstadt	02010101	Askanischer Platz	-	0210	Kreuzberg Nord	021001	Südliche Friedrichstadt	02100101	Askanischer Platz
				02010102	Mehringplatz	T 02100103/ 04					02100102	Mehringplatz
											02100103	Am Berlin Museum
				02010103	Moritzplatz	T 02100104/ 05					02100104	Moritzplatz
											02100105	Prinzenstraße
				02010104	Wassertorplatz	-					02100106	Wassertorplatz
0202	Kreuzberg Süd	020202	Tempelhofer Vorstadt	02020201	Gleisdreieck/ Entwicklungsgebiet	-	0220	Kreuzberg Süd	022002	Tempelhofer Vorstadt	02200207	Gleisdreieck
				02020202	Rathaus Yorckstraße	-					02200208	Rathaus Yorckstraße
				02020203	Viktoriapark	-					02200209	Viktoriapark
				02020204	Urbanstraße	-					02200210	Urbanstraße
				02020205	Chamissokiez	-					02200211	Chamissokiez
				02020206	Graefekiez	T 02200212/ 13					02200212	Graefekiez Süd
											02200213	Graefekiez Nord
0203	Kreuzberg Ost	020303	Nördliche Luisenstadt	02030301	Oranienplatz	-	0230	Kreuzberg Ost	023003	Nördliche Luisenstadt	02300314	Oranienplatz
				02030302	Lausitzer Platz	T 02300315/16					02300315	Lausitzer Platz
											02300316	Köpenicker Straße
		020304	Südliche Luisenstadt	02030401	Reichenberger Straße	T 02300417/18			023004	Südliche Luisenstadt	02300417	Reichenberger Straße West
											02300418	Reichenberger Straße Ost
				02030402	Wrangelkiez	-					02300419	Wrangelkiez
0204	Friedrichshain West	020405	Karl-Marx-Allee Nord	02040501	Barnimkiez	-	0240	Friedrichshain West	024005	Karl-Marx-Allee Nord	02400520	Barnimkiez
				02040502	Friedenstraße	-					02400521	Friedenstraße
				02040503	Richard-Sorge-Viertel	-					02400522	Richard-Sorge-Viertel
		020407	Karl-Marx-Allee Süd	02040701	Andreasviertel	-			024006	Karl-Marx-Allee Süd	02400623	Andreasviertel
				02040702	Weberwiese	-					02400624	Weberwiese

				02040703	Wriezener Bahnhof/Entwicklungsgebiet	-					02400625	Wriezener Bahnhof
0205	Friedrichshain Ost	020506	Frankfurter Allee Nord	02050601	Hausburgviertel	-	0250	Friedrichshain Ost	025007	Frankfurter Allee Nord	02500726	Hausburgviertel
				02050602	Samariterviertel	T 02500727/ 28/29					02500727	Forckenbeckplatz
											02500728	Samariterviertel
											02500729	Pettenkofer Straße
		020508	Frankfurter Allee Süd FK	02050801	Traveplatz	T 02500830/ 31/32			025008	Frankfurter Allee Süd FK	02500830	Niederbarnimstraße
											02500831	Wismarplatz
											02500832	Traveplatz
				02050802	Boxhagener Platz	T 02500833/ 34					02500833	Boxhagener Platz
											02500834	Revaler Straße
				02050803	Stralauer Kiez	-					02500835	Stralauer Kiez
				02050804	Stralauer Halbinsel	-					02500836	Stralauer Halbinsel

03 Pankow

PRG ID alt	PRG Name alt	BZR ID alt	BZR Name alt	PLR ID alt	PLR Name alt	Modifikation → T = Teilung in … (PLR neu) Z = Zusammenlegung zu … (PLR neu) G = Anpassung Grenze	PRG ID neu	PRG Name neu	BZR ID neu	BZR Name neu	PLR ID neu	PLR Name neu
0301	Buch	030101	Buch	03010101	Bucher Forst	Z 03100101	0310	Buch	031001	Buch	03100101	Bucher Forst
				03010102	Buch	T 03100102/ 03					03100102	Klinikum Buch
											03100103	Karower Chaussee
				03010104	Lietzengraben	Z 03100101						
0302	Nördliches Pankow	030202	Blankenfelde/ Nieder-schön-hausen	03020203	Blankenfelde	-	0320	Nördliches Pankow	032002	Blankenfelde/ Nieder-schön-hausen	03200204	Blankenfelde
				03020209	Niederschönhau-sen	T 03200205/ 06					03200205	Uhlandstraße
											03200206	Pastor-Niemöller-Platz
				03020210	Herthaplatz	-					03200207	Herthaplatz
		030203	Buchholz	03020307	Buchholz	T 03200308/ 09/10			032003	Buchholz	03200308	Nisbléstraße
											03200309	Eddastraße
											03200310	Krugpfuhl
0303	Nördliches Weißen-see	030304	Karow	03030405	Karow Nord	-	0330	Nördliches Weißen-see	033004	Karow	03300411	Karow Nord
				03030406	Alt-Karow	T 03300412/13					03300412	Karow Bahnhof
											03300413	Karow Ost
		030307	Blankenburg/ Heinersdorf/ Märchenland	03030711	Blankenburg	T 03300514/15			033005	Blankenburg/ Heinersdorf/ Märchenland	03300514	Blankenburg
											03300515	Blankenburger Sü-den
				03030715	Heinersdorf	-					03300516	Heinersdorf
				03030716	Märchenland	-					03300517	Märchenland
0304	Südliches Pankow	030405	Schönholz/ Wilhelmsruh/ Rosenthal	03040508	Rosenthal	-	0340	Südliches Pankow	034006	Schönholz/ Wilhelmsruh/ Rosenthal	03400618	Rosenthal
				03040512	Wilhelmsruh	-					03400619	Wilhelmsruh
				03040513	Schönholz	-					03400620	Schönholz
		030406	Pankow Zent-rum	03040614	Pankow Zentrum	T 03400721/ 22/23/24/25			034007	Pankow Zent-rum	03400721	Florakiez
											03400722	Parkstraße
											03400723	Garbátyplatz
											03400724	Wolfshagener Straße
											03400725	Schlosspark
		030408	Pankow Süd	03040818	Pankow Süd	T 03400826/ 27/28/29/30/31			034008	Pankow Süd	03400826	Tiroler Viertel
											03400827	Trelleborger Viertel
											03400828	Spiekermann Straße
											03400829	Arnold-Zweig-Straße
											03400830	Kissingenviertel

											03400831	Pankower Tor
0305	Südliches Weißen-see	030509	Weißensee	03050919	Gustav-Adolf-Straße	-	0350	Südliches Weißen-see	035009	Weißensee	03500932	Bühringstraße
				03050920	Weißer See	-					03500933	Weißer See
				03050923	Weißenseer Spitze	-					03500934	Weißenseer Spitze
				03050924	Behaimstraße	-					03500935	Behaimstraße
				03050925	Komponistenvier-tel Weißensee	-					03500936	Komponistenviertel Weißensee
		030510	Weißensee Ost	03051017	Rennbahnstraße	G 03501037 G 03501038			035010	Weißensee Ost	03501037	Rathaus Weißensee
				03051021	Buschallee	G 03501037 G 03501038						
				03051022	Hansastraße	G 03501038					03501038	Hansastraße
0306	Nördlicher Prenzlauer Berg	030611	Prenzlauer Berg Nord-west	03061126	Arnimplatz	T 03601139/ 40/41	0360	Nördlicher Prenzlauer Berg	036011	Prenzlauer Berg Nord-west	03601139	Norweger Viertel
											03601140	Malmöer Straße
											03601141	Arnimplatz
				03061131	Falkplatz	-					03601142	Falkplatz
		030612	Prenzlauer Berg Nord	03061227	Humannplatz	T 03601243/44			036012	Prenzlauer Berg Nord	03601243	Rodenbergstraße
											03601244	Humannplatz
				03061228	Erich-Weinert-Straße	-					03601245	Ostseestraße
		030613	Helmholtz-platz	03061332	Helmholtzplatz	T 03601346/ 47/48			036013	Helmholtz-platz	03601346	Gethsemanekirche
											03601347	Helmholtzplatz
											03601348	Senefelderstraße
		030614	Prenzlauer Berg Ost	03061429	Greifswalder Straße	-			036014	Prenzlauer Berg Ost	03601449	Michelangelostraße
				03061430	Volkspark Prenz-lauer Berg	-					03601450	Volkspark Prenzlauer Berg
				03061434	Anton-Saefkow-Park	-					03601451	Anton-Saefkow-Park
				03061435	Conrad-Blenkle-Straße	-					03601452	Velodrom
				03061441	Eldenaer Straße	-					03601453	Alter Schlachthof
0307	Südlicher Prenzlauer Berg	030715	Prenzlauer Berg Südwest	03071536	Teutoburger Platz	-	0370	Südlicher Prenzlauer Berg	037015	Prenzlauer Berg Südwest	03701554	Teutoburger Platz
				03071537	Kollwitzplatz	T 0370155/56					03701555	Sredzkistraße
											03701556	Kollwitzplatz
		030716		03071633	Thälmannpark	-			037016		03701657	Thälmannpark

			Prenzlauer Berg Süd	03071638	Winsstraße	T 03701658/59				Prenzlauer Berg Süd	03701658	Christburger Straße
											03701659	Immanuelkirchstraße
				03071639	Bötzowstraße	-					03701660	Bötzowstraße

04 Charlottenburg-Wilmersdorf

PRG ID alt	PRG Name alt	BZR ID alt	BZR Name alt	PLR ID alt	PLR Name alt	Modifikation → T = Teilung in ... (PLR neu) Z = Zusammenlegung zu ... (PLR neu) G = Anpassung Grenze	PRG ID neu	PRG Name neu	BZR ID neu	BZR Name neu	PLR ID neu	PLR Name neu
0401	CW 1	040101	Charlottenburg Nord	04010101	Jungfernheide	Z 04100101	0410	Charlottenburg Nord	041001	Charlottenburg Nord	04100101	Jungfernheide/ Plötzensee
				04010102	Plötzensee	Z 04100101						
				04010103	Paul-Hertz-Sied-lung	-					04100102	Paul-Hertz-Sied-lung
0402	CW 2	040202	Heerstrasse	04020204	Olympiagelände	Z 04200203	0420	Charlottenburg West	042002	Heerstraße	04200203	Olympiagelände
				04020205	Siedlung Ruhle-ben	Z 04200203						
				04020206	Angerburger Al-lee	-					04200204	Angerburger Allee
				04020207	Flatowallee	-					04200205	Flatowallee
				04020208	Kranzallee	-					04200206	Kranzallee
				04020209	Eichkamp	Z 04200207					04200207	Eichkamp
		040203	Westend	04020310	Park Ruhwald	Z 04200308			042003	Westend	04200308	Branitzer Platz
				04020311	Reichsstraße	T 04200309/ 10					04200309	Neu Westend
											04200310	Fürstenplatz
				04020312	Branitzer Platz	Z 04200308						
				04020313	Königin-Elisa-beth-Straße	Z 04200311					04200311	Königin-Elisabeth-Straße
				04020314	Messegelände	Z 04200311						
0403	CW 3	040304	Schloß Charlot-tenburg	04030415	Schloßgarten	-	0430	Charlottenburg Zentrum	043004	Schloss Charlot-tenburg	04300412	Schlossgarten
				04030416	Klausenerplatz	-					04300413	Klausenerplatz
				04030417	Schloßstraße	-					04300414	Schloßstraße
		040305	Mierendorffplatz	04030518	Tegeler Weg	-			043005	Mierendorffplatz	04300517	Tegeler Weg
				04030519	Kaiserin-Augusta-Allee	-					04300518	Kaiserin-Augusta-Allee
		040306	Otto-Suhr-Allee	04030620	Alt-Lietzow	-			043006	Otto-Suhr-Allee/ Kantstraße	04300619	Alt-Lietzow
				04030621	Spreestadt	-					04300620	Spreestadt
				04030622	Richard-Wagner-Straße	-					04300621	Richard-Wagner-Straße
				04030623	Ernst-Reuter-Platz	-					04300622	Ernst-Reuter-Platz

		040307	Neue Kantstraße	04030724	Lietzensee	-			043004	Schloss Charlottenburg	04300415	Lietzensee
				04030725	Amtsgerichtsplatz	-					04300416	Amtsgerichtsplatz
				04030726	Droysenstraße	-	0450	Wilmersdorf Zentrum	045009	Halensee	04500936	Droysenstraße
		040308	Kantstraße	04030827	Karl-August-Platz	-	0430	Charlottenburg Zentrum	043006	Otto-Suhr-Allee/ Kantstraße	04300623	Karl-August-Platz
				04030828	Savignyplatz	-					04300624	Savignyplatz
		040309	Kurfürstendamm	04030929	Hindemithplatz	-	0450	Wilmersdorf Zentrum	045010	Lietzenburger Straße	04501040	Hindemithplatz
				04030930	George-Grosz-Platz	-					04501041	George-Grosz-Platz
				04030931	Breitscheidplatz	-					04501042	Breitscheidplatz
		040310	Halensee	04031032	Halensee	T 04500937/ 38			045009	Halensee	04500937	Halensee
											04500938	Hochmeisterplatz
0404	CW 4	040411	Grunewald	04041133	Güterbahnhof Grunewald	-	0440	Wilmersdorf Süd	044007	Grunewald	04400725	Güterbahnhof Grunewald
				04041134	Bismarckallee	-					04400726	Bismarckallee
				04041135	Hundekehle	G 04400729					04400729	Hundekehle
				04041136	Hagenplatz	-					04400728	Hagenplatz
				04041137	Flinsberger Platz	-					04400727	Flinsberger Platz
		040412	Schmargendorf	04041238	Kissinger Straße	Z 04400830			044008	Schmargendorf	04400830	Forckenbeckstraße
				04041239	Stadion Wilmersdorf	Z 04400830						
				04041240	Messelpark	-					04400831	Messelpark
				04041241	Breite Straße	-					04400832	Breite Straße
		040413	Wiesbadener Straße	04041342	Schlangenbader Straße	-					04400833	Schlangenbader Straße
				04041343	Binger Straße	-					04400834	Binger Straße
				04041344	Rüdesheimer Platz	-					04400835	Rüdesheimer Platz
0405	CW 5	040514	Düsseldorfer Straße	04051445	Eisenzahnstraße	-	0450	Wilmersdorf Zentrum	045009	Halensee	04500939	Eisenzahnstraße
				04051446	Preußenpark	-			045010	Lietzenburger Straße	04501043	Preußenpark
				04051447	Ludwigkirchplatz	-					04501044	Ludwigkirchplatz
				04051448	Schaperstraße	-					04501045	Schaperstraße
		040515	Barstraße	04051549	Rathaus Wilmersdorf	-			045011	Volkspark Wilmersdorf	04501146	Barstraße
				04051550	Leon-Jessel-Platz	-					04501147	Leon-Jessel-Platz
				04051551	Brabanter Platz	-					04501148	Brabanter Platz

		040516	Volkspark Wilmersdorf	04051652	Nikolsburger Platz	-					04501149	Nikolsburger Platz
				04051653	Prager Platz	-					04501152	Prager Platz
				04051654	Wilhelmsaue	-					04501150	Wilhelmsaue
				04051655	Babelsberger Straße	-					04501153	Babelsberger Straße
				04051656	Hildegardstraße	-					04501151	Hildegardstraße
0406	CW 6	040617	Forst Grunewald	04061757	Forst Grunewald	Z 04200207/ G 04400729						

05 Spandau												
PRG ID alt	PRG Name alt	BZR ID alt	BZR Name alt	PLR ID alt	PLR Name alt	Modifikation → T = Teilung in … (PLR neu) Z = Zusammenlegung zu … (PLR neu) G = Anpassung Grenze	PRG ID neu	PRG Name neu	BZR ID neu	BZR Name neu	PLR ID neu	PLR Name neu
0501	SPA 1	050101	Hakenfelde	05010101	Hakenfelde Nord	T 05100101/ 03/04	0510	Spandau Mitte / Nord	051001	Hakenfelde	05100101	Hakenfelde Nord
											05100103	Mertensstraße
											05100104	Maselake
				05010102	Goltzstraße	G 05100103					05100102	Am Forstacker
				05010103	Amorbacher Weg	-					05100105	Amorbacher Weg
		050102	Falkenhagener Feld	05010204	Griesingerstraße	-			051002	Falkenhagener Feld	05100206	Griesingerstraße
				05010205	An der Tränke	-					05100207	An der Tränke
				05010206	Gütersloher Weg	-					05100208	Im Spektefeld
				05010207	Darbystraße	-					05100209	Westerwaldstraße
				05010208	Germersheimer Platz	-					05100210	Germersheimer Platz
				05010209	An der Kappe	-					05100211	An der Kappe
		050103	Spandau Mitte	05010310	Eckschanze	-			051003	Spandau Mitte	05100312	Eckschanze
				05010311	Eiswerder	-					05100313	Eiswerder
				05010312	Kurstraße	-					05100314	Kurstraße
				05010313	Ackerstraße	-					05100315	Ackerstraße
				05010314	Carl-Schurz-Straße	G 05100316					05100316	Carl-Schurz-Straße
				05010339	Freiheit	G 05100317					05100317	Freiheit
0502	SPA 2	050204	Brunsbütteler Damm	05020415	Isenburger Weg	-	0520	Wilhelmstadt / Staaken	052004	Brunsbütteler Damm	05200418	Isenburger Weg
				05020416	Am Heideberg	-					05200419	Am Heideberg
				05020417	Staakener Straße	-					05200420	Staakener Straße
				05020418	Spandauer Straße	-					05200421	Spandauer Straße
				05020419	Magistratsweg	G 05200423					05200423	Magistratsweg
				05020420	Werkstraße	G 05200422					05200422	Werkstraße
		050205	Heerstraße Nord	05020521	Döberitzer Weg	-			052005	Heerstraße	05200524	Döberitzer Weg
				05020522	Pillnitzer Weg	T 05200525/26					05200525	Pillnitzer Weg
											05200526	Rudolf-Wissell-Groß-siedlung
				05020523	Maulbeerallee	-					05200527	Maulbeerallee
				05020524	Weinmeisterhornweg	-					05200528	Weinmeisterhornweg
		050206	Wilhelmstadt	05020625	Borkumer Straße	-			052006	Wilhelmstadt	05200629	Borkumer Straße
				05020626	Adamstraße	T 05200630/31					05200630	Wilhelmstadt West
											05200631	Wilhelmstadt Ost

				05020627	Tiefwerder	-					05200632	Tiefwerder
				05020628	Graetschelsteig	-					05200633	Graetschelsteig
				05020629	Börnicker Straße	-					05200634	Börnicker Straße
0503	SPA 3	050307	Haselhorst	05030730	Zitadellenweg	T 05300735/36	0530	Haselhorst / Siemensstadt	053007	Haselhorst	05300735	Haveleck
											05300736	Zitadellenweg
				05030731	Gartenfelder Straße	-					05300737	Gartenfelder Straße
		050308	Siemensstadt	05030832	Rohrdamm	T 05300838/ 39/41			053008	Siemensstadt	05300838	Gartenfeld
											05300839	Rohrdamm
											05300841	Siemensdamm
				05030833	Motardstraße	-					05300840	Nonnendammallee
0504	SPA 4	050409	Gatow/Kladow	05040934	Alt-Gatow	Z 05400942	0540	Gatow / Kladow	054009	Gatow/Kladow	05400942	Alt-Gatow
				05040935	Groß-Glienicker Weg	Z 05400942						
				05040936	Jägerallee	-					05400943	Jägerallee
				05040937	Kladower Damm	-					05400944	Kladower Damm
				05040938	Kafkastraße	-					05400945	Kafkastraße

06 Steglitz-Zehlendorf												
PRG ID alt	PRG Name alt	BZR ID alt	BZR Name alt	PLR ID alt	PLR Name alt	Modifikation → T = Teilung in … (PLR neu) Z = Zusammenlegung zu … (PLR neu) G = Anpassung Grenze	PRG ID neu	PRG Name neu	BZR ID neu	BZR Name neu	PLR ID neu	PLR Name neu
0601	Region A	060101	Schloßstraße	06010101	Fichtenberg	-	0610	Steglitz	061001	Schloßstraße	06100101	Fichtenberg
				06010102	Schloßstraße	-					06100102	Schloßstraße
				06010103	Markelstraße	-					06100103	Markelstraße
		060102	Albrechtstraße	06010204	Munsterdamm	-			061002	Albrechtstraße	06100204	Munsterdamm
				06010205	Südende	-					06100205	Südende
				06010206	Stadtpark	-					06100206	Stadtpark
				06010207	Mittelstraße	-					06100207	Mittelstraße
				06010208	Bergstraße	-					06100208	Bergstraße
				06010209	Feuerbachstraße	-					06100209	Feuerbachstraße
				06010210	Bismarckstraße	-					06100210	Bismarckstraße
0602	Region B	060203	Lankwitz	06020301	Alt-Lankwitz	-	0620	Lankwitz/ Lichterfelde Ost	062003	Lankwitz	06200311	Alt-Lankwitz
				06020302	Komponistenviertel Lankwitz	-					06200312	Komponistenviertel Lankwitz
				06020303	Lankwitz Kirche	-					06200313	Lankwitz Kirche
				06020304	Kaiser-Wilhelm-Straße	-					06200314	Kaiser-Wilhelm-Straße
				06020305	Gemeindepark Lank-witz	T 06200315/ 16					06200315	Gallwitzallee
											06200316	Belßstraße
				06020306	Lankwitz Süd	-					06200317	Lankwitz Süd
		060204	Ostpreußendamm	06020407	Thermometersiedlung	T 06200418/ 19			062004	Ostpreußen-damm	06200418	Landweg
											06200419	Thermometersiedlung
				06020408n	Lichterfelde Süd	G 06200420					06200420	Lichterfelde Süd
				06020409	Königsberger Straße	-					06200421	Königsberger Straße
				06020410	Oberhofer Platz	-					06200422	Oberhofer Platz
				06020411	Schütte-Lanz-Straße	-					06200423	Schütte-Lanz-Straße
0603	Region C	060305	Teltower Damm	06030501	Berlepschstraße	-	0630	Zehlendorf Süd/ Lich-terfelde West	063005	Teltower Damm	06300524	Berlepschstraße
				06030502	Zehlendorf Süd	-					06300525	Zehlendorf Süd
				06030503	Zehlendorf Mitte	T 06300526/ 27					06300526	Zehlendorf Mitte
											06300527	Sundgauer Straße
				06030504	Teltower Damm	-					06300528	Teltower Damm
		060306	Drakestraße	06030605	Botanischer Garten	-			063006	Drakestraße	06300629	Botanischer Garten

				06030606	Hindenburgdamm	-					06300630	Hindenburgdamm
				06030607	Goerzwerke	-					06300631	Goerzwerke
				06030608	Schweizer Viertel	-					06300632	Schweizer Viertel
				06030609	Augustaplatz	-					06300633	Augustaplatz
				06030610	Lichterfelde West	-					06300634	Lichterfelde West
0604	Region D	060407	Zehlendorf Süd-west	06040701	Wannsee	-	0640	Zehlendorf Nord/ Wannsee	064007	Zehlendorf Südwest	06400735	Wannsee
				06040702	Düppel	-					06400736	Düppel
				06040703	Nikolassee	-					06400737	Nikolassee
		060408	Zehlendorf Nord	06040804	Krumme Lanke	-			064008	Zehlendorf Nord	06400838	Krumme Lanke
				06040805	Fischerhüttenstraße	-					06400839	Fischerhüttenstraße
				06040806	Fischtal	-					06400840	Fischtal
				06040807	Zehlendorf Eiche	-					06400841	Zehlendorf Eiche
				06040808	Hüttenweg	-					06400842	Hüttenweg
				06040809	Thielallee	-					06400843	Thielallee
				06040810	Dahlem	-					06400844	Dahlem

07 Tempelhof-Schöneberg												
PRG ID alt	PRG Name alt	BZR ID alt	BZR Name alt	PLR ID alt	PLR Name alt	Modifikation → T = Teilung in … (PLR neu) Z = Zusammenlegung zu … (PLR neu) G = Anpassung Grenze	PRG ID neu	PRG Name neu	BZR ID neu	BZR Name neu	PLR ID neu	PLR Name neu
0701	Schöneberg-Nord	070101	Schöneberg-Nord	07010101	Wittenbergplatz/ Viktoria-Luise-Platz	-	0710	Schöneberg Nord	071001	Schöneberg Nordwest	07100101	Wittenbergplatz
				07010102	Nollendorfplatz	T 07100102/03					07100102	Kalckreuthstraße
				07010103	Barbarossaplatz	-					07100103	Frobenstraße
									071002	Schöneberg Nordost	07100204	Barbarossaplatz
				07010104	Dennewitzplatz	T 07100205/06					07100205	Alvenslebenstraße
											07100206	Großgörschenstraße
0702	Schöneberg-Süd	070202	Schöneberg-Süd	07020201	Bayerischer Platz	-	0720	Schöneberg Süd	072003	Schöneberg Südwest	07200307	Bayerischer Platz
				07020202	Volkspark (Rudolf-Wilde-Park)	-					07200308	Volkspark (Rudolph-Wilde-Park)
				07020203	Kaiser-Wilhelm-Platz	T 07200409/ 10/11			072004	Schöneberg Südost	07200409	Belziger Straße
											07200410	Feurigstraße
											07200411	Julius-Leber-Brücke
				07020204	Schöneberger Insel	T 07200412/ 13/14					07200412	Schöneberger Linse
											07200413	Cheruskerstraße
											07200414	Hohenfriedbergstraße
0703	Friedenau	070303	Friedenau	07030301	Friedenau	T 07300515/ 16/17	0730	Friedenau	073005	Friedenau West	07300515	Taunusstraße
											07300516	Odenwaldstraße
											07300517	Perelsplatz
				07030302	Ceciliengärten	-			073006	Friedenau Ost	07300618	Ceciliengärten
				07030303	Grazer Platz	-					07300619	Grazer Platz
0704	Tempelhof	070404	Tempelhof	07040401	Neu-Tempelhof	T 07400720/21	0740	Tempelhof	074007	Tempelhof Nord	07400720	Gontermannstraße
											07400721	Paradestraße
				07040402	Lindenhofsiedlung	-			074008	Tempelhof Südwest	07400822	Lindenhofsiedlung
				07040403	Manteuffelstr.	T 07400823/ 24/25					07400823	Wittekindstraße
											07400824	Bosepark
											07400825	Friedrich-Karl-Straße
				07040404	Marienhöhe	-					07400826	Marienhöhe
				07040405	Rathaus Tempelhof	-			074009	Tempelhof Südost	07400927	Rathaus Tempelhof
				07040406	Germaniagarten	-					07400928	Germaniagarten
0705	Mariendorf	070505	Mariendorf	07050501	Rathausstr.	T 07501029/30	0750	Mariendorf	075010	Mariendorf Nord	07501029	Ringstraße
											07501030	Machonstraße

				07050502	Fritz-Werner-Str.	-			075011	Mariendorf Süd	07501133	Fritz-Werner-Straße
				07050503	Eisenacher Str.	-			075010	Mariendorf Nord	07501031	Eisenacher Straße
				07050504	Imbrosweg	-					07501032	Imbrosweg
				07050505	Hundsteinweg	-			075011	Mariendorf Süd	07501134	Hundsteinweg
				07050506	Birnhornweg	-					07501135	Birnhornweg
0706	Marienfelde	070606	Marienfelde	07060601	Marienfelder Allee Nordwest	-	0760	Marienfelde/ Lichtenrade	076012	Marienfelde Nord	07601236	Marienfelder Allee Nordwest
				07060602	Kirchstr.	-					07601237	Kirchstraße
				07060603	Marienfelde Nord-ost	-					07601238	Marienfelde Nordost
				07060604	Marienfelde Süd	T 07601339/ 40/41			076013	Marienfelde Süd	07601339	Tirschenreuther Ring West
											07601340	Tirschenreuther Ring Ost
											07601341	Diedersdorfer Weg
0707	Lichtenrade	070707	Lichtenrade	07070701	Kettinger Str./Schil-lerstr.	-			076014	Lichtenrade Nord	07601442	Kettinger Straße
				07070702	Alt-Lichtenrade/ Töpchiner Weg	-					07601443	Töpchiner Weg
				07070703	John-Locke-Str.	-			076015	Lichtenrade Süd	07601544	John-Locke-Straße
				07070704	Nahariyastr.	-					07601545	Nahariyastraße
				07070705	Franziusweg/ Rohr-bachstr.	-					07601546	Franziusweg
				07070706	Horstwalder Str./ Paplitzer Str.	-					07601547	Horstwalder Straße
				07070707	Wittelsbacherstr.	-					07601548	Wittelsbacherstraße

08 Neukölln												
PRG ID alt	PRG Name alt	BZR ID alt	BZR Name alt	PLR ID alt	PLR Name alt	Modifikation → T = Teilung in … (PLR neu) Z = Zusammenlegung zu … (PLR neu) G = Anpassung Grenze	PRG ID neu	PRG Name neu	BZR ID neu	BZR Name neu	PLR ID neu	PLR Name neu
0801	Neukölln	080101	Schillerprome-nade	08010115	Hasenheide	ZG 08100101	0810	Neukölln	081001	Schillerprome-nade	08100101	Hasenheide
				08010116	Wissmannstraße	ZG 08100101						
				08010117	Schillerpromenade	TG 08100102/03					08100102	Schillerpromenade Nord
											08100103	Schillerpromenade Süd
				08010118	Silbersteinstraße	TG 08100104/05					08100104	Wartheplatz
											08100105	Silbersteinstraße
		080102	Neuköllner Mitte/Zentrum	08010211	Flughafenstraße	-			081002	Neuköllner Mitte/Zentrum	08100206	Flughafenstraße
				08010212	Rollberg	-					08100207	Rollberg
				08010213	Körnerpark	-					08100208	Körnerpark
				08010214	Glasower Straße	-					08100209	Glasower Straße
		080103	Reuterstraße	08010301	Reuterkiez	T 08100310/ 11/12			081003	Reuterstraße	08100310	Maybachufer
											08100311	Reuterplatz
											08100312	Weichselplatz
				08010302	Bouchéstraße	-					08100313	Bouchéstraße
				08010303	Donaustraße	-					08100314	Donaustraße
		080104	Rixdorf	08010404	Rixdorf	T 08100415/ 16/17			081004	Rixdorf	08100415	Ganghoferstraße
											08100416	Alt-Rixdorf
											08100417	Braunschweiger Straße
				08010405	Hertzbergplatz	Z 08100418					08100418	Hertzbergplatz
				08010406	Treptower Straße Nord	-					08100419	Treptower Straße Nord
				08010407	Gewerbegebiet Ederstraße	Z 08100418						
		080105	Köllnische Heide	08010508	Weiße Siedlung	-			081005	Köllnische Heide	08100520	Weiße Siedlung
				08010509	Schulenburgpark	Z 08100521					08100521	Schulenburgpark
				08010510	Gewerbegebiet Köllnische Heide	Z 08100521						
0802	Britz/Buckow	080206	Britz	08020619	Buschkrugallee Nord	T 08200622/23	0820	Britz/Buckow	082006	Britz Nord	08200622	Jahnstraße
											08200623	Park am Buschkrug
				08020620	Tempelhofer Weg	G 08200624					08200624	Tempelhofer Weg

				08020621	Mohriner Allee Nord	G 08200725			082007	Britz	08200725	Mohriner Allee Nord
				08020622	Parchimer Allee	T 08200726/27					08200726	Hufeisensiedlung
											08200727	Parchimer Allee Süd
				08020623	Ortolanweg	-					08200728	Ortolanweg
				08020624	Britzer Garten	G 08200729					08200729	Britzer Garten
				08020625	Handwerker-Sied-lung	-					08200730	Handwerker-Sied-lung
		080207	Buckow	08020726	Buckow West	-			082008	Buckow	08200831	Buckow West
				08020727	Buckow Mitte	-					08200832	Buckow Mitte
				08020728	Buckow Ost	-					08200833	Buckow Ost
0803	Gropiusstadt	080308	Gropiusstadt	08030829	Gropiusstadt Nord	-	0830	Gropiusstadt	083009	Gropiusstadt West	08300934	Gropiusstadt Nord-West
				08030830	Gropiusstadt Süd	-					08300935	Gropiusstadt Süd-West
				08030831	Gropiusstadt Ost	T 08301036/37			083010	Gropiusstadt Ost	08301036	Gropiusstadt Mitte
											08301037	Gropiusstadt Süd-Ost
0804	Buckow Nord/Rudow	080409	Buckow Nord	08040932	Goldhähnchenweg	-	0840	Buckow Nord/Rudow	084011	Buckow Nord	08401138	Goldhähnchenweg
				08040933	Vogelviertel Süd	-					08401139	Vogelviertel Süd
				08040934	Vogelviertel Nord	-					08401140	Vogelviertel Nord
		080410	Rudow	08041035	Blumenviertel	-			084012	Rudow	08401241	Blumenviertel
				08041036	Zittauer Straße	-					08401242	Zittauer Straße
				08041037	Alt-Rudow	-					08401243	Alt-Rudow
				08041038	Waßmannsdorfer Chaussee	-					08401244	Waßmannsdorfer Chaussee
				08041039	Frauenviertel	-					08401245	Frauenviertel
				08041040	Waltersdorfer Chaussee Ost	-					08401246	Waltersdorfer Chaussee Ost

09 Treptow-Köpenick												
PRG ID alt	PRG Name alt	BZR ID alt	BZR Name alt	PLR ID alt	PLR Name alt	Modifikation → T = Teilung in … (PLR neu) Z = Zusammenlegung zu … (PLR neu) G = Anpassung Grenze	PRG ID neu	PRG Name neu	BZR ID neu	BZR Name neu	PLR ID neu	PLR Name neu
0901	Treptow-Köpenick 1	090101	Alt-Treptow	09010101	Elsenstraße	Z 09100101	0910	Treptow-Köpenick 1	091001	Alt-Treptow	09100101	Alt-Treptow
				09010102	Am Treptower Park Nord	Z 09100101						
		090102	Plänterwald	09010201	Am Treptower Park Süd	-			091002	Plänterwald	09100202	Plänterwald West
				09010202	Köpenicker Land-straße	-					09100203	Plänterwald Ost
		090103	Baumschulenweg	09010301	Baumschulen-straße	T 09100304/ 05			091003	Baumschulen-weg	09100305	Baumschulenweg Ost
											09100304	Baumschulenweg West
				09010302	Späthsfelde	-					09100306	Späthsfelde
		090104	Johannisthal	09010401	Johannisthal West	-			091004	Johannisthal	09100407	Johannisthal West
				09010402	Johannisthal Ost	T 09100408/ 09					09100408	Johannisthal Ost
											09100409	Landschaftspark Adlershof
0902	Treptow-Köpenick 2	090205	Oberschöne-weide	09020501	Oberschöneweide West	-	0920	Treptow-Köpenick 2	092005	Oberschöne-weide	09200510	Helmholtz-Kiez
				09020502	Oberschöneweide Ost	T 09200511/ 12					09200511	Griechischer Park
											09200512	Wuhlheide
		090206	Niederschöne-weide	09020601	Schnellerstraße	-			092006	Niederschöne-weide	09200613	Bahnhof Schöne-weide
				09020602	Oberspree	-					09200614	Oberspree
		090207	Adlershof	09020701	Adlershof West	-			092007	Adlershof	09200715	Wista
				09020702	Adlershof Ost	T 09200716/17					09200717	Dörpfeldstraße Ost
											09200716	Dörpfeldstraße West
		090208	Köllnische Vor-stadt/Spindlers-feld	09020801	Spindlersfeld	-			092008	Köllnische Vorstadt/ Spindlers-feld	09200818	Spindlersfeld
				09020802	Köllnische Vor-stadt	-					09200819	Köllnische Vor-stadt
0903		090309	Altglienicke	09030901	Dorf Altglienicke	T 09300920/ 21	0930		093009	Altglienicke	09300920	Dorf Altglienicke

	Treptow-Köpenick 3							Treptow-Köpenick 3			09300921	Preußen Siedlung
				09030902	Wohngebiet II	-					09300922	Kosmos Viertel
				09030903	Kölner Viertel	-					09300923	Kölner Viertel
		090310	Bohnsdorf	09031001	Bohnsdorf	T 09301024/ 25			093010	Bohnsdorf	09301024	Falkenberg
											09301025	Alt-Bohnsdorf
		090311	Grünau	09031101	Grünau	-			093011	Grünau	09301126	Grünau
		090312	Schmöck-witz/Karolinen-hof/Rauchfangs-werder	09031201	Karolinenhof	-			093012	Schmöckwitz	09301227	Karolinenhof
				09031202	Schmöck-witz/Rauchfangs-werder	-					09301228	Schmöck-witz/Rauchfangs-werder
0904	Treptow-Köpenick 4	090413	Köpenick Süd	09041301	Kietzer Feld/Nachtheide	-	0940	Treptow-Köpenick 4	094013	Köpenick Süd	09401329	Kietzer Feld/ Nachtheide
				09041302	Wendenschloß	-					09401330	Wendenschloß
		090414	Allende-Viertel	09041401	Allende I	-			094014	Allende-Vier-tel	09401431	Allende I
				09041402	Siedlung Käm-mereiheide	-					09401432	Siedlung Käm-mereiheide
				09041403	Allende II	-					09401433	Allende II
		090415	Altstadt Kietz	09041501	Altstadt Kietz	-			094015	Altstadt Köpe-nick	09401534	Altstadt Köpenick
		090416	Müggelheim	09041601	Müggelheim	-			094016	Müggelheim	09401635	Müggelheim
0905	Treptow-Köpenick 5	090517	Friedrichshagen	09051701	Hirschgarten	G 09501736	0950	Treptow-Köpenick 5	095017	Friedrichsha-gen	09501736	Hirschgarten
				09051702	Bölschestraße	G 09501737					09501737	Alt-Friedrichsha-gen
		090518	Rahnsdorf/Hes-senwinkel	09051801	Rahnsdorf/Hes-senwinkel	-			095018	Rahnsdorf	09501838	Rahnsdorf
		090519	Dammvorstadt	09051901	Dammvorstadt	T 09501939/ 40/41			095019	Damm-vor-stadt	09501939	Bahnhofstraße
											09501940	Güterbahnhof Köpenick
											09501941	Friedrichshage-ner Straße
		090520	Köpenick Nord	09052001	Köpenick Nord	T 09502042/ 43			095020	Köpenick Nord	09502042	Mittelheide
											09502043	Dammheide

10 Marzahn-Hellersdorf												
PRG ID alt	PRG Name alt	BZR ID alt	BZR Name alt	PLR ID alt	PLR Name alt	Modifikation → T = Teilung in … (PLR neu) Z = Zusammenlegung zu … (PLR neu) G = Anpassung Grenze	PRG ID neu	PRG Name neu	BZR ID neu	BZR Name neu	PLR ID neu	PLR Name neu
1001	Marzahn	100101	Marzahn Nord	10010101	Marzahn West	-	1010	Marzahn	101001	Marzahn Nord	10100101	Marzahn West
				10010102	Havemannstraße	T 10100102/ 03/04					10100102	Rosenbecker Straße
											10100103	Wittenberger Straße
											10100104	Golliner Straße
		100102	Marzahn Mitte	10010203	Gewerbegebiet Bitterfelder Straße	-			101002	Marzahn Mitte	10100205	Gewerbegebiet Bitterfelder Straße
				10010204	Wuhletalstraße	-					10100206	Wuhletalstraße
				10010205	Marzahn Ost	-					10100207	Ahrensfelder Berge
				10010206	Ringkolonnaden	T 10100208/ 09					10100208	Bürgerpark
											10100209	Lea-Grundig-Straße
				10010207	Marzahner Promenade	-					10100210	Marzahner Promenade
		100103	Marzahn Süd	10010308	Marzahner Chaussee	-			01003	Marzahn Süd	10100311	Marzahner Chaussee
				10010309	Springpfuhl	-					10100312	Springpfuhl
				10010310	Alt-Marzahn	T 10100313/ 14/15					10100313	Alt-Marzahn
											10100314	Auersbergstraße
											10100315	Bärenstein
				10010311	Landsberger Tor	-					10100316	Landsberger Tor
1002	Hellersdorf	100204	Hellersdorf Nord	10020412	Alte Hellersdorfer Straße	-	1020	Hellersdorf	102004	Hellersdorf Nord	10200417	Zossener Straße
				10020413	Gut Hellersdorf	T 10200418/ 19/20					10200418	Kyritzer Straße
											10200419	Havelländer Ring
											10200420	Gut Hellersdorf
				10020414	Helle Mitte	-					10200421	Helle Mitte
				10020415	Hellersdorfer Promenade	-					10200422	Hellersdorfer Promenade
				10020416	Böhlener Straße	-					10200423	Böhlener Straße
		100205	Hellersdorf Ost	10020517	Adele-Sandrock-Straße	-			102005	Hellersdorf Ost	10200524	Adele-Sandrock Straße
				10020518	Schleipfuhl	-					10200525	Schleipfuhl

				10020519	Boulevard Kastanienallee	-					10200526	Boulevard Kastanienallee
		100206	Hellersdorf Süd	10020620	Kaulsdorf Nord II	-			102006	Hellersdorf Süd	10200627	Am Kienberg
				10020621	Gelbes Viertel	-					10200628	Neue Grottkauer Straße
				10020622	Kaulsdorf Nord I	-					10200629	Teterower Ring
				10020623	Rotes Viertel	-					10200630	Cecilienplatz
1003	Biesdorf	100307	Biesdorf	10030724	Oberfeldstraße	-	1030	Biesdorf	103007	Biesdorf	10300731	Oberfeldstraße
				10030725	Buckower Ring	-					10300732	Buckower Ring
				10030726	Alt-Biesdorf	-					10300733	Alt-Biesdorf
				10030727	Biesdorf Süd	-					10300734	Biesdorf Süd
1004	Kaulsdorf/Mahlsdorf	100408	Kaulsdorf	10040828	Kaulsdorf Nord	-	1040	Kaulsdorf/ Mahlsdorf	104008	Kaulsdorf	10400835	Kaulsdorf Nord
				10040829	Alt-Kaulsdorf	-					10400836	Alt-Kaulsdorf
				10040830	Kaulsdorf Süd	-					10400837	Kaulsdorf Süd
		100409	Mahlsdorf	10040931	Mahlsdorf Nord	-			104009	Mahlsdorf	10400938	Mahlsdorf Nord
				10040932	Alt-Mahlsdorf	-					10400939	Alt-Mahlsdorf
				10040933	Mahlsdorf Süd	T 10400940/ 41					10400940	Elsensee
											10400941	Pilgramer Straße

11 Lichtenberg												
PRG ID alt	PRG Name alt	BZR ID alt	BZR Name alt	PLR ID alt	PLR Name alt	Modifikation → T = Teilung in … (PLR neu) Z = Zusammenlegung zu … (PLR neu) G = Anpassung Grenze	PRG ID neu	PRG Name neu	BZR ID neu	BZR Name neu	PLR ID neu	PLR Name neu
1101	Hohenschönhausen Nord	110101	Malchow, Wartenberg und Falkenberg	11010101	Dorf Malchow	Z 11100101	1110	Hohenschön- hausen Nord	111001	Malchow, Wartenberg und Falkenberg	11100101	Dörfer Malchow-Wartenberg
				11010102	Dorf Wartenberg	Z 11100101						
				11010103	Dorf Falkenberg	-					11100102	Dorf Falkenberg
		110102	Neu- Hohen-schönhausen Nord	11010204	Falkenberg Ost	-			111002	Neu-Hohen-schön-hausen Nord	11100203	Falkenberg Ost
				11010205	Falkenberg West	-					11100204	Falkenberg West
				11010206	Wartenberg Süd	-					11100205	Wartenberg Süd
				11010207	Wartenberg Nord	-					11100206	Wartenberg Nord
		110103	Neu-Hohen-schönhausen Süd	11010308	Zingster Straße Ost	-			111003	Neu-Hohen-schönhausen Süd	11100307	Zingster Straße Ost
				11010309	Zingster Straße West	-					11100308	Zingster Straße West
				11010310	Mühlengrund	-					11100309	Mühlengrund
1102	Hohenschönhausen Süd	110204	Alt-Hohenschönhausen Nord	11020411	Malchower Weg	-	1120	Hohenschönhausen Süd	112004	Alt-Hohenschönhausen Nord	11200410	Malchower Weg
				11020412	Hauptstraße	-					11200411	Hauptstraße
		110205	Alt-Hohenschönhausen Süd	11020513	Orankesee	-			112005	Alt-Hohenschönhausen Süd	11200512	Orankesee
				11020514	Große-Leege-Straße	-					11200513	Große-Leege-Straße
				11020515	Landsberger Allee	-					11200514	Landsberger Allee
				11020516	Weiße Taube	-					11200515	Weiße Taube
1103	Lichtenberg Nord	110306	Fennpfuhl	11030617	Hohenschönhausener Straße	-	1130	Lichtenberg Nord	113006	Fennpfuhl	11300616	Hohenschönhausener Straße
				11030618	Fennpfuhl West	T 11300617/ 18/19					11300618	Storkower Bogen
											11300619	Rudolf-Seiffert-Park
											11300617	Fennpfuhlpark
				11030619	Fennpfuhl Ost	-					11300620	Fennpfuhl Ost
		110307	Alt-Lichtenberg	11030720	Herzbergstraße	-			113007	Alt-Lichtenberg	11300721	Herzbergstraße
				11030721	Rüdigerstraße	T 11300722/ 23/24/25					11300723	Bornitzstraße
											11300722	Rathaus Lichtenberg

											11300724	Roedeliusplatz
											11300725	Nibelungenviertel
		110308	Frankfurter Allee Süd	11030824	Frankfurter Allee Süd	-			113008	Frankfurter Allee Süd	11300826	Frankfurter Allee Süd
1104	Lichtenberg Mitte	110409	Neu-Lichtenberg	11040925	Victoriastadt	-	1140	Lichtenberg Mitte	114009	Neu-Lichtenberg	11400927	Victoriastadt
				11040926	Weitlingstraße	T 11400928/ 29/30/31					11400931	Massower Straße
											11400928	Nöldnerplatz
											11400929	Weitlingkiez
											11400930	Zachertstraße
		110410	Friedrichsfelde Nord	11041022	Rosenfelder Ring	-			114010	Friedrichsfelde Nord	11401032	Rosenfelder Ring
				11041023	Gensinger Straße	-					11401033	Gensinger Straße
				11041027	Tierpark	-					11401034	Tierpark
		110411	Friedrichsfelde Süd	11041128	Sewanstraße	T 11401135/ 36/37			114011	Friedrichsfelde Süd	11401136	Volkradstraße
											11401135	Dolgenseestraße
											11401137	Erieseering
1105	Lichtenberg Süd	110512	Rummelsburger Bucht	11051229	Rummelsburg	-	1150	Lichtenberg Süd	115012	Rummelsburger Bucht	11501238	Rummelsburg
		110513	Karlshorst	11051330	Karlshorst West	-			115013	Karlshorst	11501339	Karlshorst West
				11051331	Karlshorst Nord	-					11501340	Karlshorst Nord
				11051332	Karlshorst Süd	-					11501341	Karlshorst Süd

12 Reinickendorf												
PRG ID alt	PRG Name alt	BZR ID alt	BZR Name alt	PLR ID alt	PLR Name alt	Modifikation → T = Teilung in … (PLR neu) Z = Zusammenlegung zu … (PLR neu) G = Anpassung Grenze	PRG ID neu	PRG Name neu	BZR ID neu	BZR Name neu	PLR ID neu	PLR Name neu
1210	Reinickendorf Ost	121031	Ost 1 - Reginhardstr.	12103115	Breitkopfbecken	-	1210	Reinickendorf Ost	121001	Ost 1 - Reginhardstraße	12100103	Breitkopfbecken
				12103116	Hausotterplatz	-					12100102	Hausotterplatz
				12103117	Letteplatz	-					12100101	Letteplatz
		121032	Ost 2 Alt-Reinickendorf	12103218	Teichstraße	-			121002	Ost 2 - Alt-Reinickendorf	12100205	Teichstraße
				12103219	Schäfersee	-					12100204	Schäfersee
				12103220	Humboldtstraße	-					12100206	Humboldtstraße
1221	Tegel	122141	West 1 Tegel-Süd/ Flughafensee	12214125	Waldidyll/Flughafensee	T 12200411/ 12/14 G 12200411	1220	Tegel	122004	West 1 - Tegel-Süd/Flughafensee	12200412	Waldidyll/Flughafensee
											12200411	Schumacher-Quartier
											12200414	TXL
				12214126	Tegel Süd	-					12200413	Tegel Süd
		122144	West 4 - Auguste- Viktoria-Allee	12214421	Reinickes Hof	-			122003	West 4 - Auguste-Viktoria-Allee	12200307	Reinickes Hof
				12214422	Klixstraße	-					12200310	Klixstraße
				12214423	Mellerbogen	-					12200308	Mellerbogen
				12214424	Scharnweberstraße	G 12200309					12200309	Scharnweberstraße
		122145	West 5 - Tegel/ Tegeler Forst	12214527	Alt-Tegel	-			122005	West 5 - Tegel	12200515	Alt-Tegel
				12214528	Tegeler Forst	Z 12400619 G 12400616						
		122242	West 2 - Heiligensee/ Konradshöhe	12224229	Konradshöhe/ Tegelort	G 12400616	1240	Grüner Norden	124006	West 2 - Heiligensee/Konradshöhe	12400616	Konradshöhe/ Tegelort
				12224230	Heiligensee	T 12400617/ 18/19					12400617	Alt-Heiligensee
											12400619	Heiligensee
											12400618	Heiligensee Nord
1223	Frohnau/Hermsdorf	122311	Nord 1 - Frohnau/ Hermsdorf	12231101	Hermsdorf	T 12400722/23			124007	Nord 1 - Frohnau/ Hermsdorf	12400722	Hermsdorf West
											12400723	Hermsdorf Ost/ Waldsee
				12231102	Frohnau	T 12400720/21					12400720	Frohnau West
											12400721	Frohnau Ost
1230		123012		12301203	Wittenau Süd	T 12500926 / 30	1250		125009		12500930	Wittenau Mitte

	Waidmanns-lust		Nord 2 - Waid-mannslust/ Wittenau/ Lübars					Wit-tenau/Bor-sigwalde		Nord 2 – Waid-manns-lust/ Wittenau/ Lübars	12500926	Wittenau Süd
				12301204	Wittenau Nord	-					12500927	Wittenau Nord
				12301205	Waidmannslust	-					12500928	Waidmannslust
				12301206	Lübars	-					12500929	Lübars
		123021	MV 1 - Mär-kisches Vier-tel	12302107	Schorfhei-destraße	G 12601236	1260	Märkisches Viertel	126012	MV Süd	12601236	Schorfheidestraße
				12302108	Märkisches Zentrum	G 12601134			126011	MV Nord	12601134	Märkisches Zent-rum
				12302109	Treuenbrietze-ner Straße	-					12601133	Treuenbrietzener Straße
				12302110	Dannenwalder Weg	-			126012	MV Süd	12601235	Dannenwalder Weg
		123022	MV 2 - Roll-bergesied-lung	12302211	Lübarser Straße	-			126010	Rollberge-siedlung	12601031	Lübarser Straße
				12302212	Rollbergesied-lung	-					12601032	Rollbergesiedlung
		123043	West 3 - Borsig-walde/ Freie Scholle	12304313	Borsigwalde	-	1250	Wit-tenau/Bor-sigwalde	125008	West 3 - Borsig-walde/Freie Scholle	12500825	Borsigwalde
				12304314	Zie-kowstraße/Freie Scholle	-					12500824	Ziekowstraße/Freie Scholle